SPRÁVA O HODNOTENÍ STRATEGICKÉHO DOKUMENTU

Spoločný program hospodárskeho rozvoja a sociálneho rozvoja obcí na území udržateľného mestského rozvoja Prešov na obdobie rokov 2023 - 2030 s výhľadom do roku 2035 „ PREŠOV 2030 “

podľa Prílohy č. 4 zákona NR SR č. 24/2006 Z. z. o posudzovaní vplyvov na ŽP a o zmene a doplnení niektorých zákonov v znení neskorších predpisov

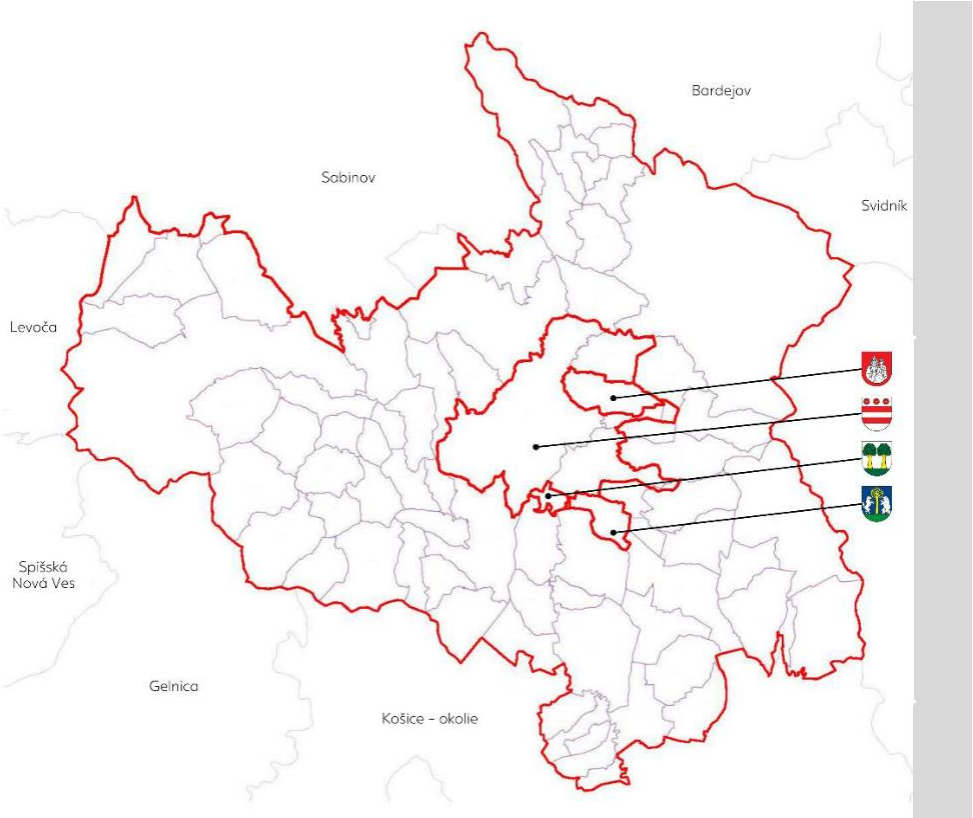

Máj 2024

OBSAH A ŠTRUKTÚRA SPRÁVY O HODNOTENÍ STRATEGICKÉHO DOKUMENTU

I. Základné údaje o obstarávateľovi 3
1. Označenie 3
2. Sídlo 3
3. Meno, priezvisko, adresa, telefónne číslo a iné kontaktné údaje oprávneného zástupcu obstarávateľa, od ktorého možno dostať relevantné informácie o strategickom dokumente a miesto na konzultácie 3
II. ZÁKLADNÉ ÚDAJE O STRATEGICKOM DOKUMENTE 3
1. Názov 3
2. Územie 15
3. Dotknuté obce 17
4. Dotknuté orgány 17
5. Schvaľujúci orgán 18
6. Obsah a hlavné ciele strategického dokumentu a jeho vzťah k iným strategickým dokumentom 18
6.1 Analytická časť 19
6.2 Strategická časť 20
6.3 Programová časť 23
6.4 Realizačná časť 23
6.5 Finančná časť 25
III. ZÁKLADNÉ ÚDAJE O SÚČASNOM STAVE ŽIVOTNÉHO PROSTREDIA DOTKNUTÉHO ÚZEMIA 27
1. Informácie o súčasnom stave životného prostredia vrátane zdravia a jeho pravdepodobný vývoj, ak sa strategický dokument nebude realizovať 27
2. Charakteristika životného prostredia vrátane zdravia v oblastiach, ktoré budú významne ovplyvnené 75
3. Environmentálne problémy vrátane zdravotných problémov, ktoré sú relevantné z hľadiska strategického dokumentu. 83
4. Environmentálne ciele vrátane zdravotných cieľov zistených na medzinárodnej, národnej a inej úrovni, ktoré sú relevantné z hľadiska strategického dokumentu, ako aj to, ako sa zohľadnili počas prípravy strategického dokumentu. 85
IV. ZÁKLADNÉ ÚDAJE O PREDPOKLADANÝCH VPLYVOV STRATEGICKÉHO DOKUMENTU VRÁTANE ZDRAVIA 87
1. Pravdepodobne významné environmentálne vplyvy na životné prostredie a vplyvy na zdravie (primárne, sekundárne, kumulatívne, synergické, krátkodobé, strednodobé, dlhodobé, trvalé, dočasné, pozitívne aj negatívne). 87
V. NAVRHOVANÉ OPATRENIA NA PREVENCIU, ELIMINÁCIU, MINIMALIZÁCIU A KOMPENZÁCIU VPLYVOV NA ŽIVOTNÉ PROSTREDIE A ZDRAVIE 89
1. Opatrenia na odvrátenie, zníženie alebo zmiernenie prípadných významných negatívnych vplyvov na životné prostredie vrátane zdravia, ktoré by mohli vyplynúť z realizácie strategického dokumentu. 89
VI. DÔVODY PRE VÝBER ZVAŽOVANÝCH ALTERNATÍV A POPIS TOHO, AKO BOLO VYKONANÉ VYHODNOTENIE VRÁTANE ŤAŽKOSTÍ S POSKYTOVANÍM POTREBNÝCH INFORMÁCIÍ, AKO NAPR. TECHNICKÉ NEDOSTATKY ALEBO NEURČITOSTI 91
VII. NÁVRH MONITOROVANIA ENVIRONMENTÁLNYCH VPLYVOV VRÁTANE VPLYVOV NA ZDRAVIE 93
VIII. PRAVDEPODOBNE VÝZNAMNÉ CEZHRANIČNÉ ENVIRONMENTÁLNE VPLYVY VRÁTANE VPLYVOV NA ZDRAVIE 95
IX. NETECHNICKÉ ZHRNUTIE POSKYTNUTÝCH INFORMÁCIÍ 95
X. INFORMÁCIA O EKONOMICKEJ NÁROČNOSTI (AK TO CHARAKTER A ROZSAH STRATEGICKÉHO DOKUMENTU UMOŽŇUJE) 95

I. Základné údaje o obstarávateľovi

1. Označenie
Mesto Prešov

2. Sídlo
Mesto Prešov, Mestský úrad vo Prešov, Hlavná 73, 080 01 Prešov, IČO 00327646

3. Meno, priezvisko, adresa, telefónne číslo a iné kontaktné údaje oprávneného zástupcu obstarávateľa, od ktorého možno dostať relevantné informácie o strategickom dokumente a miesto na konzultácie

Primátor:	Ing. František Oľha, primator@presov.sk
Zástupca primátora:	Ing. Viliam Sopko, prednosta@presov.sk
Adresa:	Mestský úrad v Prešove, Hlavná 73,
	080 01 Prešov
Tel./Fax:	+421 51 3100 101
e-mail:	mesto.radnica@presov.sk
Kompetentné osoby:	Ing. Magdaléna Artimová, vedúca útvaru analýz a stratégií
	Mestský úrad v Prešove, Hlavná 73, 080 01 Prešov,
	+421 51 3100 161, magdalena.artimova@presov.sk

II. ZÁKLADNÉ ÚDAJE O STRATEGICKOM DOKUMENTE

1. Názov

SPOLOČNÝ PROGRAM HOSPODÁRSKEHO ROZVOJA A SOCIÁLNEHO ROZVOJA OBCÍ NA ÚZEMÍ UDRŽATEĽNÉHO MESTSKÉHO ROZVOJA PREŠOV NA OBDOBIE ROKOV 2023 - 2030 S VÝHĽADOM DO ROKU 2035 (ďalej len PHRSR UMR Prešov)

Základné východiská PHRSR UMR Prešov

Spoločný program hospodárskeho rozvoja a sociálneho rozvoja obcí na území udržateľného mestského rozvoja Prešov na obdobie 2023 – 2030 (ďalej len „PREŠOV 2030“) s výhľadom do roku 2035 je strednodobým strategickým dokumentom, ktorý usmerňuje ďalší rozvoj územia udržateľného mestského rozvoja Prešov (ďalej len „UMR Prešov“), predovšetkým v oblasti hospodárskej, sociálnej a environmentálnej. UMR Prešov tvorí jadrové mesto Prešov a obce Haniska, Ľubotice a Záborské. UMR Prešov je súčasťou okresu Prešov, prirodzeného regiónu Šariš a Prešovského samosprávneho kraja.

Základné východiská pre spracovanie strategického dokumentu „Prešov 2030“ mesta Prešov a obcí tvoriacich územie udržateľného mestského rozvoja:

- končiaca platnosť súčasných strategických dokumentov, spracovaných v súlade so zákonom č. 539/2008 Z. z. o podpore regionálneho rozvoja v znení neskorších predpisov,
- návrh implementačného mechanizmu pre nové programové obdobie na roky 2021-2027 vo väzbe na čerpanie EÚ fondov, vychádzajúci z Nariadenia Európskeho parlamentu a Rady EÚ 2021/1060, čl. 28 a 29, podmieňujúci podporu integrovaného územného rozvoja z EÚ zdrojov na základe integrovaných územných stratégií,
- výstupy procesu monitorovania a hodnotenia realizácie aktuálnych strategických dokumentov mesta Prešov a dotknutých obcí, vrátane parciálnych sektorových strategických dokumentov a priemet priorít územia do nového spoločného strategického dokumentu a súčasne nového PHRSR Prešovského samosprávneho kraja a Integrovanej územnej stratégie Prešovského samosprávneho kraja.

Členovia UMR Prešov uzatvorili 28. 02. 2021 memorandum o spolupráci na vypracovaní Integrovanej územnej stratégie ako Spoločného programu hospodárskeho rozvoja a sociálneho rozvoja obcí na území udržateľného mestského rozvoja Prešov, ktorý nahrádza samostatné PHRSR obcí. Dokument je vypracovaný v súlade s vyššie citovaným zákonom č. 539/2008 Z. z. o podpore regionálneho rozvoja v znení neskorších predpisov a rešpektuje Nariadenie Európskeho parlamentu a Rady EÚ 2021/1060, čl. 28 a 29, vrátane využitia nástrojov územnej implementácie - integrovaných územných investícií.

Hlavné výzvy, na riešenie ktorých sa prioritne zameriava strategický dokument:

- demografické, sociálne a spoločenské výzvy,
- výzvy v oblasti fyzickej infraštruktúry, dopravy a životného prostredia,
- výzvy v oblasti hospodárskej,
- výzvy v oblasti dobrého spravovania územia a využitia medziobecnej a medzisektorovej spolupráce.

Dokument má povahu programu hospodárskeho rozvoja a sociálneho rozvoja skupiny obcí. Jedná sa o otvorený dokument, ktorý bude pravidelne monitorovaný, hodnotený a aktualizovaný vzhľadom na prebiehajúce zmeny.

PHRSR UMR Prešov spolu s územnoplánovacou dokumentáciou, je základným a kľúčovým dokumentom pre riadenie samospráv dotknutých obcí, ktorý vychádza z poznania situácie a konkrétnych potrieb

obyvateľov, podnikateľov, záujmových skupín a ďalších subjektov v území, formuluje svoju predstavu o budúcnosti spolu s činnosťami a projektmi na jej zabezpečenie. PHRSR koncepčne, systémovo analyzuje a určuje budúcnosť rozvoja spolu s činnosťami, investičnými projektmi so zdrojovým krytím na jej zabezpečenie. Vytvára rámec, ktorého naplnenie bude zárukou, že PHRSR nebude zbytočne rozsiahlym a len popisným zoznamom nereálnych zámerov (zoznamom vecí, na ktoré dotknuté obce nemajú peniaze), ale skutočným strategickým rozvojovým dokumentom s cieľom dosiahnuť rast životnej úrovne na predmetnom území. Impulzom pre vytvorenie spoločného územia UMR Prešov a spoločného strategického dokumentu bola najmä príprava na nové programové obdobie 2021 – 2027: nový metodický prístup Ministerstva investícií, regionálneho rozvoja a informatizácie SR (ďalej „MIRRI“) k tvorbe programov rozvoja; príprava a schválenie nových strategických a programových dokumentov na národnej a regionálnej úrovni a aktualizácia príslušných nariadení EÚ o podmienkach pre financovanie politiky súdržnosti. Obce majú povinnosť spracovať PHRSR obce, ktorá vyplýva zo Zákona NR SR č. 539/2008 Z. z. o podpore regionálneho rozvoja, ktorý v § 8a umožňuje spracovanie spoločného strategického dokumentu. Samosprávy majú záujem zlepšiť kvalitu života občanov a podmienky pre ekonomické aktivity na území, zaviesť systém strategického riadenia skupiny obcí, využiť inovatívne prístupy. Reagujú na zmeny podmienok - na nové právne, ekonomické a koncepčné rámce v programovom období EÚ 2021 - 2027, ale tiež na aktuálnu spoločenskú situáciu a jej dopad na rôzne oblasti života spoločnosti.

Samosprávy si uvedomujú potrebu spoločnej reakcie na výzvy a problémy územia, zohľadňujú tiež ekonomickú výhodnosť spracovania PHRSR skupiny obcí. Spracovanie PHRSR bolo motivované potrebou koncepčného cieľavedomého a transparentného riadenia a rozhodovania samosprávnych orgánov v snahe čo najefektívnejšie riešiť problémy a výzvy rozvoja územia. Existencia PHRSR obce je podmienkou pre získanie zdrojov zo štátneho rozpočtu a doplnkových zdrojov pre rozvojové projekty samospráv. Územie udržateľného mestského rozvoja Prešov okrem jadrového mesta Prešov, jeho 4 katastrálnych oblastí - Prešov, Solivar, Šalgovík a Nižná Šebastová, tvoria aj obce Haniska, Ľubotice a Záborské. Jadrové mesto Prešov je metropolou Šariša, okresným mestom a sídlom Úradu Prešovského samosprávneho kraja. Prešov je tretím najväčším mestom Slovenska a spolu s Košicami tvorí druhú najvýznamnejšiu mestskú slovenskú aglomeráciu s vysokou koncentráciou podnikateľských aktivít, priemyslu, školských a zdravotníckych zariadení aj kultúrnych cieľov. Leží na sútoku riek Torysa a Sekčov v Košickej kotline, obklopujú ho Slanské vrchy z východu a Šarišská vrchovina zo západu. Cez územie mesta vedú významné medzinárodné cestné a železničné trate smerom do Poľska a na Ukrajinu. Mesto Prešov sa v posledných

rokoch snažilo nastaviť systematické riešenie viacerých problémov (mnohé neboli dlhodobo riešené). V úvodnej fáze boli spracované viaceré strategické dokumenty a akčné plány (Stratégia udržateľného rozvoja dopravy mesta Prešov - Masterpán, Akčný plán udržateľného energetického rozvoja mesta Prešov, Základná stratégia adaptácie na nepriaznivé zmeny klímy na území mesta Prešov, Program odpadového hospodárstva, Komunitný plán rozvoja sociálnych služieb, Potenciál mesta Prešov v oblasti Smart City...) s cieľom premietnuť zistené dáta, výsledky analýz a formulovaných problémov do reálneho návrhu riešení, ktoré budú zohľadňovať jednak finančné možnosti mesta Prešov, ale taktiež možnosti využitia EÚ zdrojov. PHRSR UMR Prešov reaguje na problémy a potreby identifikované v citovaných dokumentoch, ako aj potreby obcí Haniska, Ľubotice a Záborské, ktoré tvorili základné východisko pri definovaní kľúčových problémov UMR Prešov. Tieto boli rámcovo rozčlenené do troch kľúčových oblastí/problémov, na riešenie ktorých je potrebné zamerať sa prioritne.

PHRSR UMR Prešov by mal:

- spĺňať požiadavky na tvorbu základných dokumentov podpory regionálneho rozvoja podľa Zákona NR SR č. 539/2008 Z. z o podpore regionálneho rozvoja v znení neskorších predpisov,
- plniť úlohu programovacích dokumentov pre implementáciu Európskych štrukturálnych a investičných fondov (ďalej „EŠIF“) na regionálnej a subregionálnej úrovni v období 2021 – 2027,
- byť kľúčovým nástrojom implementácie a územnej koordinácie napĺňania cieľov Národnej stratégie regionálneho rozvoja a implementácie Národného investičného plánu SR,
- byť nástrojom formulovania a implementácie smart stratégií obcí s využitím inovatívnych prístupov pre efektívnejšie zabezpečenie kvality života občanov,
- byť relevantným východiskom pre programové rozpočtovanie obcí a následný monitoring a hodnotenie v zmysle Zákona NR SR č. 583/2004 Z. z. o rozpočtových pravidlách územnej samosprávy v znení neskorších predpisov,
- byť nástrojom integrácie verejných politík na úrovni regiónov a obcí a zabezpečenia skutočného zvýšenia kvality života obyvateľov, zlepšenia podnikateľského prostredia a prístupu občanov k rozhodovaniu,
- byť nástrojom efektívneho, aktívneho a vecného zapojenia aktérov regionálneho rozvoja nielen z hľadiska definovania potrieb, priorít, cieľov, stratégií rozvoja skupiny obcí, ale aj implementácie, riadenia a monitorovania stratégií,
- podporovať vytváranie systému integrovaného územného manažmentu (integrujúceho sektorové politiky a investičné intervencie verejného sektora), efektívnych štruktúr verejnej správy a služieb

verejnosti čo najbližšie k občanovi v polycentrickej sústave obcí a miest,

- byť postavený na vecnom prístupe k riešeniu výziev a problémov rozvoja obcí a regiónov založenom na ich poznaní, objektívnom zhodnotení a hľadaní najefektívnejších a najúčinnejších riešení s využitím najnovších poznatkov, techník a technológií,
- byť užitočným, efektívnym a vecným nástrojom pre potreby orgánov samosprávy.

Vypracovanie PHRSR UMR Prešov vyplýva zo Zákona NR SR č. 539/2008 Z. z. o podpore regionálneho rozvoja v znení neskorších predpisov. PHRSR UMR Prešov je vypracovaný podľa odporúčaní dokumentu „Metodika tvorby a implementácie programov hospodárskeho rozvoja a sociálneho rozvoja regiónov, programov rozvoja obcí a skupín obcí s uplatnením princípov udržateľného smart (inteligentného, rozumného) rozvoja“ verzia 1.0.4 (ďalej „Metodika PHRSR“), dostupná na nasledovnom linku:
https://mirri.gov.sk/sekcie/regionalny-rozvoj-2/metodika-tvorby-implementacie-phrs/
Metodika PHRSR obsahuje odporúčaný postup a obsah programov hospodárskeho rozvoja a sociálneho rozvoja samosprávnych krajov, obcí a skupín obcí. Rešpektovanie tejto metodiky zabezpečuje súlad procesu tvorby a obsahu PHRSR so Zákonom NR SR č. 539/2008 Z. z o podpore regionálneho rozvoja v znení neskorších predpisov, dokumentom „Metodika a inštitucionálny rámec tvorby verejných stratégií“, a nadradenými programovými dokumentmi.

Na popis územia UMR Prešov boli použité dátové podklady PSK „Socio-ekonomický profil okresu Prešov.“ Spoločné údaje za mesto a obce v území UMR Prešov neboli pre väčšinu ukazovateľov dostupné. Údaje za celý okres boli doplnené o relevantné údaje z PHRSR jednotlivých obcí územia UMR Prešov. Dokument PHRSR UMR Prešov sa tvoril súčasne s tvorbou strategických dokumentov na národnej (Partnerská dohoda SR, Program Slovensko, Plán obnovy a odolnosti SR) a regionálnej úrovni (PHRSR a IÚS PSK) a v predkladanej verzii odráža súčasný stav prípravy dokumentov. PHRSR UMR Prešov tak je vypracovaný v súlade s cieľmi a prioritami ustanovenými v Národnej stratégii regionálneho rozvoja SR. PHRSR UMR Prešov zohľadňuje ciele a priority ustanovené v PHRSR PSK. PHRSR UMR Prešov je vypracovaný podľa záväznej časti územnoplánovacej dokumentácie regiónu a združených obcí. Medzi dôležité strategické dokumenty vo vzťahu k PHRSR UMR Prešov patria taktiež Agenda 2030, Vízia a stratégia Slovenska do roku 2030, Program Slovensko, Slovensko 2030, Partnerská dohoda SR, Plán obnovy a odolnosti SR a ďalšie. PHRSR UMR Prešov bol pripravovaný zároveň s novým Programom Slovensko a PHRSR a IÚS PSK. Jednotlivé mesto a obce na území UMR Prešov majú spracované svoje programy hospodárskeho

a sociálneho rozvoja, PHRSR UMR Prešov vychádza z PHSR mesta a obcí na území UMR Prešov, zohľadňuje výzvy, strategické ciele a rozvojové zámery jednotlivých obcí. Platnosť týchto strategických dokumentov skončí v najbližších rokoch. Nahradí ich navrhovaný PHRSR skupiny obcí (PHRSR UMR Prešov). Mesto Prešov má spracované aj viaceré sektorové stratégie.

PHRSR UMR Prešov bol vypracovaný v zabezpečení odborom projektového riadenia a útvarom analýz a stratégií Mestského úradu Prešov v spolupráci so samosprávami, sociálno-ekonomickými partnermi a s externými konzultantmi. Pre participatívnu tvorbu a implementáciu PHRSR UMR Prešov bola vytvorená kooperačná štruktúra. Na tvorbe dokumentu PHRSR UMR Prešov sa podieľali: Prípravný tím pre spracovanie Vstupnej správy dokumentu, Riadiaci výbor pre spracovanie dokumentu (primátorka mesta/primátor mesta a starostovia obcí, vedúci tematických pracovných skupín), Pracovné skupiny (interné tematické pracovné skupiny a ich koordinátori; tematické pracovné skupiny a ich koordinátori), Tím pre koordináciu spracovania dokumentu (gestorka a koordinátorka).

Za prípravu, spracovanie, aktualizáciu, implementáciu, monitorovanie a hodnotenie dokumentu PHRSR UMR Prešov je zodpovedná Kooperačná rada UMR Prešov. Postavenie, pôsobnosť, zloženie a úlohy Kooperačnej rady upravuje Štatút a rokovací poriadok Kooperačnej rady UMR Prešov.

Podľa zákona NR SR č. 539/2008 Z. z. o podpore regionálneho rozvoja v znení neskorších predpisov PHRSR resp. Spoločný PHRSR skupiny obcí, sa vypracúva pri uplatnení partnerstva. Partnerstvo je forma spolupráce medzi sociálno-ekonomickými partnermi, ktorí zabezpečujú hospodársky rozvoj, sociálny rozvoj alebo územný rozvoj dotknutého regiónu s ohľadom na udržateľný rozvoj.

Partnermi pri vypracovaní PHRSR UMR Prešov boli:

- aktéri rozvoja skupiny obcí/VÚC, SPR,
- verejnosť a dotknutá verejnosť,
- sociálno-ekonomickí partneri.

Medzi hlavných aktérov rozvoja UMR Prešov patria subjekty (fyzické a právnické osoby), ktoré zohrávajú akúkoľvek úlohu v rozvoji obcí, VÚC alebo v nich existujúcich strategicko-plánovacích regiónov (skupín obcí) bez ohľadu na ich dotknutosť a záujem o účasť na procese rozhodovania, tvorby a implementácie PHRSR UMR Prešov.

Za dotknutú verejnosť sa považujú subjekty (fyzické a právnické osoby) dotknuté procesom tvorby a implementácie PHRSR UMR Prešov. V zmysle Aarhuského dohovoru a podľa Zákona NR SR č. 24/2006 Z. z. o posudzovaní vplyvov na životné prostredie vstupuje do procesu tvorby a schvaľovania PHRSR UMR

Prešov aj verejnosť, ktorá má záujem alebo môže mať záujem o prípravu PHRSR UMR Prešov pred jej schválením. Sociálno-ekonomickí partneri sú subjekty (fyzické a právnické osoby), ktoré sú aktívne pri cieľavedomom rozvoji obce, VÚC alebo v nich existujúcich strategicko-plánovacích regiónov (skupín obcí) a majú záujem o účasť na procese rozhodovania, tvorby PHRSR a jeho implementácii, teda sú pri nich partnermi verejného sektora. Metodika a inštitucionálny rámec tvorby strategických dokumentov používa pojem zainteresovaná strana tvorby stratégie (zúčastnené strany), čo je akákoľvek osoba, skupina osôb alebo inštitúcia, ktorá má záujem na tvorbe alebo implementácií vytváranej stratégie, ktorá by mohla byť tvorbou alebo implementáciou stratégie potenciálne ovplyvnená (dotknutá, zasiahnutá) alebo môže tvorbu, schválenie alebo implementáciu stratégie ovplyvniť. Je zrejmé, že sociálno-ekonomickí partneri sú aj zainteresované či zúčastnené strany. Pre účely PHRSR sa používa pojem „partneri“.

V procese prípravy, spracovania a implementácie PHRSR UMR Prešov boli identifikované nasledovné kľúčové skupiny partnerov:

- verejný sektor - orgány miestnej a regionálnej samosprávy, orgány štátnej správy,
- súkromný sektor - aktéri miestnej a regionálnej ekonomiky,
- neziskový sektor - mimovládne organizácie, nadácie, iniciatívy,
- ďalší aktéri pôsobiaci v oblasti služieb (vzdelávanie, sociálne služby a zdravotníctvo, kultúra a šport, cestovný ruch, bývanie a pod.), odborné inštitúcie, experti.

Proces prípravy PHRSR UMR Prešov

Iniciátorom a zadávateľom spracovania PHRSR UMR Prešov bola Ing. Andrea Turčanová, primátorka Mesta Prešov, ktorá oslovila starostov obcí Haniska, Ľubotice a Záborské s návrhom vytvoriť územie UMR Prešov a spracovať spoločnú integrovanú územnú stratégiu/ program rozvoja. Na prípravnom stretnutí sa predstavitelia oslovených samospráv dohodli na spoločnom postupe a spoločne uzatvorili memorandum o spolupráci na príprave a vypracovaní Integrovanej územnej stratégie ako Spoločného programu hospodárskeho rozvoja a sociálneho rozvoja obcí na území udržateľného mestského rozvoja Prešov, ktorý nahrádza samostatné PHRSR obcí.

V nasledujúcej tabuľke je uvedený vecný a časový harmonogram prípravy a schvaľovania Spoločného programu hospodárskeho rozvoja a sociálneho rozvoja na území udržateľného mestského rozvoja Prešov na obdobie 2023 – 2030 s výhľadom do roku 2035, vrátane definovania zodpovednosti za jednotlivé fázy/kroky .

Tabuľka 1 *Časový harmonogram prípravy a schvaľovania PHRSR Prešov*

Fáza/ Krok	Obsah	Začiatok fázy	Koniec fázy	Zodpovedná osoba/partner
Fáza 1	Identifikácia potreby a impulzov vypracovania PHRSR a rozhodnutie o začatí prípravných prác	09/2020	10/2020	Riadiaci výbor PHRSR
Fáza 2	Prípravné práce, spracovanie a schválenie Vstupnej správy, vrátane predbežnej vízie	11/2020	04/2021	Prípravný tím/spracovatelia Vstupnej správy, Riadiaci výbor PHRSR
Fáza 3	Inventarizačná, analytická a prognostická fáza spracovania PHRSR	05/2021	11/2021	Riadiaci výbor PHRSR, experti
Fáza 4	Stanovenie vízie, strategického smerovania, priorít a strategických cieľov PHRSR	10/2021	01/2023	Riadiaci výbor PHRSR, tím pre koordináciu tvorby a implementácie PHRSR, experti
Fáza 5	Návrh vlastnej stratégie – strategického prístupu, postupu a nástrojov na dosiahnutie vízie a cieľov	01/2023	07/2023	Riadiaci výbor PHRSR, tím pre koordináciu tvorby a implementácie PHRSR, experti
Fáza 6	Nastavenie implementácie, financovania, monitorovania a vyhodnocovania PHRSR	08/2023	09/2023	Riadiaci výbor PHRSR, tím pre koordináciu tvorby a implementácie PHRSR
Fáza 7	Spracovanie návrhu Akčného plánu – zásobník strategických investícií	09/2023	09/2023	Riadiaci výbor PHRSR, tím pre koordináciu tvorby a implementácie PHRSR, experti
Fáza 8	Prerokovanie a schvaľovanie návrhu PHRSR	10/2023	12/2023	Riadiaci výbor PHRSR, tím pre koordináciu tvorby a implementácie PHRSR, experti

/zdroj: PHRSR UMR Prešov, 2021/

Vzťah k iným strategickým dokumentom

Strategické dokumenty a politiky EÚ

- Agenda 2030 pre udržateľný rozvoj
- Ciele politiky EÚ v programovacom období 2021-2027
- Európska zelená dohoda (European Green Deal) publikovaná v decembri 2019, ktorá stanovuje plán opatrení s cieľom prechodu na plne klimaticky neutrálne hospodárstvo
- Stratégia EÚ v oblasti biodiverzity do roku 2030
- Stratégia Rady Európy pre mládež do roku 2030
- EÚ Európa 2020 Stratégia pre inteligentný a udržateľný rast podporujúci začlenenie, COM(2010) 2020 v konečnom znení
- Európska stratégia pre nízkoemisnú mobilitu (COM(2016) 501 z 20. 7. 2016)
- Plán prechodu na konkurencieschopné nízkouhlíkové hospodárstvo do roku 2050, COM(2011) 112 v konečnom znení
- Energetický plán do roku 2050 COM(2011) 885 v konečnom znení
- Nástroj na prepájanie Európy v oblasti dekarbonizácie hospodárstva a podpory využívania čistej energie
- Program pre sociálnu zmenu a inovácie v oblasti zamestnanosti a sociálneho začleňovania

Strategické dokumenty a politiky SR

- Národné priority implementácie Agendy 2030, ÚPVII SR
- Národný investičný plán Slovenskej republiky na roky 2018 – 2030, UPVII
- Koncepcia územného rozvoja Slovenska (KURS), MDV SR, rok spracovania 2001, aktualizované 2011
- Východiskový návrh priorít SR pre politiku súdržnosti na programové obdobie 2021-2027, MIRRI SR
- Stratégia hospodárskej politiky SR do roku 2030, MH SR
- Strategický plán rozvoja dopravy SR do roku 2030, MDV SR, v platnosti
- Nízkouhlíková stratégia rozvoja SR do roku 2030 s výhľadom do roku 2050, MŽP SR
- Zelenšie Slovensko - Stratégia environmentálnej politiky Slovenskej republiky do roku 2030, MŽP SR
- Koncepcia mestského rozvoja Slovenskej republiky do roku 2030, MDV SR
- Vízia a stratégia rozvoja Slovenska do roku 2030, MIRRI
- Integrovaný národný energetický a klimatický plán do roku 2030, MH SR
- Stratégia adaptácie SR na nepriaznivé dôsledky zmeny klímy, MŽP SR, rok aktualizácie 2018
- Partnerská dohoda Slovenskej republiky na roky 2021 – 2027, MIRRI
- Program Slovensko 2021 – 2027, MIRRI, schválený EK 23. 11. 2022
- Implementačná stratégia - systém integrovaného poskytovania zdravotnej starostlivosti: Modernizácia zdravotníckej infraštruktúry a zlepšenie dostupnosti kvalitných služieb v primárnej a akútnej lôžkovej zdravotnej starostlivosti, Ministerstvo zdravotníctva SR, rok aktualizácie 2018

- Strategický rámec starostlivosti o zdravie pre roky 2014 - 2030, Ministerstvo zdravotníctva SR, obdobie 2014 – 2030
- Ďalšie sektorové koncepčné dokumenty SR

Strategické dokumenty územia UMR Prešov a VÚC

- Územné plány samospráv v rámci UMR Prešov (mesto Prešov, obec Ľubotice, obec Haniska, obec Záborské)
- Program rozvoja mesta Prešov na roky 2015 – 2020 s výhľadom do roku 2025
- Stratégia udržateľného rozvoja dopravy mesta Prešov, mesto Prešov, 2015 - 2022,
- Akčný plán udržateľného energetického rozvoja mesta Prešov
- Základná stratégia adaptácie na nepriaznivé zmeny klímy na území mesta Prešov
- Program odpadového hospodárstva mesta Prešov, mesto Prešov, 2015 - 2020
- Komunitný plán rozvoja sociálnych služieb, mesto Prešov, 2018 - 2025
- Potenciál mesta Prešov v oblasti Smart City, mesto Prešov, rok spracovania 2018
- Stratégia rozvoja kultúry mesta Prešov, mesto Prešov, 2021 - 2026 (2031)
- Systém energetického manažérstva mesta Prešov, mesto Prešov, rok spracovania 2020
- Program rozvoja bývania mesta Prešov do roku 2030, mesto Prešov, 2023 - 2030
- PHSR obce Haniska na roky 2015 - 2020, obec Haniska
- Komunitný plán sociálnych služieb 2018 – 2023, obec Haniska
- Nízkouhlíková stratégia obce Haniska na roky 2021 – 2031, obec Haniska
- PHSR obce Ľubotice na roky 2015 - 2023, obec Ľubotice
- Komunitný plán sociálnych služieb obce Ľubotice na roky 2018 – 2027, obec Ľubotice
- Program hospodárskeho a sociálneho rozvoja obce Záborské na roky 2015-2025, obec Záborské
- Komunitný plán Záborské (2016 – 2025), obec Záborské
- Program ochrany obce Záborské pred lokálnymi záplavami, zosuvmi, suchom a na ozdravovanie klímy katastra obce, obec Záborské, obec Záborské, rok spracovania 2021
- Naše Tri prúty, MAS Tri prúty, rok spracovania 2018
- Koncepcia rozvoja cestovného ruchu v regióne Dolný Šariš v kontexte širších
- Program hospodárskeho rozvoja a sociálneho rozvoja Prešovského samosprávneho kraja na roky 2021 - 2030
- Plán udržateľnej mobility Prešovského samosprávneho kraja (PUM)
- Územný plán Prešovského samosprávneho kraja
- Koncepcia rozvoja sociálnych služieb v Prešovskom samosprávnom kraji na roky 2020 – 2025, Prešovský samosprávny kraj
- Stratégia PSK pre mládež na roky 2015 - 2020 s výhľadom do roku 2025, Prešovský samosprávny kraj

- Kostrová sieť cyklistických trás v Prešovskom samosprávnom kraji, Prešovský samosprávny kraj, rok spracovania 2018
- Quo vadis, Romale? Rómske komunity na území Prešovského samosprávneho kraja
- Nízkouhlíková stratégia organizácií v zriaďovateľskej pôsobnosti PSK (v návrhu)
- Adaptačná stratégia na zmenu klímy PSK (v návrhu)
- Ďalšie sektorové koncepčné dokumenty VÚC Prešov a UMR Prešov

Počas prípravy a spracovania PHRSR UMR Prešov boli využívané podporné kapacity z viacerých úrovní: MIRRI (metodika), PSK (analytické dáta, konzultácie), Strategicko-plánovací región Šariš (vzájomná koordinácia), UMR Prešov (analytické dáta, tematické pracovné skupiny, projektové tímy) a služby externých expertov (konzultácie). Bol spracovaný návrh participatívnej tvorby PHRSR UMR Prešov, odhad potreby zdrojov (ľudských, finančných, dátových...) pre tvorbu PHRSR a identifikácia rizík tvorby stratégie. Súčasťou participatívnej tvorby PHRSR bol aj proces strategického environmentálneho posudzovania. Vstupná správa IÚS UMR Prešov bola spracovaná v štruktúre Oznámenia o strategickom dokumente podľa Zákona NR SR č. 24/2006 Z. z. o posudzovaní vplyvov na životné prostredie a o zmene a doplnení niektorých zákonov v znení neskorších predpisov. Mesto Prešov predložilo príslušnému okresnému úradu Oznámenie o strategickom dokumente, na základe ktorého príslušný orgán stanovil rozsah hodnotenia IÚS UMR Prešov (správa o hodnotení, bez časového harmonogramu) a stanovil tieto špecifické požiadavky:

- Navrhnúť všetky dopravné projekty v súlade s príslušnými normami STN a technickými predpismi.
- Pri podpore cyklistickej dopravy vytvárať vzájomne prepojenú sieť cyklotrás, ktorá zabezpečí možnosť plynulého a bezpečného pohybu cyklistov. Tiež pri tvorbe infraštruktúry pre cyklistickú dopravu odporúčame zohľadniť potreby všetkých účastníkov využívajúcich cyklotrasy, vrátane tých, ktorí využívajú čoraz populárnejšie prostriedky na elektrický pohon ako sú elektro bicykle či elektrické kolobežky.
- Bližšie konkretizovať navrhované projekty, ako aj ich územný priemet s ohľadom na mieru detailu jednotlivých projektov.
- Vyhodnotiť vplyvy na všetky druhy chránených území, prvky územného systému ekologickej stability, biotopy, resp. iné dotknuté záujmy ochrany prírody a krajiny v dotknutom území a navrhnúť adekvátne opatrenia na ich zmiernenie.
- Opraviť nepresné názvy strategických a koncepčných dokumentov PSK v kapitole 7. Vzťah k iným strategickým dokumentom ako napr.: Adaptačná stratégia PSK – správne „Adaptačná stratégia na zmenu klímy PSK“, Nízkouhlíková stratégia PSK – správne „Nízkouhlíková stratégia organizácií v zriaďovateľskej pôsobnosti PSK“, Program odpadového hospodárstva Prešovského kraja na roky 2021-2025 podľa dostupných informácií nie je vypracovaný a jeho vypracovanie nie je

v kompetencii PSK.

- Doplniť medzi východiskovými podkladmi oznámenia Program hospodárskeho rozvoja a sociálneho rozvoja PSK na roky 2021/2030, ktorý tam nie je uvedený a vo výstupnej správe strategického dokumentu je uvedený.
- Opraviť na strane 13 nesprávne uvedený názov platného Územného plánu Prešovského samosprávneho kraja.
- Rešpektovať pri návrhu a realizácií strategických cieľov plochu verejného záujmu pre vrtuľníky vrtuľníkovej záchrannej zdravotnej služby v areáli Fakultnej nemocnice s poliklinikou J. A. Reimana Prešov, prekážkové roviny a plochy Osobitného letiska Prešov a plánovaného heliportu v areáli Fakultnej nemocnice s poliklinikou J. A. Reimana Prešov.
- Rešpektovať pamiatkový fond v riešených územiach a postupovať v súlade s ustanoveniami pamiatkového zákona pri realizácií cieľov strategického dokumentu.

Strategické environmentálne posudzovanie PHRSR UMR Prešov

Súčasne so spracovaním dokumentu PHRSR UMR Prešov sa realizuje aj proces posudzovania vplyvov strategického dokumentu na životné prostredie (SEA). Proces SEA bol aj súčasťou spracovania IÚS, Vstupná správa IÚS UMR Prešov bola posúdená v štruktúre Oznámenia o strategickom dokumente podľa Zákona NR SR č. 24/2006 Z. z. o posudzovaní vplyvov na životné prostredie (zákon).

Oznámenie o strategickom dokumente Spoločný program hospodárskeho rozvoja a sociálneho rozvoja obcí na území udržateľného mestského rozvoja Prešov na roky 2023 – 2030 s výhľadom do roku 2035 bolo vypracované podľa §5 ods. 1 uvedeného zákona a následne bolo dňa predložené príslušnému orgánu, Okresnému úradu v Prešove, odboru starostlivosti o životné prostredie, obstarávateľom strategického dokumentu, Mestom Prešov, zastúpeným primátorom mesta Ing. Františkom Oľhom v zmysle §5 Zákona NR SR č. 24/2006 Z. z. o posudzovaní vplyvov na životné prostredie a o zmene a doplnení niektorých zákonov v znení neskorších predpisov. Príslušný orgán dňa 14. 11. 2023 rozposlal Oznámenie listom č. OU-PO-OSZP3-2023/049018-019 podľa §6 ods. 2 uvedeného zákona zainteresovaným subjektom - dotknutým orgánom a dotknutým obciam. Zároveň príslušný orgán oznámil, že konzultácie k predmetnému strategickému dokumentu podľa §63 uvedeného zákona je možné vykonať počas celého procesu posudzovania vplyvov strategického dokumentu na základe vopred dohodnutého termínu, na adrese príslušného orgánu a zároveň, že stanoviská verejnosti k oznámeniu o strategickom dokumente je možné predkladať do 15 dní odo dňa, kedy bolo oznámenie zverejnené dotknutou obcou podľa ust. §6 ods. 5 uvedeného zákona na adresu príslušného orgánu. Informácia o oznámení a samotné oznámenie bolo

zverejnené v zmysle zákona, na úradných tabuliach a na stránkach obcí UMR Prešov, k nahliadnutiu na mestskom a obecných úradoch dotknutých obcí a tiež prostredníctvom webového sídla Ministerstva ŽP SR (enviroportal). K Oznámeniu boli príslušnému orgánu doručené písomné stanoviská oslovených subjektov a verejnosti.

Stanoviská k Oznámeniu o strategickom dokumente PHRSR UMR Prešov

Pripomienky a požiadavky boli sformulované v stanoviskách nasledovných subjektov:

- Prešovský samosprávny kraj, Úrad Prešovského samosprávneho kraja, Námestie mieru 2, 080 01 Prešov
- Krajský pamiatkový úrad, Hlavná 115, 080 01 Prešov
- Ministerstvo životného prostredia SR, Odbor štátnej správy ochrany prírody a krajiny, Námestie Ľudovíta Štúra 35/1, 812 35 Bratislava
- Dopravný úrad, Letisko M.R. Štefánika, 823 05 Bratislava
- Ministerstvo dopravy SR, Námestie slobody 6, 810 05 Bratislava 15, P.O.BOX 100

Na základe predloženého Oznámenia o strategickom dokumente príslušný orgán stanovil rozsah hodnotenia strategického dokumentu UMR Prešov. V rozsahu hodnotenia bola sformulovaná požiadavka na vypracovanie Správy o hodnotení vplyvu strategického dokumentu na životné prostredie podľa Prílohy č. 4 Zákona NR SR č. 24/2006 Z. z. o posudzovaní vplyvov na životné prostredie a o zmene a doplnení niektorých zákonov v znení neskorších predpisov s osobitným prihliadnutím na body uvedené v časti špecifické požiadavky rozsahu hodnotenia. Informácie o PHRSR UMR Prešov sú dostupné na webovom sídle https://www.presov.sk/presov-2030.html.

2. Územie

Územie udržateľného mestského rozvoja Prešov (ďalej len „UMR Prešov“ alebo „rozvojové územie“) tvorí mesto Prešov (katastrálne územie Prešov, Solivar, Šalgovík a Nižná Šebastová) spoločne s obcami Ľubotice, Haniska a Záborské. Celkový počet obyvateľov UMR Prešov podľa Sčítania obyvateľov domov a bytov k 1.1.2021 je 90 281. Mesto Prešov s 84 824 obyvateľmi je tretím najväčším mestom Slovenska a spolu s Košicami tvorí na Slovensku druhú najvýznamnejšiu mestskú aglomeráciu s vysokou koncentráciou podnikateľských aktivít, priemyslu, školských a zdravotníckych zariadení aj kultúrnej infraštruktúry. Je administratívnym, kultúrnym a hospodárskym centrom najľudnatejšieho kraja v SR, sídlom Úradu Prešovského samosprávneho kraja a okresným mestom. Obec Ľubotice s počtom obyvateľov 3 638 je kompaktnou súčasťou UMR Prešov. Kataster obce zo severnej, západnej a južnej časti susedí s katastrálnymi územiami mesta Prešov (k. ú. Nižná Šebastová, k. ú. Prešov, k. ú. Šalgovík). Súčasťou obce

je taktiež časť Šarišské Lúky, ktorá sa nachádza v západnej časti katastra. Obec Ľubotice má rozsiahlu priemyselnú zónu, kde pôsobí viac než 100 podnikateľských subjektov. Južnú časť UMR Prešov dotvárajú obce Haniska so 739 obyvateľmi a Záborské s 1 080 obyvateľmi a predstavujú významné priemyselné zóny. Obec Záborské leží v Košickej kotline, v údolí východného prítoku Torysy, v nadmorskej výške okolo 320 m n. m.

Obrázok 1 *Územie udržateľného mestského rozvoja Prešov s vyznačením jadrového územia mesta Prešov*

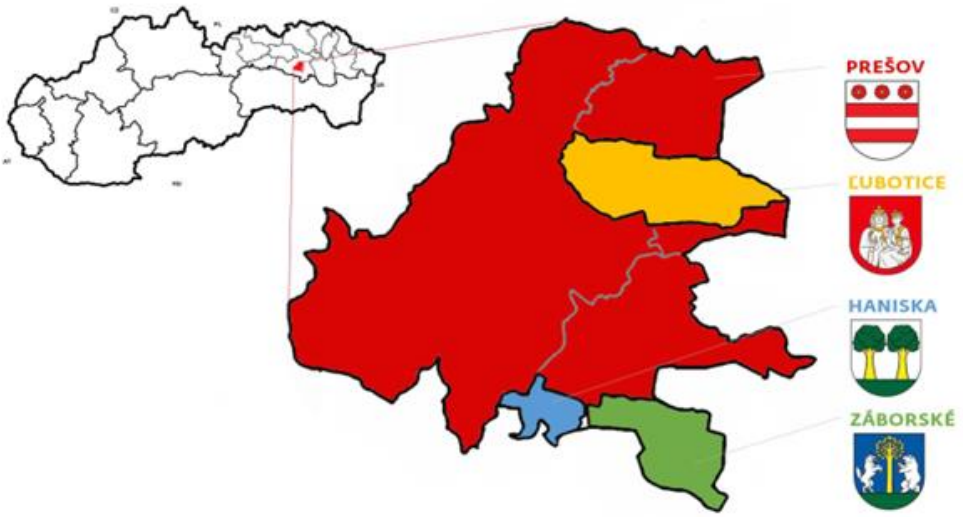

/zdroj: PHRSR UMR Prešov 2030 /

Obce Ľubotice, Záborské a Haniska boli integrované do spoločného rozvojového územia z viacerých dôvodov. Obec Ľubotice (4 % obyvateľov UMR Prešov) bola začlenená do UMR prešov nielen vzhľadom na jej geografickú polohu (bezprostredne susedí s uvedenými katastrálnymi oblasťami mesta Prešov zo severu, juhu aj zo západu), ale aj vzhľadom na významné ekonomické, kultúrne a sociálne prepojenia. Ľubotice sú obcou s relatívne vysokým nárastom počtu obyvateľstva v rámci UMR Prešov za uplynulých 10 rokov, z čoho vyplýva potreba strategických riešení v oblasti nízkouhlíkovej mobility. Spoločným záujmom v rámci UMR Prešov je napríklad aj sanácia aktívnych zosuvných území, ktoré sú lokalizované v relatívne husto osídlenej časti územia tvoriacej hranicu mesta Prešov a obce Ľubotice.

Na území obcí Záborské a Haniska (ktoré tvoria spolu 2 % obyvateľov UMR Prešov) sa nachádza významná ekonomická báza v podobe dvoch priemyselných parkov. V katastri obce Záborské je situovaný Priemyselný park Záborské, kde v súčasnosti dochádza za prácou viac ako 1300 pracovníkov, prevažne z Prešova alebo z blízkeho okolia. Taktiež v obci Haniska sa nachádza Priemyselný Park Haniska – Prešov.

Obrázok 2 *Sídelná štruktúra a poloha územia UMR Prešov v širších vzťahoch územia okresu Prešov*

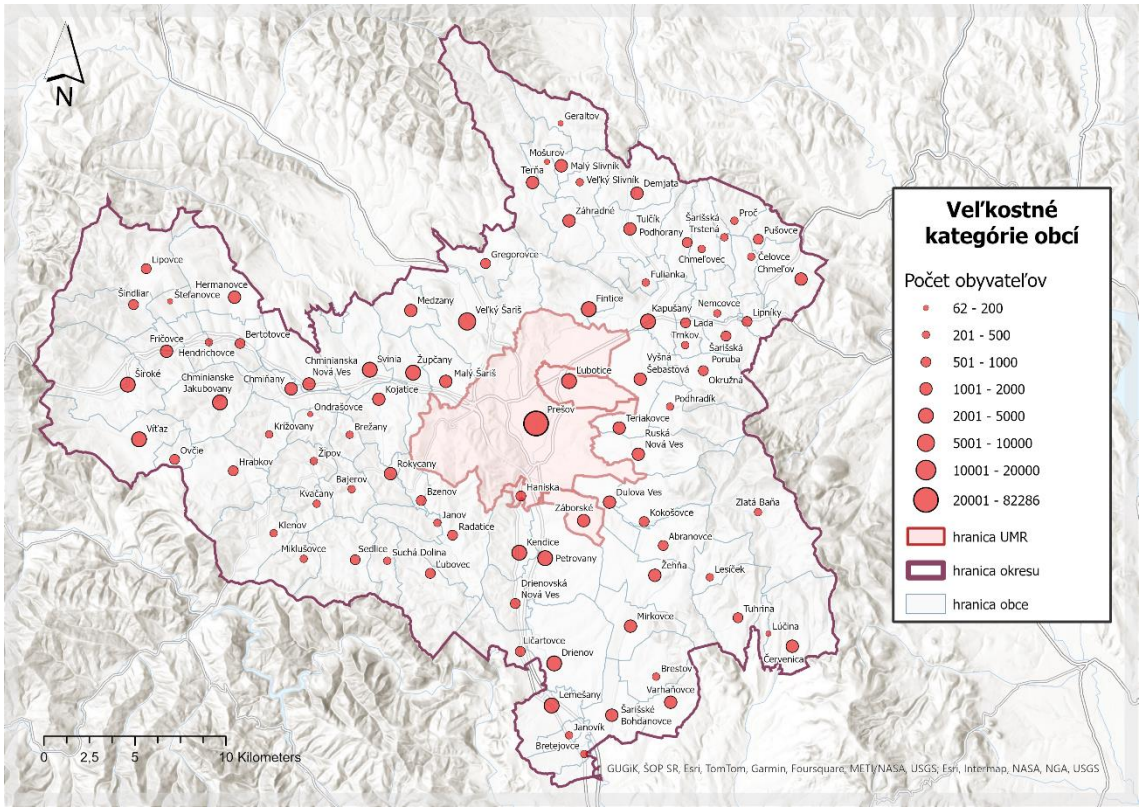

/zdroj: vlastné spracovanie, 2024/

3. Dotknuté obce

Dotknuté obce

- Územná samospráva - obce tvoriace územie UMR Prešov a obce s hranicou katastra územia UMR Prešov
- Regionálna samospráva - Prešovský samosprávy kraj

4. Dotknuté orgány

Regionálne orgány štátnej správy

- Okresný úrad Prešov,
- Regionálny úrad verejného zdravotníctva

Orgány špecializovanej štátnej správy

- Ministerstvo investícií, regionálneho rozvoja a informatizácie SR, Pribinova 25, 811 09 Bratislava
- Ministerstvo dopravy SR, Námestie slobody č. 6, P.O.BOX 100, 810 05 Bratislava
- Ministerstvo životného prostredia SR, Námestie Ľudovíta Štúra 1, 812 35 Bratislava
- Ministerstvo hospodárstva SR, Mlynské nivy 44/a, 827 15 Bratislava 212

- Ministerstvo zdravotníctva SR, Limbová 2, P.O. BOX 52, 837 52 Bratislava 37
- Ministerstvo školstva, vedy, výskumu a športu SR, Stromová 1, 813 30 Bratislava
- Ministerstvo financií SR, Štefanovičova 5, P. O. BOX 82, 817 82 Bratislava
- Ministerstvo práce, sociálnych vecí a rodiny SR, Špitálska 4,6,8, 816 43 Bratislava
- Ministerstvo pôdohospodárstva a rozvoja vidieka SR, Dobrovičova 12, 812 66 Bratislava
- Ministerstvo obrany SR, Kutuzovova 8, 832 47 Bratislava
- Ministerstvo vnútra SR, Pribinova 2, 812 72 Bratislava
- Ministerstvo kultúry SR, Nám. SNP č. 33, 813 31 Bratislava – Staré Mesto

Ďalšie dotknuté subjekty

- Štátna ochrana prírody, Tajovského 28B, 974 01 Banská Bystrica
- LESY SR, Nám. SNP 8, 975 66 Banská Bystrica
- Východoslovenská vodárenská spoločnosť, a.s., Komenského 50, 042 48 Košice
- Slovenská správa ciest, Miletičova 19, P.O.BOX 19, 826 19 Bratislava
- Železnice SR, Bajkalská 720/41, 821 05 Ružinov
- Krajský pamiatkový úrad, Hlavná 2928/115, 080 01 Prešov
- Železnice SR, Bajkalská 720/41, 821 05 Ružinov

Vymedzenie zainteresovanej verejnosti vrátane jej združení:

Zainteresovanou verejnosťou sú predovšetkým obyvatelia územia UMR Prešov a každý kto prejaví záujem o strategický dokument. Ďalej občianske iniciatívy, občianske združenia a mimovládne organizácie, podporujúce ochranu životného prostredia, ktoré prejavia záujem na postupoch environmentálneho rozhodovania v zmysle ustanovení §24 až §28 zákona č. 24/2006 Z. z.

5. Schvaľujúci orgán

V zmysle Zákona č. 539/2008 Z. z. o podpore regionálneho rozvoja v znení neskorších predpisov, § 8a Spoločný program rozvoja obcí a jeho aktualizáciu schvaľujú obecné zastupiteľstvá obcí, ktoré vypracovali spoločný program rozvoja obcí.

6. Obsah a hlavné ciele strategického dokumentu a jeho vzťah k iným strategickým dokumentom

Obsah a štruktúra strategického dokumentu je v súlade s § 8 zákona č. 539/2008 Z. z. o podpore regionálneho rozvoja v znení neskorších predpisov, čl. 29 Nariadenia Európskeho parlamentu a Rady Európskej Únie 2021/1060 a Metodikou tvorby a implementácie PHRSR regiónov, programov rozvoja obcí

a skupín obcí s uplatnením princípov udržateľného smart (inteligentného, rozumného) rozvoja. Rámcové členenie dokumentu:

- *Analytická časť* obsahuje zhrnutie najvýznamnejších faktov o území UMR Prešov relevantných pre tvorbu stratégie rozvoja.
- *Strategická časť* obsahuje stratégiu rozvoja územia pri zohľadnení jeho vnútorných špecifík a určí hlavné smery, priority a ciele rozvoja územia rešpektovaním princípov regionálnej politiky s cieľom dosiahnutia vyváženého udržateľného rozvoja územia.
- *Programová časť* obsahuje najmä zoznam opatrení a aktivít na zabezpečenie realizácie programu rozvoja územia.
- *Realizačná časť* je zameraná na popis postupov inštitucionálneho zabezpečenia formou partnerstva a organizačné zabezpečenie realizácie programu rozvoja územia, systém monitorovania a hodnotenia plnenia programu rozvoja územia s ustanovením merateľných ukazovateľov, vecný a časový harmonogram realizácie programu rozvoja územia formou akčných plánov.
- *Finančná časť* obsahuje finančné zabezpečenie jednotlivých opatrení a aktivít, inštitucionálnej a organizačnej stránky realizácie programu rozvoja územia.

6.1 Analytická časť

Analýza vnútorného prostredia

- Charakteristika sociálno-ekonomickej, územno-technickej, prírodno - environmentálnej a inštitucionálno-organizačnej oblasti relevantnej k územiu UMR Prešov,
- popis mesta a jednotlivých a obcí, ktoré sa nachádzajú na území UMR Prešov,
- opatrenia realizované na území v období 2014 – 2020 (zhodnotenie realizovaných stratégií),
- prieskumy realizované na území.

Analýza vonkajšieho prostredia

- analýza politických, ekonomických, sociálnych, technologických, legislatívnych a ekologických faktorov (PESTLE).

Zhrnutie analýz

- analýza vonkajšieho prostredia, analýza silných a slabých stránok, príležitostí a rizík (SWOT),
- kľúčové výzvy a problémy (strom problémov vrátane príčin problémov a možných následkov neriešenia problémov, t. j. nulový variant, ak by sa stratégia nerealizovala),
- vnútorný rozvojový potenciál a limity,
- hlavné faktory rozvoja a disparity.

Vstupnými podkladmi pre analytickú časť boli:

- Vstupná správa pre spracovanie strategického dokumentu UMR Prešov vrátane príloh,
- výstupy tematických pracovných skupín UMR Prešov,
- strategické a koncepčné dokumenty PSK, mesta Prešov a obcí tvoriacich územie UMR Prešov (územné plány a programy rozvoja),
- iné relevantné strategické a analytické dokumenty na národnej, regionálnej a miestnej úrovni,
- dátové podklady PSK, mesta Prešov a obcí tvoriacich územie UMR Prešov,
- verejne dostupné štatistické dáta,
- výstupy špecializovaných štúdií a projektov,
- kvalitatívne dáta (výstupy z prieskumov, záznamy z rozhovorov s aktérmi na území a pod.).

6.2 Strategická časť

Strategická časť nadväzuje na zistenia analytickej časti a nadradené strategické dokumenty. Obsahuje stratégiu rozvoja územia UMR Prešov pri zohľadnení jeho vnútorných špecifík a vonkajších výziev. Určuje ciele a priority rozvoja územia pri rešpektovaní princípov regionálnej politiky v záujme dosiahnutia vyváženého udržateľného rozvoja územia. Celkovú predstavu o budúcnosti vyjadruje vízia rozvoja územia UMR Prešov. Témy stratégie sú usporiadané do 3 priorít rozvoja UMR Prešov, ktoré sú rozpracované do 6 strategických a 15 špecifických cieľov. Hlavnými princípmi rozvoja územia je udržateľný územný rozvoj založený na ochrane, efektívnom a ekologickom využívaní zdrojov územia, uplatňovanie smart konceptu, participácia a súdržnosť. Stratégia smart rozvoja UMR Prešov je zameraná na dosiahnutie vysokej kvality života prostredníctvom realizácie inovácií a zmien. Smart rozvoj je založený na troch pilieroch – smart prostredí (využívanie zdrojov), smart ekonomike a smart spoločnosti (komunity).

Vízia a hlavný cieľ, spoločne s prioritami a strategickými cieľmi, predstavujú strategickú časť PHRSR UMR Prešov. Vízia a hlavný cieľ načrtávajú predstavu o budúcom smerovaní územia. Reprezentujú pohľad na očakávaný stav v strednodobom až dlhodobom časovom horizonte.
Priority definujú kľúčové želané zmeny v kvalite života obyvateľov, ktoré sa realizáciou stratégie PHRSR UMR Prešov sledujú, resp. majú byť dosiahnuté.

Strategické ciele predstavujú kľúčové výsledky a výstupy nasmerované na dosiahnutie vízie a definovaných priorít. Sú orientované na strednodobý časový horizont.
Na priority a strategické ciele nadväzujú špecifické ciele, ktoré sú zamerané na krátkodobý časový horizont.

Vízia, priority a ciele, ktoré boli definované vo Vstupnej správe, boli prerokované so zástupcami mesta Prešov a obcí tvoriacich UMR Prešov, s členmi Kooperačnej rady UMR Prešov a členmi tematických pracovných skupín. Vízia, priority a ciele boli spresnené a posúdené z hľadiska ich súladu a doplnkovosti s cieľmi nadradených strategických dokumentov a usporiadané do hierarchickej štruktúry.

Vízia

PREŠOV 2030 - SPRÁVNA VOĽBA PRE DÔSTOJNÝ ŽIVOT, SPOLUPRÁCU, PODNIKANIE A POZNÁVANIE.

PHRSR UMR Prešov je spracovaný na obdobie rokov 2023 - 2030, vízia želaného stavu je koncipovaná do roku 2035 a vychádza z predpokladu, že budú využité príležitosti a potenciál rozvoja územia. Definovaná je ako očakávaný stav a vychádza z vízie mesta Prešov a obcí tvoriacich UMR Prešov. Vízia 2030 predstavuje obraz premeny rozvojového územia v najbližšom desaťročí na ideálne miesto pre život miestnych obyvateľov, kde dochádza k eliminácii odlivu mozgov s opätovnému priťahovaniu nadaných ľudí a súčasne s nimi aj nových nápadov pre rozvoj.

Priority

Pre dosiahnutie vízie UMR Prešov boli stanovené 3 priority, ktoré korešpondujú s cieľmi politiky Európskej únie v programovom období 2021 – 2027 a reprezentujú želané zmeny v kvalite života na území UMR Prešov. Vzhľadom na predpoklad širokého využitia zdrojov zo štátneho rozpočtu a štrukturálnych fondov EÚ boli priority a strategické ciele PHRSR naviazané na priority a ciele strategických a programových dokumentov Slovenskej republiky pre čerpanie EŠIF na obdobie 2021 – 2027 (Partnerská dohoda medzi EÚ a SR, Program Slovensko). Za účelom dosiahnutia vízie a hlavného cieľa boli definované 3 prioritné oblasti rozvoja, konkrétne:

PRIORITA 1 - UDRŽATEĽNÉ A ODOLNÉ PROSTREDIE
PRIORITA 2 - SLUŽBY PRE DÔSTOJNÝ ŽIVOT
PRIORITA 3 - STRATEGICKÝ ROZVOJ A DOBRÉ SPRAVOVANIE

Ciele

Dokument má hlavný cieľ rozvoja územia a 6 strategických cieľov, ktoré sú detailnejšie rozpracované prostredníctvom 15 špecifických cieľov. Súbor cieľov vytvára rámec pre rozvoj územia, pre vytváranie funkčných väzieb medzi jadrovým sídlom – mestom Prešov a jeho okolím, pre posilnenie jednotlivých funkcií a vzťahov s okolitými mestskými oblasťami a susediacimi územiami (strategicko - plánovací región Šariš).

Hlavný cieľ:

Vytvoriť podmienky pre všestranný rozvoj územia, využitie dostupných vnútorných a vonkajších potenciálov a zdrojov na zlepšenie kvality života v území a napĺňanie potrieb jeho obyvateľov a návštevníkov.

Strategický cieľ 1.1: Podporiť dekarbonizáciu, udržateľnosť dopravnej infraštruktúry a energetiky

Špecifický cieľ 1.1.1: Vybudovať udržateľný model multimodálnej a ekologickej mobility

Špecifický cieľ 1.1.2: Nastaviť systém energeticky efektívneho rozvoja

Strategický cieľ 1.2: Zlepšiť stav životného prostredia

Špecifický cieľ 1.2.1: Nastaviť koncepčný prístup k ochrane prírody a krajiny, prevencii rizík a adaptácii na nepriaznivé zmeny klímy

Špecifický cieľ 1.2.2: Skvalitniť a zefektívniť systém nakladania s odpadom

Strategický cieľ 2.1: Zabezpečiť kvalitné vzdelávanie pre potreby trhu práce

Špecifický cieľ 2.1.1: Zlepšiť kvalitu a podmienky pre predprimárne a primárne vzdelávanie

Špecifický cieľ 2.1.2: Uľahčiť prístup na trh práce všetkým skupinám obyvateľov

Strategický cieľ 2.2: Zabezpečiť dostupnú infraštruktúru, kvalitu služieb a podmienky pre vyššiu kvalitu života

Špecifický cieľ 2.2.1: Zabezpečiťdostupnosť kvalitných a integrovaných sociálnych a zdravotných služieb pre všetkých

Špecifický cieľ 2.2.2: Vytvoriť podmienky pre zdravý životný štýl

Špecifický cieľ 2.2.3: Zvýšiť bezpečnosť obyvateľov

Strategický cieľ 3.1: Zlepšiť systém strategického plánovania, riadenia a spolupráce

Špecifický cieľ 3.1.1: Vybudovať analytické, strategické, projektové a administratívne kapacity

Špecifický cieľ 3.1.2: Podporovať digitálnu transformáciu vo všetkých oblastiach

Špecifický cieľ 3.1.3: Podporovať medzisektorové partnerstvá

Strategický cieľ 3.2: Využiť potenciál územia pre ekonomický rozvoj

Špecifický cieľ 3.2.1: Rozvíjať inovačný potenciál územia, podporovať vedu, výskum a všetky typy inovácií

Špecifický cieľ 3.2.2: Rozvíjať potenciál pre kultúrny a kreatívny priemysel

Špecifický cieľ 3.2.3: Rozvíjať potenciál územia vďaka komplexnej podpore podnikania

Priority a ciele definované v strategickom dokumente sú v súlade s existujúcou územnoplánovacou dokumentáciou mesta Prešov a obcí tvoriacich UMR Prešov, ako aj v súlade s cieľmi nadradených dokumentov.

6.3 Programová časť

Programová časť strategického dokumentu PREŠOV 2030 nadväzuje na strategickú časť. V programovej časti sú popísané prioritné oblasti rozvoja územia UMR Prešov z hľadiska výziev a problémov, na ktoré reagujú, prehľad a zameranie konkrétnych cieľov, vrátane navrhovaných intervencií na dosiahnutie kľúčových ukazovateľov výstupov a udržateľných zmien. Pri návrhu ukazovateľov boli zohľadnené aj ukazovatele definované v nadradených strategických dokumentoch na národnej a regionálnej úrovni (Agenda 2030, Vízia a stratégie SR, PHRSR PSK) a ukazovatele odporúčané v metodike PHRSR. Kvantitatívne ukazovatele tvoria navzájom prepojenú sústavu a v procese monitorovania a hodnotenia môžu byť doplnené o kvalitatívne ukazovatele. V prípade hlavného cieľa ide o ukazovatele dopadu, v prípade strategických a špecifických cieľov ide o ukazovatele dopadu a výsledku.

6.4 Realizačná časť

Realizačná časť nadväzuje na strategickú a programovú časť PHRSR UMR Prešov, popisuje implementačný mechanizmus a vytvára rámec pre postupné napĺňanie všetkých strategických cieľov, vedúcich k trvalo udržateľnému rozvoju územia. Pri napĺňaní vízie a cieľov PHRSR UMR Prešov bude potrebné uplatňovať kombináciu viacerých nástrojov - finančných aj nefinančných, vrátane aplikácie integrovaného prístupu. Bude nevyhnutné, aby samosprávy územia UMR Prešov vyčlenili potrebné zdroje - ľudské zdroje, materiálne zdroje, finančné zdroje, informačné a komunikačné zdroje.

Implementácia - bude založená na realizácii navrhovaných intervencií (konkrétnych rozvojových aktivít a projektov), ktoré budú realizované na území UMR Prešov s cieľom naplnenia cieľov, vízie a dosiahnutia udržateľného rozvoja v zadefinovaných prioritných oblastiach. Počas prípravy strategického dokumentu bol zostavený zásobník rozvojových aktivít a projektov mesta Prešov a obcí na území UMR Prešov. Zo zásobníka boli identifikované prioritné strategické aktivity a projekty, ktoré tvoria Akčný plán PREŠOV 2030, ktorý tvorí samostatnú prílohu k strategickému dokumentu. Predstavuje vykonávaciu časť PHRSR

UMR Prešov, zostavený je na obdobie troch rokov (n+2) a zahŕňa návrh konkrétnych rozvojových aktivít a projektov na uvedené obdobie. Základnou myšlienkou je integrácia aktivít a projektov v rôznych oblastiach tak, aby sa vzájomne podporili v ich príspevku k naplneniu cieľov stratégie a samotného investovania. Implementácia stratégie bude zabezpečovaná jednotlivými samosprávami územia UMR Prešov v spolupráci so socio-ekonomickými partnermi. Kompetencie samosprávnych orgánov a iných stálych orgánov sú dané legislatívou, resp. štatútom Kooperačnej rady UMR Prešov. Hlavné úlohy samospráv vo vzťahu ku strategickému dokumentu:

- Mestské a obecné zastupiteľstvá
  - navrhujú spracovanie/aktualizáciu strategického dokumentu,
  - schvaľujú strategický dokument,
  - berú na vedomie správu o plnení strategického dokumentu,
  - schvaľujú finančné plány miest a obcí ako podklad pre spracovanie akčného a finančného plánu strategického dokumentu.
- Mestské a obecné úrady
  - zabezpečujú spracovanie/aktualizáciu strategického dokumentu,
  - vypracúvajú hodnotiacu správu o plnení strategického dokumentu,
  - vypracúvajú akčný a finančný plán k strategickému dokumentu,
  - aktualizujú akčný a finančný plán k strategickému dokumentu,
  - hľadajú finančné zdroje a zodpovedajú za prípravu a implementáciu projektov,
  - komunikujú s partnermi projektov, zástupcami Strategicko-plánovacieho regiónu (SPR) Šariš, Úradom Prešovského samosprávneho kraja, Ministerstva investícií, regionálneho rozvoja a informatizácie SR a ďalšími inštitúciami.

Monitorovanie a hodnotenie stratégie PREŠOV 2030 bude realizované podľa plánu monitorovania a hodnotenia, raz ročne. Mimoriadne hodnotenie bude možné realizovať na základe rozhodnutia Kooperačnej rady UMR Prešov, predovšetkým v prípade identifikovaného rizika alebo odklonu od stanovených cieľov. Monitorovanie a hodnotenie sa bude realizovať prostredníctvom súboru merateľných ukazovateľov. Nosnými zdrojmi údajov pre ukazovatele budú samosprávy územia UMR Prešov, Centrálny register zmlúv, monitorovací systém ITMS a Štatistický úrad SR. Väčšina ukazovateľov bude sledovaná na ročnej báze. Zodpovednosť za zber údajov a spracovanie hodnotiacej správy budú mať Administratívne kapacity UMR Prešov. Hodnotiaca správa bude mať písomnú formu, bude obsahovať

zoznam informovaných subjektov a môže navrhnúť prípadnú aktualizáciu alebo spracovanie nového strategického dokumentu. Funkciu monitorovacieho a hodnotiaceho výboru bude plniť Kooperačná rada UMR Prešov. Hodnotiaca správa bude predložená na prerokovanie Kooperačnej rade UMR Prešov, mestským a obecným zastupiteľstvám. Následne bude zverejnená.
Aktualizácia stratégie Prešov 2030 - zodpovednosť za proces aktualizácie nesie Útvar analýz a stratégií (ÚAaS) / Administratívne kapacity UMR Prešov. V súčinnosti s riadiacim tímom, tematickými pracovnými skupinami a inými relevantnými subjektmi pripraví odborné podklady pre aktualizáciu a zmenu rozvojového dokumentu.

Koordinačným, metodickým a kontrolným centrom pre realizáciu PHRSR UMR Prešov budú Administratívne kapacity UMR Prešov. Výkonnou zložkou pre napĺňanie PHRSR UMR Prešov bude Realizačný tím, ktorý bude zostavený z nasledovných členov:

- vedúci pracovník AK UMR,
- vedúci Odboru rozvojových aktivít,
- koordinátori jednotlivých rozvojových oblastí.

6.5 Finančná časť

Jedným z kľúčových faktorov pre naplnenie PHRSR UMR Prešov je zabezpečenie finančného krytia na realizáciu rozvojových aktivít a projektov. PHRSR UMR Prešov vychádza z predpokladu viaczdrojového financovania rozvojových aktivít a projektov, zameraných na plnenie cieľov stratégie. Okrem interných zdrojov - rozpočtov samospráv územia UMR Prešov, budú aktivity a projekty realizované aj z externých zdrojov (súkromných, verejných, návratných, nenávratných...) s možnosťou využitia rôznych finančných nástrojov. Stratégia PHRSR UMR Prešov sa špecificky orientuje na efektívne využitie možností financovania z prostriedkov EÚ v súlade s Partnerskou dohodou, Programom Slovensko a Plánom obnovy a odolnosti SR, no zahŕňa aj projekty financované z iných EÚ fondov (ESF+, ERASMUS+, PROGRAM INTERREG POĽSKO – SLOVENSKO, atď.) a finančných nástrojov EÚ.

Mesto Prešov a obce územia UMR Prešov budú zostavovať vlastný akčný aj finančný plán na daný rozpočtový rok s výhľadom na dva roky, priebežne bude monitorovaný, vyhodnocovaný a aktualizovaný. Zámerom je dosiahnuť kompatibilitu s programovými rozpočtami mesta Prešov a samospráv územia UMR Prešov. Finančný plán PHRSR UMR Prešov schvaľuje mestské/obecné zastupiteľstvo v rámci schvaľovania

rozpočtu mesta/obce. Finančný plán stratégie PHRSR UMR Prešov tvoria vzájomne koordinované finančné plány mesta a obcí územia UMR Prešov. Finančný plán implementácie stratégie identifikuje finančné objemy, charakter (grantové, revolvingové, investičné, neinvestičné aspekty), zdroje a spôsoby financovania projektov (vlastné zdroje, úverové zdroje, verejné financie, súkromné zdroje, grantové schémy, a pod.). Implementáciu PHRSR UMR Prešov môžu ovplyvniť viaceré riziká a nepredvídané udalosti:

- nedostatočná koordinácia na národnej a regionálnej úrovni;
- nízka efektívnosť strategického riadenia regionálneho rozvoja;
- nedostatočný legislatívny a metodický rámec;
- nedostatočná efektívnosť a adresnosť verejných politík vrátane politiky regionálneho rozvoja (NSRR, PHRSR VÚC, miest a obcí),
- nízka súčinnosť s aktérmi regionálneho rozvoja pri tvorbe a implementácii stratégií regionálneho rozvoja,
- nedostatočná spolupráca a informačné toky medzi riadiacimi úrovňami (štátna - krajská - subregionálna - miestna) a sektormi (ministerstvá - rezortné inštitúcie - odborné útvary samospráv,
- nedostatok údajov, finančných a personálnych kapacít pre spracovanie a implementáciu stratégie a pod.).

Pri tvorbe strategického dokumentu bol spracovaný Plán riadenia rizík. V uvedenom pláne sú identifikované kľúčové problémy, ktoré môžu negatívne ovplyvniť napĺňanie cieľov a vízie PHRSR UMR Prešov. Plán obsahuje navrhované opatrenia na elimináciu rizík, vrátane zodpovednosti a termínov na plnenia navrhovaných opatrení. Proces riadenia rizík budú zabezpečovať Administratívne kapacity UMR Prešov v úzkej súčinnosti s pracovníkmi mestských a obecných úradov.

III. ZÁKLADNÉ ÚDAJE O SÚČASNOM STAVE ŽIVOTNÉHO PROSTREDIA DOTKNUTÉHO ÚZEMIA

1. Informácie o súčasnom stave životného prostredia vrátane zdravia a jeho pravdepodobný vývoj, ak sa strategický dokument nebude realizovať

Geologické pomery

Podľa tektonickej schémy slovenskej časti Západných Karpát (Biely et al. in Atlas krajiny SR, 2002) sa na území okresu Prešov nachádzajú nasledovné tektonické štruktúry:

• flyšové pásmo – magurský flyš	• sedimentárny obal veporika
• pieninské bradlové pásmo	• paleogénne vnútrokarpatské panvy
• kryštalinikum tatrika	• neogénne sedimentárne panvy
• sedimentárny obal tatrika	• neogénne vulkanity
• kryštalinikum veporika	

Obrázok 3 *Tektonická schéma*

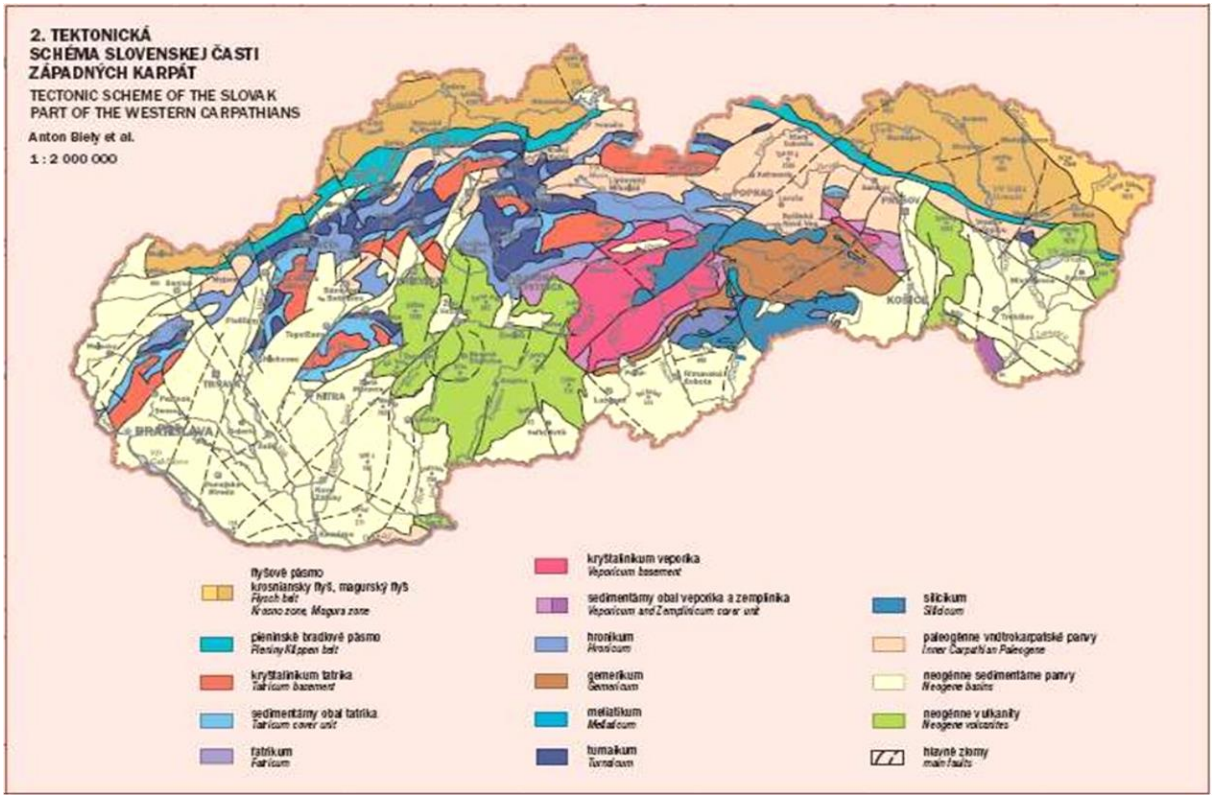

/Zdroj: RÚSES okresu Prešov, 2010/

Základné geochemické typy hornín

Na základe členenia autorov (Marsina, Lexa in Atlas krajiny SR, 2002) boli v riešenom území vyšpecifikované 4 základné geochemické typy hornín:

- andezity a intermediárne subvulkanické intruzíva,
- vápence a dolomity,
- ílovce a pieskovce,
- metapsamity, metapelity, prevažne kyslé metavulkanity a metavulkanoklastiká a intermediárne až bázické metavulkanity a metavulkanoklastiká s polohami slabo-metamorfovaných vápencov, dolomitov a magnezitov.

Obrázok 4 *Geochemické typy hornín okresu Prešov*

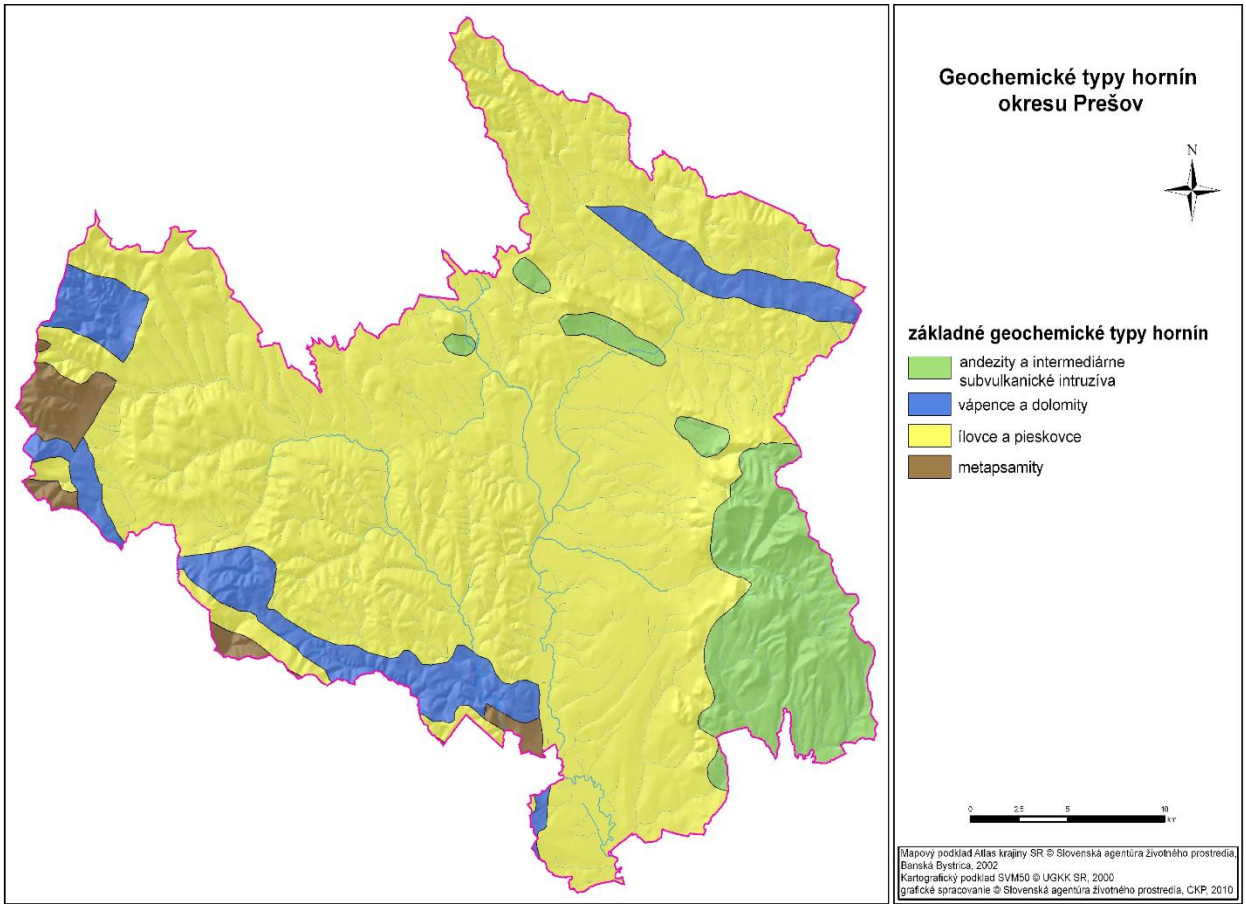

/Zdroj: RÚSES okresu Prešov/

Geomorfologické pomery

Riešené administratívne územie okresu Prešov z hľadiska geomorfologických pomerov (Geomorfologické členenie SSR a ČSSR, 1986) patrí do alpsko-himalájskej sústavy, do podsústavy Karpaty, k provinciám:

- Západné Karpaty (subprovincie: Vnútorné Západné Karpaty, Vonkajšie Západné Karpaty),
- Východné Karpaty (subprovincia: Vonkajšie Východné Karpaty) (obrázok č. 5).

Tabuľka 2 *Územie okresu Prešov z hľadiska geomorfologických pomerov*

Subprovincia	Oblasť	Celok	Podcelok	Časť
Vnútorné Západné Karpaty	Slovenské rudohorie	Čierna hora	Roháčka	
			Bujanovské vrchy	
			Sopotnické vrchy	
			Hornádske predhorie	
	Fatransko-tatranská oblasť	Branisko	Smrekovica	
			Sľubica	
	Lučensko-košická zníženina	Košická kotlina	Toryská pahorkatina	
	Matransko-slanská oblasť	Slanské vrchy	Šimonka	Zlatobanská kotlina
				Oľšavské predhorie
				Lúčinská brázda
			Makovica	
Vonkajšie Západné Karpaty	Východné Beskydy	Čergov		
	Podhôľno-magurská oblasť	Spišsko-šarišské medzihorie	Šarišské podolie	Šarišský vrch
			Stráže	
		Bachureň		
		Šarišská vrchovina		Širocká brázda
				Sedlická brázda
				Chminianska brázda
Vonkajšie Východné Karpaty	Nízke Beskydy	Ondavská vrchovina		Raslavická brázda
		Beskydské predhorie	Záhradnianska brázda	
			Hanušovská pahorkatina	

/Zdroj: geomorfologické členenie SSR a ČSSR, Slovenská kartografia, 1986/

Najvyšší bod okresu (1 171,1 m n. m.) sa nachádza v pohorí Branisko, najnižší bod okresu (198 m n. m.) sa nachádza v alúviu rieky Torysa v katastrálnom území obce Seniakovce.

Obrázok 5 *Geomorfologické jednotky okresu Prešov*

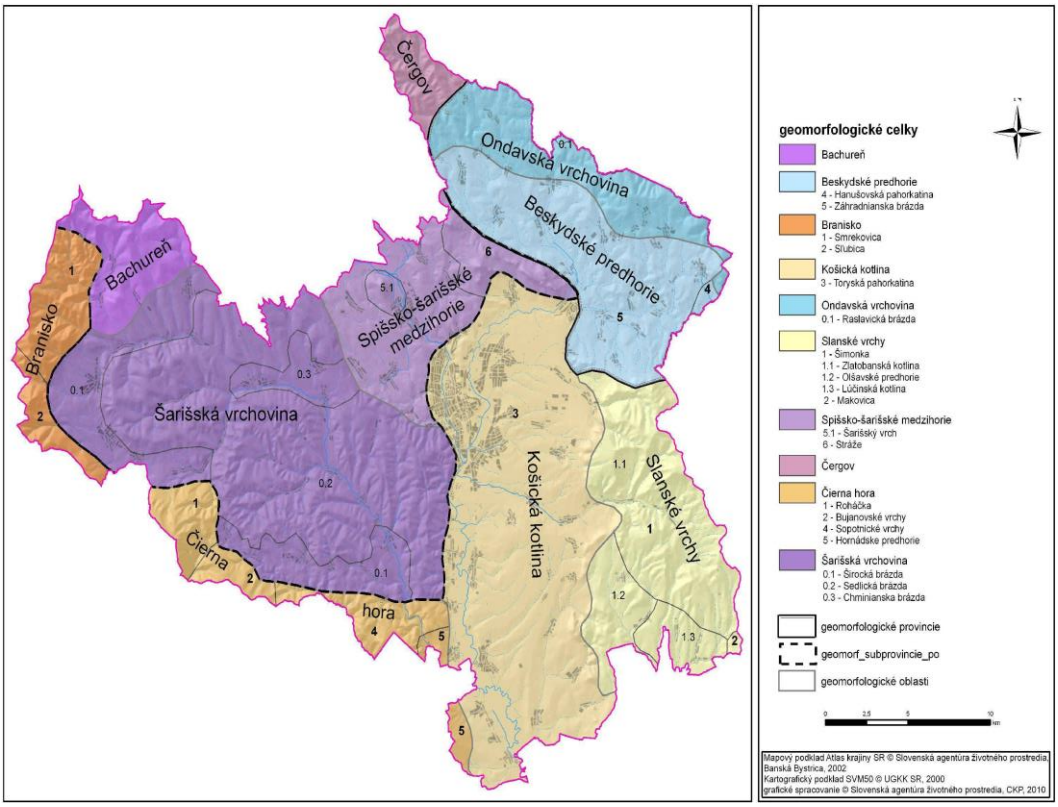

/Zdroj: RÚSES okresu Prešov/

Charakteristika štruktúr

Riešené územie okresu Prešov v zmysle členenia podľa základných morfoštruktúr (Mazúr, Činčura, Kvitkovič: Geomorfológia. Atlas SSR, SAV, SÚGK, Bratislava, 1982) zaraďujeme do nasledovných kategórií:

A. vrásovo-bloková fatransko-tatranská morfoštruktúra:

A.1 prechodné štruktúry centrálnokarpatských vrchovín (centrálnokarpatský paleogén: Šarišská vrchovina – časť, Spišsko-šarišské medzihorie – časť, Beskydské predhorie - časť)

A.2 pozitívne morfoštruktúry – hraste a klinové hraste jadrových pohorí (Branisko)

A.3 hraste a klinové hraste centrálnokarpatských flyšových pohorí (Bachureň)

B. semimasívna rudohorská morfoštruktúra: semimasívny mierne vyklenutý blok (Čierna hora – časť)

C. bloková slansko-matranská a vihorlatská morfoštruktúra: pozitívne morfoštruktúry – hraste a diferencované bloky (Slanské vrchy – časť)

D. morfoštruktúry lučensko-košickej zníženiny – výrazne negatívne morfoštruktúry – priekopové prepadliny (Košická kotlina – časť bez alúvia rieky Torysa)

E. morfoštruktúrna depresia peripieninského (pribradlového) lineamentu – negatívne a prechodové vrásovo- blokové a šupinové štruktúry (Spišsko-šarišské medzihorie – vrchovinová časť)

F. negatívne morfoštruktúry panónskej panvy – mierne diferencované štruktúry bez agradácie (Spišsko-šarišské medzihorie – pahorkatinová časť)

G. zlomovo-vrásové štruktúry flyšových Karpát

G.1 pozitívne vysoko vyzdvihnuté blokové štruktúry (Čergov)

G.2 morfoštruktúrna transverzálna depresia Nízkych Beskýd (Beskydské predhorie – časť)

Typy erózno-denudačného reliéfu

- hornatinový reliéf: najvyššie polohy pohorí (Slanské vrchy, Branisko, Čierna hora, Čergov),
- vrchovinový reliéf: nižšie polohy pohorí (Slanské vrchy, Čierna hora), Šarišská vrchovina – časť,
- reliéf pedimentových podvrchovín a pahorkatín (časť predhoria Slanských vrchov, Šarišská vrchovina – časť, Ondavská vrchovina – časť, Spišsko-šarišské medzihorie – časť, Beskydské predhorie - časť),
- planačno-rázsochový reliéf (Šarišská vrchovina – časť, Branisko – časť),
- reliéf nekrasových planín (Spišsko-šarišské medzihorie – časť),
- reliéf eróznych brázd (Šarišská vrchovina – časť, Ondavská vrchovina – časť, Spišsko-šarišské medzihorie – časť),
- reliéf kotlinových pahorkatín (Košická kotlina – časť),
- reliéf nív a rovín (Košická kotlina – alúvium rieky Torysa).

Obrázok 6 *Geomorfologické podmienky okresu Prešov*

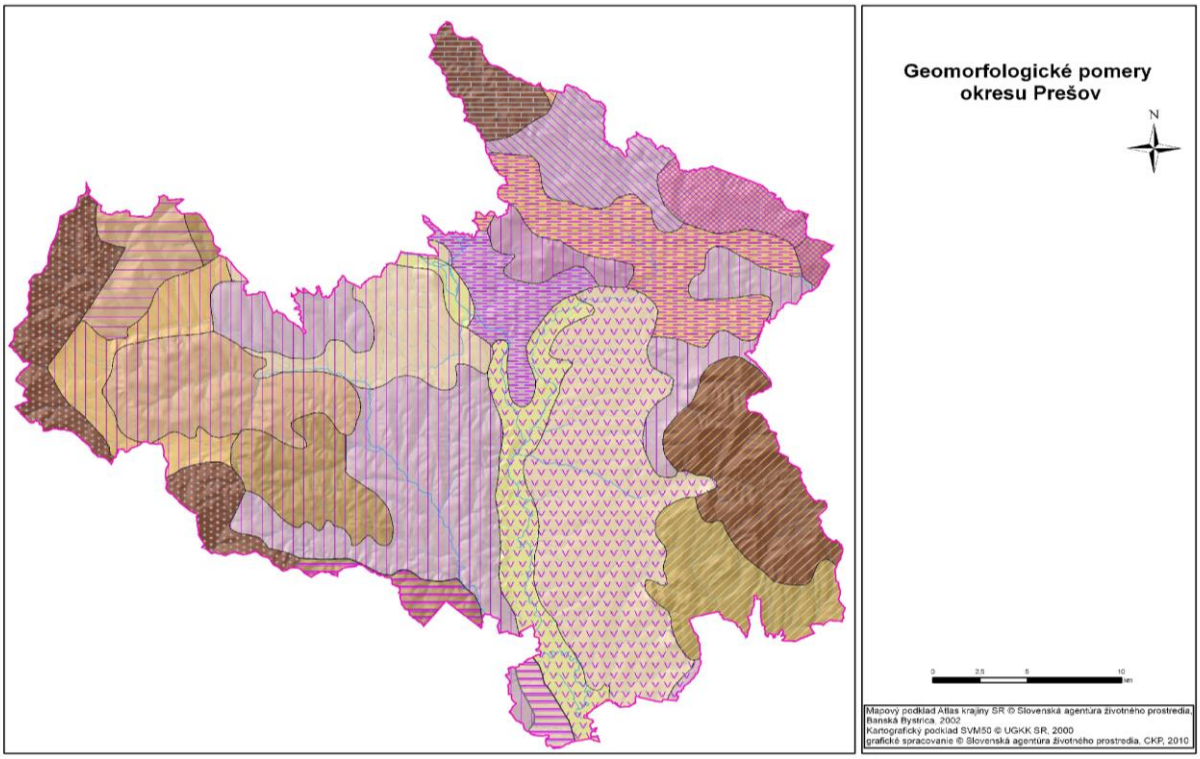



/Zdroj: RÚSES okresu Prešov, 2010/

Morfologicko-morfometrické typy reliéfu

Na základe členenia podľa kategorizácie morfologicko-morfometrických typov reliéfu (Atlas krajiny SR, 2002) nachádzame v riešenom území nasledovné základné morfologicko-morfometrické typy reliéfu, ktoré sú vykreslené na obrázku č. 7 (číslovanie typov je uvedené podľa zdroja údajov):

Roviny:

1 - nerozčlenené

Pahorkatiny:

4 - mierne členité 5 - stredne členité 6 - silne členité

Vrchoviny:

7 - stredne členité 8 - silne členité

9 - veľmi silne členité

Nižšie hornatiny:

11 - silne členité

12 - veľmi silne členité

Obrázok 7 *Morfologicko-morfometrické typy reliéfu okresu Prešov*

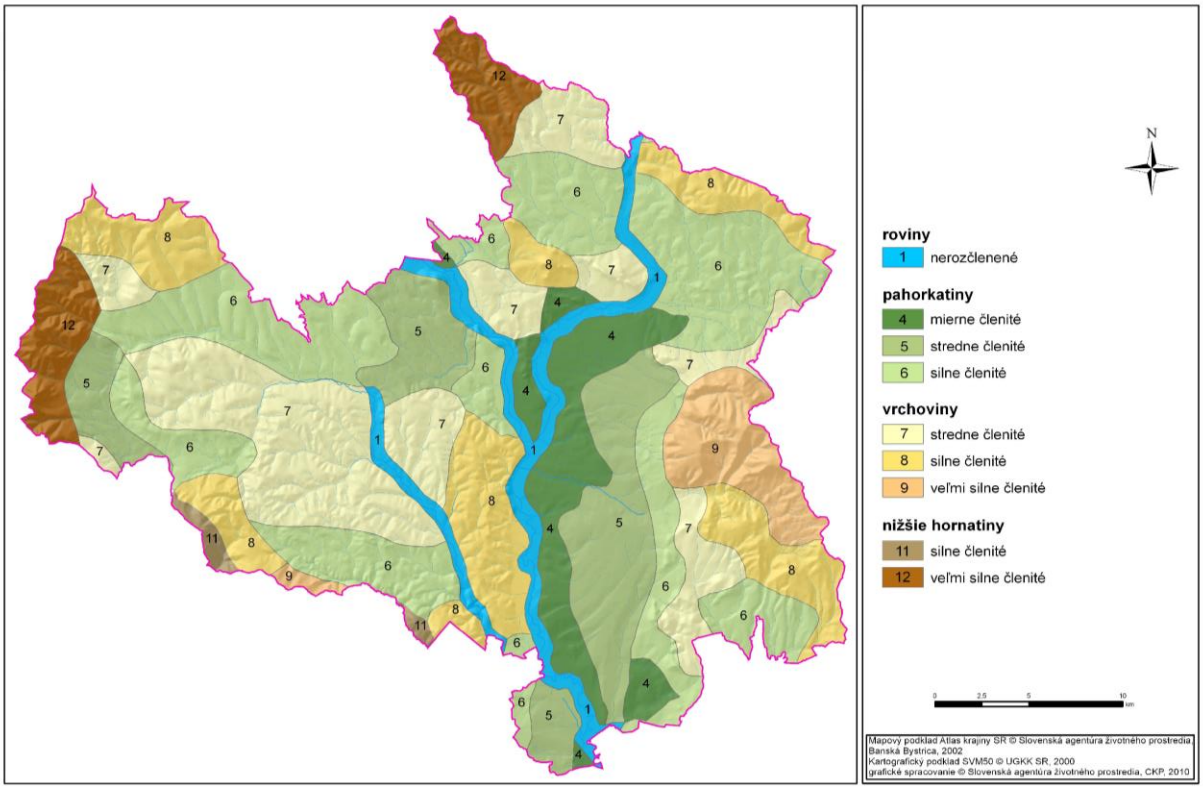

/Zdroj: RÚSES okresu Prešov, 2010/

Morfometrická charakteristika

Sklonitosť

Sklonitosť reliéfu sa využíva predovšetkým pri stanovovaní rýchlosti odnosu vody a materiálu po svahu, limituje lokalizáciu aktivít v krajine. Interpretácia má veľký význam, napr. pre lokalizáciu výstavby, investičnú náročnosť, možnosť obhospodarovania a vstupuje do limitov, napr. erodovateľnosti a delimitačných kritérií.

Podľa všeobecných morfometrických charakteristík je územie okresu z hľadiska sklonitosti rozčlenené do šiestich intervalov (0-3o, 3-7o, 7-12o, 12-17o, 17-25o, 25o a viac).

Najviac členený reliéf je charakteristický pre pohoria Čergov, Branisko, Čierna hora a Slanské vrchy (obrázok 8). Tieto pohoria zaradzujeme medzi nižšie hornatiny, prípadne vrchoviny. Vysoká sklonitosť 17 – 25° je charakteristická aj pre niektoré svahy Šarišskej vrchoviny, Ondavskej vrchoviny a Stráže (sú súčasťou Spišsko – šarišského medzihoria). Podstatná časť okresu Prešov má sklonitosť 7 – 12°. Najnižšie sklony svahov (0 - 3 - 7°), miestami až rovinatý reliéf je v údolniciach riek Torysa, Sekčov a Svinka a v Košickej kotline, ktorej súčasťou je aj Toryská pahorkatina. V týchto častiach okresu je odnos materiálu a s tým súvisiaca potenciálna erózia najnižšia, sú však intenzívne obhospodarované a pri nešetrnom obrábaní a zlých agrotechnických opatreniach môže aj tu dôjsť k zvýšeniu povrchového odtoku a zvýšenej vodnej erózii. Najstrmšie časti okresu, ktoré sú prevažne zalesnené, majú aj najvyššiu potenciálnu eróziu, čo môže pri ich nevhodnom hospodárskom spôsobe spôsobiť taktiež problémy s vodnou eróziou, a to hlavne na flyšovom podloží Čergova a v niektorých častiach Šarišskej vrchoviny, ktorá je z veľkej časti odlesnená a využívaná ako poľnohospodárska pôda. Na niektorých miestach je tu potrebné prehodnotiť spôsob využívania krajiny.

Z tejto charakteristiky reliéfu vyplýva, že reliéf okresu Prešov je tvorený v jeho okrajových častiach svahmi s vysokými sklonmi, v centrálnej časti strednými sklonmi a vo východnej časti v Košickej kotline nízkymi sklonmi, kde je reliéf priaznivý na výstavbu a ostatné socio-ekonomické aktivity.

Obrázok 8 *Sklonitosť svahov okresu Prešov*

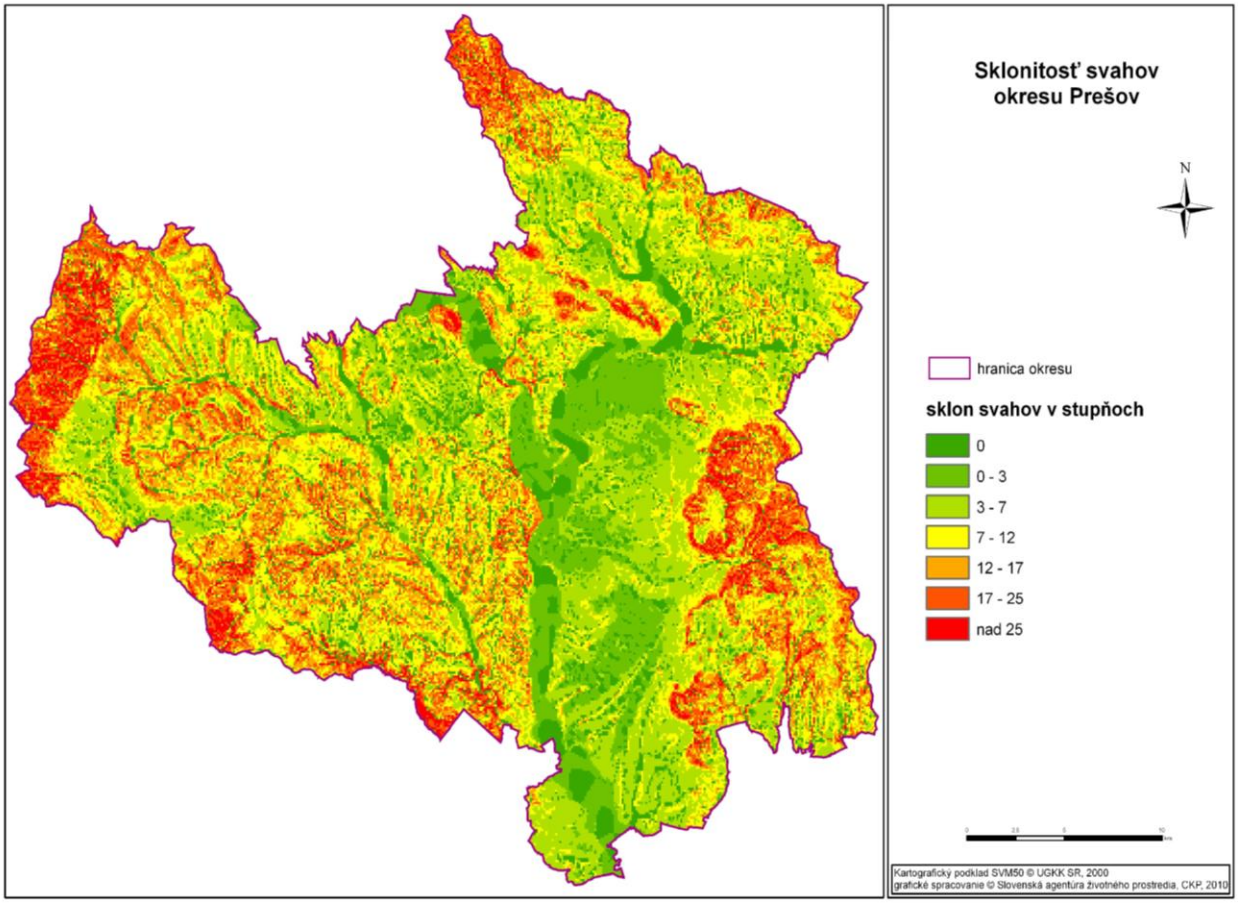

/Zdroj: RÚSES okresu Prešov, 2010/

Expozícia

Poloha svahu s ohľadom na slnečné žiarenie, osvetlenie, vietor a zrážky sa člení podľa svetových strán. Ide o orientáciu reliéfu, ktorá je dôležitá pre stanovenie podkladov pre mikroklímu územia, lokalizáciu poľnohospodárskych plodín, športových aktivít a pod. Rovinatý reliéf sa vyskytuje hlavne v údolí Torysy, čiastočne i Svinky (obrázok č. 9). Severné a západné expozície prevládajú v severnej časti Slanských vrchov, v Čiernej hore a roztrúsene v Šarišskej vrchovine, v ktorej sú rovnomerne zastúpené ostatné orientácie. Branisko, Čergov a západná časť Košickej kotliny majú väčšinu svahov exponovanú na východ a juhovýchod, prípadne na juh a juhozápad. Západné a juhozápadné orientácie svahov prevládajú vo východnej časti Košickej kotliny. Severovýchodné svahy sa v rámci okresu najviac vyskytujú na Branisku, Čiernej hore (Sopotnických vrchoch) a v severnej a centrálnej časti Šarišskej vrchoviny.

Obrázok 9 *Orientácia svahov okresu Prešov*

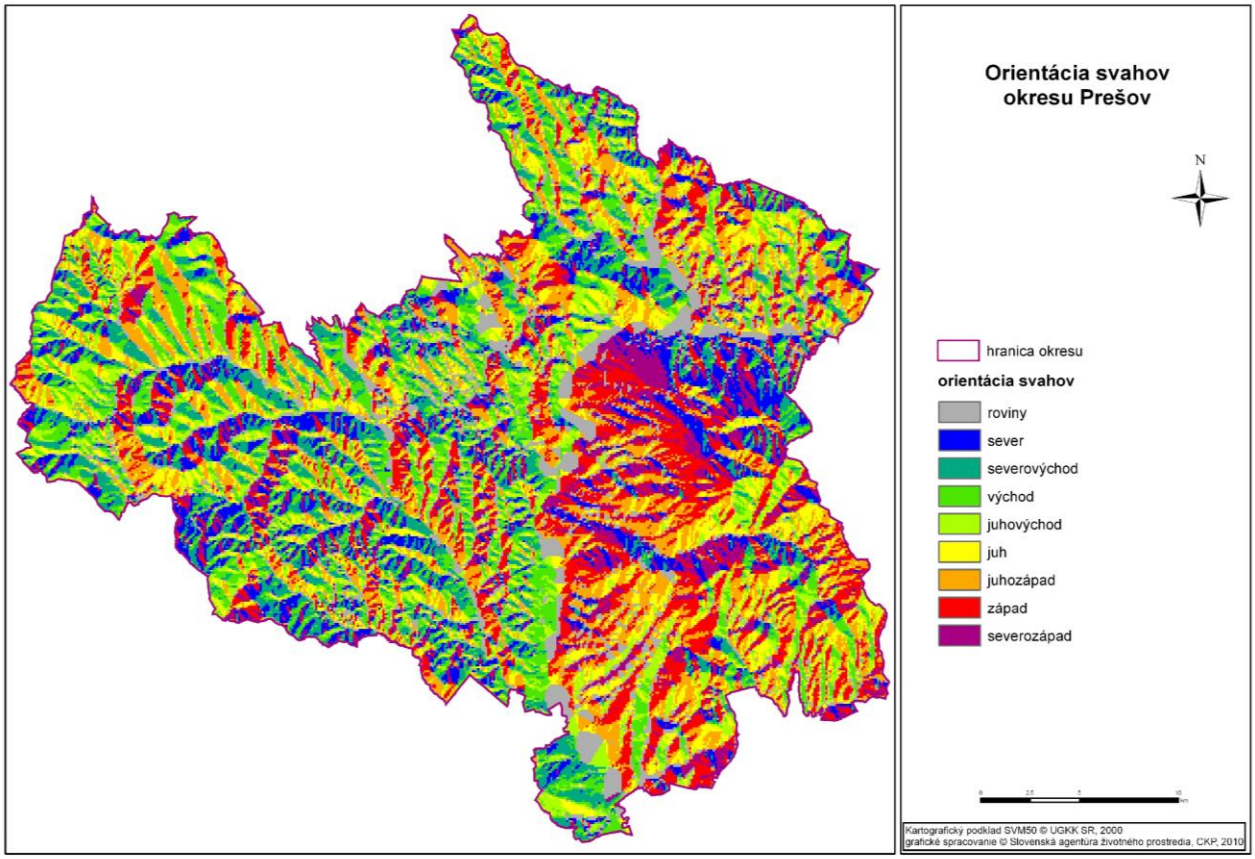

/Zdroj: RÚSES okresu Prešov, 2010/

Insolácia

Pri insolácii (inak oslnení) reliéfu ide o priame slnečné žiarenie dopadajúce na zemský povrch a jeho množstvo závisí od výšky Slnka, intenzity žiarenia, od sklonu a expozície povrchu. Z pozorovaní sa zistilo, že najvyššie hodnoty insolácie majú v dopoludňajších hodinách východné a juhovýchodné svahy. V popoludňajších hodinách zas západné a z časti aj severozápadné a severné svahy miernejšieho sklonu do 12o. Strmo sa zvažujúce svahy všetkých expozícií v rámci pohorí okresu vykazujú v závislosti od sklonu a členitosti reliéfu malé insolačné hodnoty. Výnimkou sú zarovnané a z časti odlesnené vrcholové partie a pretiahnuté sedlá, kde sledujeme opäť vyššie hodnoty insolácie. V rámci okresu vykazujú najväčšie hodnoty insolácie juhovýchodné, južné a juhozápadné svahy Stráží, Čergova a Braniska. Najnižšie hodnoty insolácie vykazujú severné a severovýchodné strmé svahy najmä v Slanských vrchoch, Čiernej hore, Strážach a Šarišskej vrchovine.

Pedologické pomery

Pôdne pomery hodnotenie pôdnych pomerov vychádza zo spracovaného materiálu Hydrogeologický plán povodia Hornádu (MŽP SR, SHMU Bratislava, 2002). Na území okresu Prešov boli v minulosti vykonané viaceré mapovacie práce, ktorých výsledky boli podkladom pre zostavenie pôdnej mapy (Tobrman, 1965, 1966, 1970;Tobrman – Sedlák, 1967; Čurlik et al., 1994a, 1994b, 1998). Pôdna mapa bola zostavená podľa metodiky pre zostavenie pôdnych a pedogeochemických máp (Čurlik - Šefčik - Šurina, 1997) a pôdne jednotky boli klasifikovane v zmysle morfogenetického klasifikačného systému pod Slovenska (Kolektív, 2000). Mapovacie jednotky nie sú taxonomické jednotky (pôdny typ, subtyp, varieta, forma, druh, substrát), ale pôdne asociácie a komplexy. Tieto mapovacie jednotky znázorňujú reálne areály rozšírenia pôd. Mapovacie jednotka v prípade asociácií a komplexov vyjadruje členenie na dominantne (>50 %), sprievodne a sporadické (<10 %) jednotky. Pôdna asociácia - rozumieme pod tým skupinu geograficky spríbuznených pôd, z ktorých každá je spätá s určitým výsekom krajiny a ktorý sa vyskytuje s určitým stupňom pravdepodobnosti. Tato asociácia je pomenovaná podľa jedného alebo niekoľkých základných členov tejto skupiny. Pri zostavovaní pôdnych máp menších mierok spájame príbuzne pôdne jednotky do väčších celkov a vytvárame pôdne asociácie. Je to vlastne spájanie príbuzných jednotiek, ktoré sa dajú v teréne samostatne mapovať. Pôdne asociácie majú svoju vnútornú logiku a sú to pôdne sekvencie, ktoré sú vyvinuté na rovnakých substrátoch s rovnakou zrnitosťou, ale majú inú drenáž a iný vzťah k topografickej pozícii. Pôdny komplex je súbor pôd, ktorý sa dá síce rozčleniť na jednoduché pôdne jednotky, ale len v detailných mapových mierkach. Najrozšírenejšie pôdnych asociácií a pôdnych typov sú charakterizované podrobnejšie v ďalšom texte. Skupiny pôdnych typov okresu Prešov sú znázornené na nasledujúcom obrázku č. 10 (Atlas krajiny SR, 2002). Podrobnejšia charakteristika pôdnych typov na poľnohospodárskej pôde okresu Prešov spracovaná VUPOP je priložená pre porovnanie.

Pôdne druhy

Kategorizácia pôdnych druhov je spracovaná podľa podkladu Čurlík, Šály - Zrnitosť pôdy (in Atlas krajiny SR, 2002), pričom v riešenom území rozlišujeme kategórie pôd z hľadiska zrnitostných tried a kamenitosti (štrkovitosti):

Zrnitostné triedy: hlinito-piesčitá, piesčito-hlinitá, hlinitá, ílovito-hlinitá, ílovitá

Kamenitosť (štrkovitosť): neskeletnaté až slabo kamenité (0 – 20 %), strednekamenité (štrkovité) (20 – 50%)

Obrázok 10 *Pôdne typy poľnohospodárskych pôd okresu Prešov*

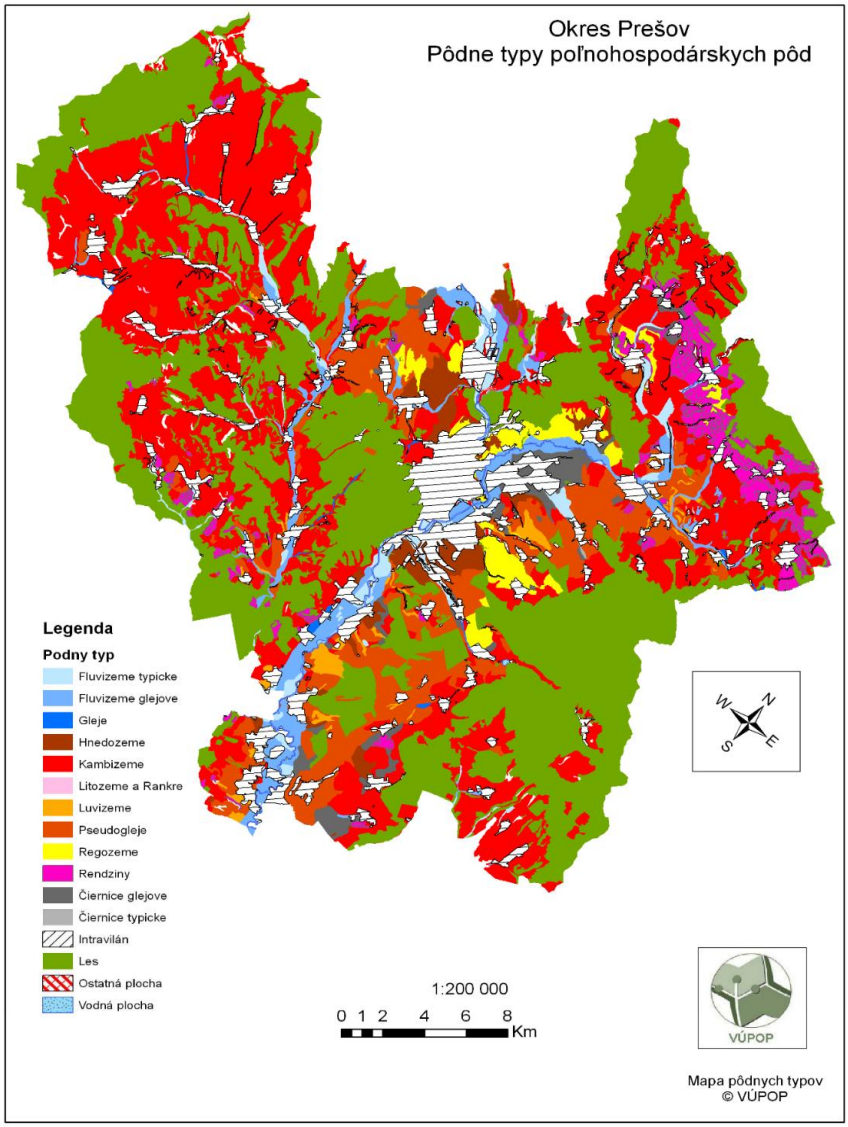

/zdroj: VUPOP/

Hydrologické a hydrogeologické pomery

Hydrograficky územie okresu Prešov patrí do povodia Hornádu, iba nepatrná časť na severovýchode je odvodňovaná tokmi ústiacimi do Tople. Hlavným tokom je Torysa, ktorá svojimi prítokmi odvodňuje podstatnú časť územia.

Značná časť patrí do povodia Svinky a v juhozápadnej časti sú menšie toky ústiace do Hornádu (Atlas krajiny SR, 2002). Vodohospodársky významnou oblasťou okresu Prešov je alúvium Torysy.

Na všetkých odberných objektoch v povodí rieky Torysy, ktoré sú využívané pre hromadné zásobovanie

obyvateľstva pitnou a úžitkovou vodou, boli stanovené pásma hygienickej ochrany I. a II. stupňa. Ďalšími zdrojmi pitnej vody sú lokálne zdroje zásobujúce obecné vodovody. Pásma hygienickej ochrany sú vymedzené vodohospodárskym orgánom a majú miestny význam. Vodohospodársky významnými tokmi sú Svinka, Malá Svinka, Torysa, Sekčov, Delňa a Ternianka. Rieka Sekčov patrí v hierarchii vodných tokov do VI. rádu, je to ľavostranný prítok Torysy, do ktorej ústi v Prešove. Jeho celková dĺžka je 44 km a veľkosť povodia 355 km2. Najvodnatejším mesiacom je na Sekčove všeobecne apríl, kedy sa mesačný priemer pohybuje od 1,8 do 2,2 násobku dlhodobého priemeru. Povodie Torysy patrí do oblasti stredohorskej, nižšieho stredohorského stupňa B - 2, ktorý je charakteristický tým, že tu v prvom polroku odtečie 50 – 60 % z celkového ročného odtoku. Podružné maximum pripadá na október (obdobie jesenných dažďov), kedy mesačné prietoky dosahujú 1,2 - 1,4 násobku dlhodobého priemeru. Minimálne mesačné prietoky sú na Sekčove všeobecne v auguste a septembri (málo zrážok, pomerne vysoká teplota a s tým súvisiaci výpar). Podružné minimum je v januári alebo prípadne ešte v mesiaci december. Najmenej vyrovnaný prietok má Sekčov v júni a v auguste, vyrovnanejšie sú zimné mesiace január a február a tiež júl (Tabuľka 3).

Tabuľka 3 *Charakteristické hydrologické údaje vodných tokov Torysa a Sekčov v meste Prešov*

Tok	**Miesto**	**Plocha povodia (km^2)**	**Zrážky (mm)**	**Straty (mm)**	**Odtok (mm)**	**Odtokový koeficient**	**Špecifický odtok ($l.s^{-1}.km^{-2}$)**	**Prietok ($m^3.s^{-1}$)**
Torysa	Prešov	673,89	739	540	199	0,27	6,32	4,54
Sekčov	Prešov	352,80	693	490	203	0,29	6,41	2,30
Tok	**Miesto**	**Prietoky prekročené priemerne počas M dní v roku ($m^3.s^{-1}$)**						
		30	**90**	**180**	**270**	**330**	**355**	**364**
Torysa	Prešov	10,3		2,79	1,64		0,77	0,490
Sekčov	Prešov	5,2		1,41	0,83		0,39	0,122
Tok	**Miesto**	**Veľké vody dosiahnuté alebo prekročené raz za N rokov ($m^3.s^{-1}$)**						
		1	**2**	**5**	**10**	**20**	**50**	**100**
Torysa	Prešov	54	84	129	165	195	253	300
Sekčov	Prešov	35	55	90	118	152	202	250

/Zdroj: HEP povodia Hornádu, MŽP SR SHMÚ, 2002/

Vodné toky

Z hľadiska hydrogeografických charakteristík územie okresu Prešov patri k úmoriu Čierneho mora, zbernej oblasti rieky Tisa, sústave rieky Slaná, do povodia rieky Hornád. Hydrologickou osou tohto územia sú rieka Torysa so svojím ľavostranným prítokom Sekčov a rieka Svinka vznikajúca sútokom Veľkej a Malej Svinky pri obci Kojatice. Rieka Torysa (P = 1 349 km2, L = 129 km, Qmax = 7,09 m3. s-1 v Košických Olšanoch) je najvýznamnejším ľavostranným prítokom rieky Hornád odvodňujúca východnú a južnú časť Levočských vrchov, severnú časť pohoria Bachureň, západnú a čiastočne i južnú časť pohoria Čergov, Spišsko – šarišské medzihorie, západnú časť Slánskych vrchov a severnú časť Košickej kotliny. V meste Prešov rieka Torysa priberá svoj najvýznamnejší prítok rieku Sekčov. Významným ľavostranným prítokom rieky Torysa na území okresu je potok Delňa (priemerný prietok 0,31 m3. s-1). Rieka Sekčov pramení v pohorí Čergov pod Bukovým vrchom (1 020 m.n.m.), územím okresu Prešov od Demjaty po Kapušany tečie južným, od Kapušian až po ústie do Torysy už juhozápadným smerom a odvodňuje juhovýchodnú časť pohoria Čergov, západnú časť Beskydského predhoria a severozápadnú časť Slánskych vrchov. Najvýznamnejším ľavostranným prítokom je potok Ladianka. Veľká Svinka pramení v pohorí Branisko pod vrcholom Smrekovica (1 200 m.n.m.) a odvodňuje východnú časť pohoria Branisko a západnú časť Šarišskej vrchoviny. Svinka prameniaca v centrálnej časti pohoria Bachureň pod vrcholom Javor (931 m.n.m.) odvodňuje vnútornú, centrálnu časť tohto pohoria i severovýchodnú časť Šarišskej vrchoviny. Do vodného toku Svinka v rkm 23,300 pri obci Kojatice zausťuje vodný tok Malá Svinka.

Sústavu významných vodných tokov na juhozápade okresu Prešov dopĺňajú ľavostranné prítoky rieky Hornád, potok Sopotnica odvodňujúci oblasť Sedlickej brázdy a Dolinský potok čiastočne odvodňujúci oblasť Širockej brázdy.

Hydrogeologické pomery

Z hľadiska hydrogeologických pomerov v priestore fluviálnych náplavov rieky Torysa i jej najväčšieho prítoku rieky Sekčov tvorených štrkmi a pieskami prevláda mierna prietočnosť a hydrogeologická produktivita (T = 1.10-4 – 1.10-3 m2.s-1). Hydrogeologický rajón Neogén východnej časti Košickej kotliny je budovaný neogénnymi sedimentmi s polohami štrku a piesku. Hrúbka štrkových náplavov dosahuje 3 – 5 m s priemernou výdatnosťou 1,0 – 2,0 l.s-1. Podzemné vody sa v tomto prostredí tvoria okrem infiltrácie zo zrážkových a povrchových vôd i prestupovaním vôd z priľahlých neovulkanitov Slanských vrchov (Polák, 1992).

Zrážky

Z hľadiska ročného chodu zrážok na území okresu Prešov spadne maximum zrážok v mesiacoch jún a júl, minimum zrážok sa vyskytuje spravidla v mesiaci február. Z hľadiska priemerných ročných hodnôt klimatického ukazovateľa závlahy v časovom období 1961-1990 (Atlas krajiny SR, 2002) v predmetnom území boli hodnoty uvedeného ukazovateľa zaznamenané od 0 (Košická kotlina) do 100-200 (Spišsko - Šarišské medzihorie, Šarišská vrchovina)) do 300 - 400 mm (Branisko, Bachureň, Čergov, vrcholové polohy Slanských vrchov, Čierna hora), t.j. táto oblasť vykazuje veľmi mierny až stredný nadbytok zrážok. Z pohľadu priemerných ročných hodnôt radiačného indexu sucha (B0 /L . R, B0 – celková radiačná bilancia, L – skupinové výparné teplo, R – atmosférické zrážky) v časovom období 1961 – 1990 (Atlas SR, 2002), prevládajú hodnoty od 0,75 do 1,00 (Košická kotlina, Spišsko – Šarišské medzihorie, Beskydské predhorie, východná časť Šarišskej vrchoviny), od 0,50 do 0,75 (západná časť Šarišskej vrchoviny, Čierna hora, nižšie polohy Slanskej vrchoviny) až po hodnoty do 0,50 (Branisko, Čergov, vrcholové polohy Slanských vrchov). Priemerné ročné úhrny zrážok v období rokov 1961-1990 (Atlas krajiny SR, 2002) sa na väčšine územia okresu Prešov pohybovali od 600 do 700 mm, len v oblasti Branisk, Čierna Hora, Čergov a Slanské vrchy v intervale od 700 do 900 mm. Absolútne maximum mesačných úhrnov zrážok v časovom období 1951-2000 (Atlas krajiny SR, 2002) sa na väčšine územia okresu Prešov pohybovalo od 200 do 250 mm, len v oblasti Branisk, Čierna Hora, Čergov a Slanské vrchy v intervale od 250 do 350 mm.

Priemerné úhrny zrážok v januári v časovom období 1961-1990 (Atlas krajiny SR, 2002) sa na väčšine územia okresu Prešov pohybovali od 20 do 30 mm, len v oblasti Braniska, Čergova a Slanských vrchov v r. interval od 30 do 50 mm. Priemerné úhrny zrážok v júli v období 1961-1990 (Atlas krajiny SR, 2002) sa na väčšine územia okresu Prešov pohybovali od 80 do 100 mm, len v oblasti Braniska, Čergova a Slanských vrchov v r. interval od 100 do 120 mm. Z hľadiska výskytu hmiel patrí oblasť Košickej kotliny do oblasti nížin so zníženým výskytom hmly (priemerný ročný počet dní s hmlou od 20 do 45 dní), Spišsko - Šarišské medzhorie a predhorie Beskýd do hl. oblasť dolín väčších riek (priemerný počet dní s hmlou od 60 do 85 dní), úzke údolie rieky Svinka až oblasť dolín horských potokov (priemerný počet dní s hmlou od 50 do 60 dní), Šarišská vrchovina, Čierna hora a nižšie polohy Slanských vrchov do oblasti zníženého výskytu hmiel – podhorské až horské svahové polohy (priemerný počet dní s hmlou od 20 do 50 dní) a Branisko, Čergov a vrcholové polohy Slanských vrchov do oblasti horských advektívnych hmiel (priemerný počet dní s hmlou od 70 do 300 dní).

Obrázok 11 Klimatické oblasti okresu Prešov

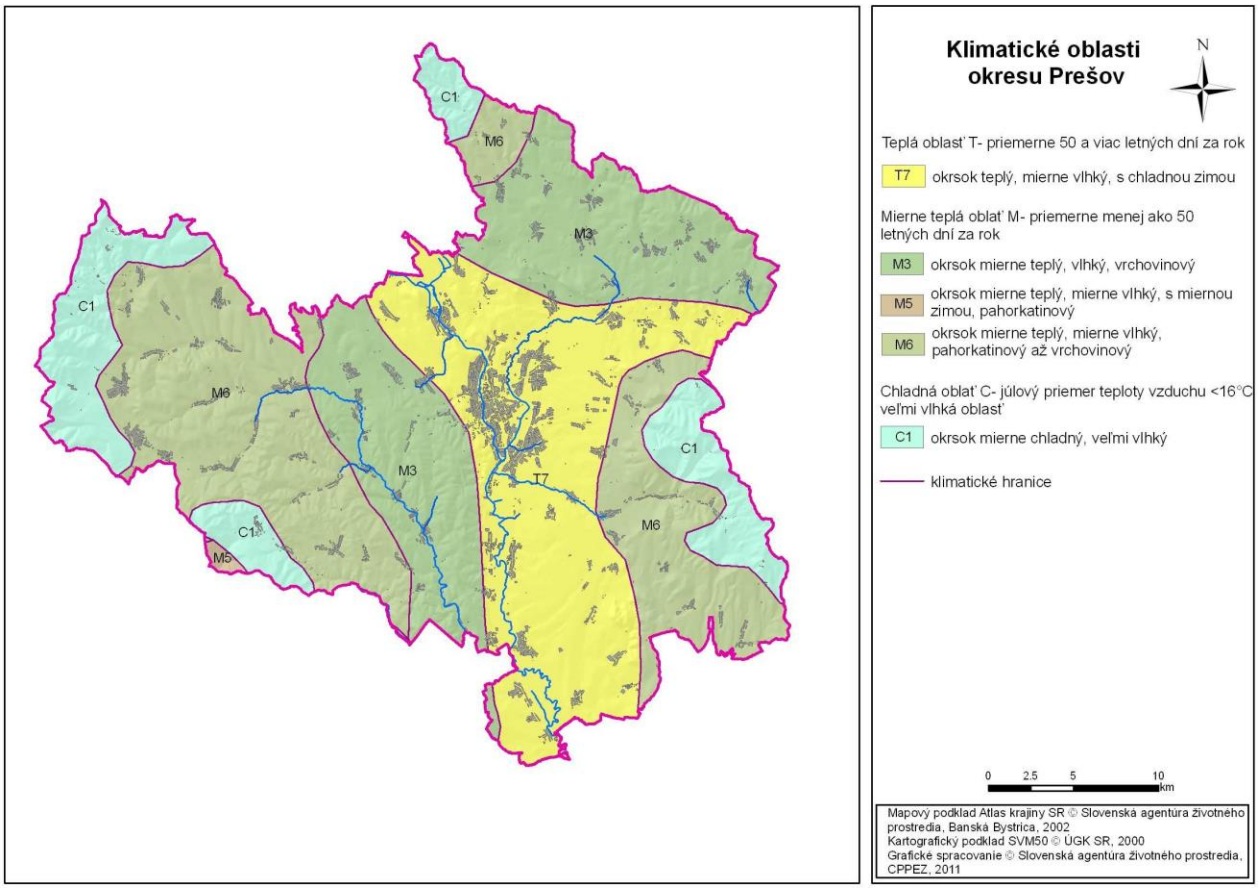

/Zdroj: ÚSES okresu Prešov, 2010/

Biotické pomery

- **Reálna vegetácia**

Prešovský okres je najväčší v celom Prešovskom kraji. Zo severu a severovýchodu ho lemujú Ondavská vrchovina a Čergov. Na juhovýchode tvoria hranicu Slanské vrchy a z južnej časti Košická kotlina s Čiernou horou. Osou okresu je rieka Torysa. Jej údolím, resp. po západných a východných svahoch Slanských vrchov, prenikli ďalej na niekoľko panónskych prvkov flóry. Zastúpené sú hlavne na suchomilných a teplomilných stanovištiach okresu. Silne pozmenená je v okrese vegetácia podmáčaných plôch, mokradí a stojatých či tečúcich vôd. Dnes túto vegetáciu reprezentujú iba fragmenty mokraďových spoločenstiev. Pre získanie informácií o biote (rastlinstve i živočíšstve) územia okresu Prešov o jeho vegetačných a floristických pomeroch, genofondových plochách, ekologických významných segmentoch a významných prvkoch R- ÚSES sa opieralo o niekoľko typov podkladov:

- publikované správy
- vlastne terénne pozorovania
- terénneho pozorovania ŠOP SR, RCOP v Prešove a ďalších externých spolupracovníkov
- literárne údaje

- **Všeobecná charakteristika vegetácie**

Súčasný stav vegetačného krytu územia je výrazne odlišný od potenciálneho prirodzeného stavu. Jeho terajší stav je priamym odrazom antropogénneho vplyvu na prírodu. Podstatná časť územia je intenzívne poľnohospodársky využívaná, časť odlesnenej plochy sa využíva na urbanizačné účely. Pôvodná vegetácia sa zachovala väčšinou len na poľnohospodárske nevhodné alebo neprístupné územia. Základ reálnej vegetácie tvoria rastlinné spoločenstvá osídľujúce biotopy, zodpovedajúcie prírodným pomerom okresu. Zastúpené sú tu rastlinné spoločenstvá lesov, mokradí, pasienkov, lúk, skál, poľnohospodársky využívaných pôd a spoločenstvá intravilánov.

- **Lesná vegetácia**

Vegetačné pomery odrážajú vo svojom zložení základné geologicko-geomorfologické a klimaticko-ekologické vlastnosti jednotlivých ekotopov územia. Les tvorí najvyspelejšiu klimaticky podmienenú biocenózu, kde sú edifikátorom dreviny stromovitého vzrastu. Lesné porasty tvoria vždy základ ekologickej stability územia.

Územie okresu patrí do druhého (bukovo – dubového) až šiesteho (smrekového) lesného vegetačného stupňa a medzi všetkých zmiešaných lesov s prevahou listnatých drevín.

Podstatnú časť územia okresu v minulosti pokrývali lesy. Plošne najviac boli zastúpené hrabové a dubovo-hrabové porasty zväzu Carpinion betuli. Napriek tomu, že sa ich v značnej miere dotklo odlesnenie, pretože boli najľahšie dostupné výruby, stále patria k dominantným lesným porastom v okrese, aj keď na mnohých miestach už majú zmenenú druhovú skladbu. Jedná sa o kvetnaté mezofilné lesy s dobre vyvinutým stromovým, krovitým a bylinným poschodím. V stromovom poschodí dominuje dub zimný (Quercus petraea) a hrab obyčajný (Carpinus betulus). Často sú zastúpené aj javor poľný (Acer campestre), lipa malolistá (Tilia cordata), lipa veľkolistá (T. platyphyllos), čerešňa vtáčia (Cerasus avium) a buk lesný (Fagus sylvatica). Vtrúsený je aj dub žltkastý (Quercus daleschampii). V krovitej vrstve prevláda javor poľný (Acer campestre), zemolez obyčajný (Lonicera xylosteum), svíb krvavý (Cornus sanguinea), lieska obyčajná (Corylus avellana), hloh obyčajný (Crataegus laevigata). V bylinnom podraste je hojne zastúpená ostrica chlpatá (Carex pilosa), kyslička obyčajnú (Oxalis acetosella), bažanka trváca (Mercurialis perennis),

na vlhších miestach pristupujú papradka samičia (Athyrium filix-femina), para samčia Dryopteris i filix-mas a.

Zastúpené sú napr. pri Kapušanoch, Finticiach, Malom a Veľkom Šariši, Prešove, Chmeľove, **Haniske**, Ľubovci a inde. Dubovo – hrabové lesy sú rozšírené v nižšom stupni aj po celom obvode Slanských vrchov. V lesných porastoch južných expozícií prevládajú spoločenstvá xerotermných dubín zväzu Quercion pubescenti – petraeae. V drevinovom zložení okrem dubov, v ktorých býva primiešaný hrab i borovica lesná (Pinus sylvestris), jarabina brekyňová (Sorbus torminalis), javor poľný (Acer campestre) a i. V bylinnej zložke býva zastúpená kostrava rôznolistá (Festuca heterophylla), betonika lekárska (Betonica officinalis), fialka srstnatá (Viola hirta) a i. Zachovali sa v izolovaných ostrovčekoch pri Prešove, Kanaši, Gregorovciach, Malom Šariši, Veľkom Šariši, Terni, Šarišských Lúkach, Vydumanci a inde. Pri Záborskom, Petrovanoch, Drienove, Župčanoch, Lažanoch sa zachovali dubiny v podraste s nátržníkom bielym (Potentilla alba).

Dubové a borovicové lesy sa dnes zachovali už iba ako fragmenty pri Kapušanoch, Malom a Veľkom Šariši, Sedliciach. Severojužný smer Slanských vrchov a bezprostredný kontakt s panónskou oblasťou z východnej, južnej a západnej strany v značnej miere ovplyvňuje vegetačný kryt pohoria.

- **Rastlinstvo**

Podľa fytogeografického členenia Slovenska (Futak, 1980) patri podstatná časť územia do oblasti západokarpatskej flóry (Carpaticum occidentale), obvodu východobeskydskej flóry (Beschidicum orientale), fytogeografického okresu Východné Beskydy, podokresu Šarišská vrchovina. Ďalšie dva podokresy Čergov a Nízke Beskydy zasahujú iba okrajmi v severovýchodnej časti riešeného územia. Plošne menšia časť územia patrí do obvodu predkarpatskej flóry (Praecarpaticum), fytogeografickeho okresu Slanské vrchy. V západnej časti do územia svojim okrajom zasahuje i podokres stredné Pohornadie. Z hľadiska fytogeograficko-vegetačného členenia (Plesnik, 2002) patrí územie do dubovej zóny, horskej podtóny, flyšovej oblasti, podoblasti Šarišská vrchovina, kryštalicko-druhohornej oblasti, podoblasti Čierna hora a do sopečnej oblasti, podoblasti Slanské vrchy , severný podokres.

- **Potenciálna prirodzená vegetácia**

Potenciálna prirodzená vegetácia predstavuje vegetáciu, ktorá by sa v území vyvinula, keby na krajinu prestal pôsobiť svojou činnosťou človek. Je dôležite poznať, ktoré jednotky potenciálnej prirodzenej vegetácie by sa v území vyskytovali a ako by boli priestorovo rozložené - jednak z dôvodu možnosti presnejšieho hodnotenia pôvodnosti jednotlivých porastov a druhov, jednak pri návrhoch novej výsadby alebo doplnenia existujúcich porastov - tu by sa mali preferovať pôvodné druhy. Charakteristiku

základných mapovacích jednotiek potenciálnej prirodzenej vegetácie uvádzame podľa Maglockeho (Atlas krajiny SR, 2002). Na území okresu Prešov bolo vyčlenených 18 základných mapovacích jednotiek:

- U: Jaseňovo-brestovo-dubové lesy v povodiach veľkých riek (tvrdé lužné lesy)
- Al: Lužné lesy podhorské a horské
- C: Dubovo-hrabové lesy karpatské
- Ct: Zmiešané listnato-ihličnaté lesy v severných karpatských kotlinách
- Fs: Bukové kvetnaté lesy podhorské
- F: Bukové a jedľovo-bukové lesy
- Fc: Bukové lesy na vápencových a dolomitových podložiach
- Qa: Nátržníkové dubové lesy
- Qc: Dubové a cerovo-dubové lesy
- Jt: Javorovo-lipové lesy v nižších polohách
- PA: Jedľové a jedľovo-smrekové lesy
- Qm: xerotermné dubové lesy s dubom plstnatým a trávinné spoločenstvá na skalách
- Qk: dubové lesy na kyslých podložiach
- Fl: bukové lesy v horských polohách
- Jm: javorové lesy v horských polohách
- P: smrekové lesy čučoriedkové
- Ba: smrekové lesy zamokrené
- Pi: smrekovo-borovicové lesy a ostrevkové spoločenstvá

Prehľadnú situáciu potenciálnej prirodzenej vegetácie v okrese Prešov znázorňuje obrázok č. 12 (Atlas krajiny SR, 2002)

U - Jaseňovo-brestovo-dubové lesy v povodiach veľkých riek (tvrdé lužné lesy)

Do tejto jednotky patria vlhkomilne lesy na aluviálnych naplaveninách pozdĺž vodných tokov najmä v nížinách a teplejších oblastiach pahorkatín do 300 m n. m. Ekologicky ich ovplyvňujú zriedkavejšie a časovo kratšie periodicky sa opakujúce povrchové záplavy alebo kolísajúca hladina podzemnej vody. Vegetácia má bujný vzrast, lebo zásoby prístupných živín sú pomerne veľké a kvalitné. Súvisí to s periodicky sa opakujúcou sedimentáciou riečnych splavenín počas povrchových záplav. V drevinovom zložení sa uplatňujú najmä tvrdé lužné dreviny: jaseň úzkolistý (Fraxinus angustifolia), dub letný (Quercus robur),

brest hrabolistý (Ulmus minor), jaseň štíhly (Fraxinus excelsior), javor poľný (Acer campestre), čremcha obyčajná (Padus avium), medzi ktoré bývajú hojne primiešané aj niektoré dreviny mäkkých lužných lesov: napr. topoľ biely (Populus alba), topoľ čierny (Populus nigra), topoľ osika (Populus tremula), jelša lepkavá (Alnus glutinosa), rozličné druhy vŕb a iné, na najsuchších polohách sa sporadicky vyskytuje aj hrab. V krovinnom poschodí nájdeme ešte svíb krvavý (Swida sanguinea), zob vtáčí (Ligustrum vulgare), javor poľný (Acer campestre) a i.

Al - Lužné lesy podhorské a horské.

Spoločenstvá tejto jednotky sú akýmsi pokračovaním vŕbovo-topoľových lužných lesov na alúviách v úzkych údolných nivách na stredných a hôrnych tokoch riek, prevažne v extrémnejších klimatických podmienkach, najmä na strednom a severnom Slovensku. Ekologicky sa viažu na aluvia potokov podmáčaných prúdiacou podzemnou vodou alebo ovplyvňovaných častými povrchovými záplavami.

Pôdy v pahorkatinnomstupni sú viac hlinité, stredne ťažké, v horských údoliach piesočnaté, štrkovité až kamenisté. Kroviné vrbiny Salicion triandrae a Salicion elaeagni sú pionierskymi spoločenstvami na mladých riečnych naplaveninách lemujúcich brehy vodných tokov. Z drevín su zastúpené vŕba siva (Salix elaeagnos), vŕba purpurová (S. purpurea), vŕba krehká (S. fragilis), jelša sivá (Alnus incana), jelša lepkavá (A. glutinosa), jaseň štíhly (Fraxinus excelsior). Veľmi pestré je druhové zloženie bylín.

Najčastejšie su to hygrofilne a subhygrofilne rastliny záružlie močiarne (Caltha palustris), bodliak lopuchovitý (Carduus personata), pichliač potočný (Cirsium rivulare), devaťsil lekársky (Petasites hybridus), nezábudka močiarna (Myosotis scorpioides), iskerník plazivý (Ranunculus repens), prhľava dvojdomá (Urtica dioica) a i.

C - Dubovo-hrabové lesy karpatské

Mezofilne zmiešane listnaté lesy zo zväzu Carpinion betuli sú na území Slovenska najrozšírenejšou lesnou klimaticko-zonálnou formáciou v dubovom stupni. Pôvodne zaberali na Slovensku súvisle rozsiahle plochy, najmä v pahorkatinách a vrchovinách až do výšky priemerne 600 m n. m.

Vyskytujú sa prevažne na alkalických hlbokých pôdach na rôznorodom geologickom podloží. V stromovom poschodí sa vyskytujú hrab obyčajný (Carpinus betulus), dub zimný (Quercus petraea), javor poľný (Acer campestre), lipa malolistá (Tilia cordata), lipa veľkolistá (T. platyphyllos) a čerešňa vtáčia (Cerasus avium). Z krovín su to zemolez obyčajný (Lonicera xylosteum), svíb krvavý (Swida sanguinea), lieska obyčajná (Corylus avellana), zob vtáčí (Ligustrum vulgare), hloh obyčajný (Crataegus laevigata).

Bylinný podrast tvoria kopytník európsky (Asarum europaeum), lipkavec marinkový (Gálium odoratum), zubačka cibuľkonosná (Dentaria bulbifera), kostrava rôznolistá (Festuca heterophylla).

Ct - Zmiešané listnato-ihličnaté lesy v severných karpatských kotlinách

Floristicky sú tieto spoločenstvá pomerne jednotné, buk lesný (Fagus sylvatica) je v nich blízko svojho ekologického optima, jedľa biela (Abies alba) pri dostatku tepla a väčšej vlhkosti je jeho rovnocennou partnerkou. Na dolnej hranici výskytu jednotky býva zastúpený ešte aj dub zimný (Quercus petraea), zriedkavo hrab obyčajný (Carpinus betulus). Stálou prímesou je javor horsky (Acer pseudoplatanus), javor mliečny (A. platanoides), brest horsky (Ulmus glabra), jaseň štíhly (Fraxinus excelsior), lipa malolistá (Tilia cordata), zriedkavo aj smrek obyčajný (Picea abies). Z krovinatých drevín sa vyskytujú najmä baza čierna (Sambucus nigra), baza červená (Sambucus racemosa), bršlen európsky (Euonymus europaeus), zemolez obyčajný (Lonicera xylosteum) a egreš obyčajný (Grossularia uva-crispa). Z bylín sú zastúpené najmä lipkavec marinkový (Gálium odoratum), hluchavník žltý (Galeobdolon luteum), kyslička obyčajná (Oxalis acetosella), ostružina srstnatá (Rubus hirtus), veronika horská (Veronica montana), veternica hájna (Anemone nemorosa), ostružina malina (Rubus idaeus), čučoriedka (Vaccinium myrtillus), papraď samičia (Athyrium filix-femina) a i.

Fs - Bukové kvetnaté lesy podhorské

Mezotrofné lesné spoločenstvá s prevahou buka lesného (Fagus sylvatica) v nižších polohách, prevažne na nevápencovom podloží. V stromovom poschodí sú primiešané hrab obyčajný (Carpinus betulus), čerešňa vtáčia (Cerasus avium), lipa malolistá (Tilia cordata), smrek obyčajný (Picea abies), smrekovec opadavý (Larix decidua). Krovinný podrast vytvárajú druhy stromového poschodia v podobe mladých jedincov a pristupuje javor poľný (Acer campestre), lieska obyčajná (Corylus avellana) a vtáčí zob (Ligustrum vulgare). Bylinné poschodie vytvárajú druhy bažanka trváca (Mercurialis perennis), čarovník alpínsky (Circaea alpina), čistec lesný (Stachys sylvatica), na vlhkých miestach pristupuje devaťsil biely (Petasites albus). Z ďalších druhov sa tu nachádza fialka lesná (Viola reichenbachiana), hniezdovka hlístová (Neottia nidus – avis), hluchavník žltý (Galeobdolon luteum), hrachor jamy (Lathyrus vernus), hviezdica veľkokvetá (Stellaria holostea), hviezdnatec čemericový (Hacquetia epipactis), chochlačka dutá (Corydalis cava), chrastavec roľný (Knautia arvensis), jahoda obyčajná (Fragaria vesca), lipkavec marinkový (Galium odoratum) a i.

F - Bukové a jedľovo-bukové lesy

Mapová jednotka zahŕňa mezotrofné spoločenstvá s výraznou prevahou buka, rozšírené v nižších polohách prevažne s pôdami vlhkostne kolísavými. Prímesou buka lesného (Fagus sylvatica) bývajú javor horský (Acer pseudoplatanus), javor mliečny (A.platanoides), brest horský (Ulmus glabra), lipa malolistá (Tilia cordata) i smrek obyčajný (Picea abies). Krovinné poschodie nebýva nápadne vyvinuté, najčastejšie sa vyskytuje baza čierna (Sambucus nigra), bršlen európsky (Euonymus europaeus), zemolez obyčajný (Lonicera xylosteum). Základné floristické zloženie podhorských bučín nie je celkom jednotné vzhľadom na rozdielnosť geologického podložia a rozpad jednotlivých hornín, chemizmus, a tým aj štruktúru pôd.

Vo všetkých spoločenstvách je pravidelne prítomný lipkavec marinkový (Galium odoratum), ďalej sa vyskytujú hluchavník žltý (Galeobdolon luteum), veronika horská (Veronica montana), veternica hájna (Anemone nemorosa), vranovec štvorlistý (Paris quadrifolia), fialka lesná (Viola reichenbachiana), hluchavník žltý (Galeobdolon luteum), ľalia zlatohlávka (Lilium martagon), marinka voňavá (Galium odoratum), papradka samičia (Athyrium filix-femina), papraď samčia (Dryopteris filix-mas), samorastlik klasnatý (Actaea spicata), srnovník purpurový (Prenanthes purpurea), vranovec štvorlistý (Paris quadrifolia), zubačka cibuľkonosná (Dentaria bulbifera), zubačka žliazkatá (Dentaria glandulosa) a i.

Fc - Bukové lesy na vápencových a dolomitových podložiach

Mapová jednotka zahŕňa bukové a zmiešané lesy na rendzinach rozšírené na strmých skalných vápencových a dolomitových svahoch v podhorskom a nižšom horskom stupni. V nižších polohách sa vyskytujú viac na chladnejších expozíciách. Zloženie fytocenóz vápencových bučín je veľmi nevyrovnané. Z drevín dominuje buk, skeletnaté a sutinové pôdy podporujú existenciu sutinových drevín: lipy (Tilia), javor (Acer), čerešňa vtáčia (Cerasus avium), jarabina (Sorbus), z krovín muchovník (Amelanchier), mahalebka (Cerasus mahaleb), nezriedkavý je aj výskyt tisu obyčajného (Taxus baccata). Z bylín nachádzame napr. čučoriedku (Vaccinium myrtillus), brusnicu obyčajnú (V. vitis-idaea), konvalinku voňavú (Convallaria majalis), ľaliu zlatohlávku (Lilium martagon), kúštik rožkatý (Epipactis muelleri), lazerník širokolistý (Laserpitium latifolium), orlíček obyčajný (Aquilegia vulgaris), ostrevka vápnomilná (Sesleria albicans), ostrica biela (Carex alba), plamienok alpínsky (Clematis alpina), prilbovka biela (Cephalanthera damasonium), prilbovka červená (Cephalanthera rubra), smlz pestrý (Calamagrostis varia), valeriána trojená (Valeriana tripteris), zvonovec ľaliolistý (Adenophora liliifolia) a i.

Qa - Nátržníkové dubové lesy

Edaficky podmienené, flóristicky bohaté dubiny, ktoré su charakteristické pre vnútrokarpatské kotliny, kde

sa viažu na plošiny a mierne svahy pahorkatín s príkrovmi sprašových hlín a ílov a s ilimerizovanými hnedozemnými pôdami až pseudoglejmi. Okrem dubov je často aj prítomná borovica a breza. V podraste sa vyskytujú prvky dubín, mezofilné, ale tiež acidofilné druhy. Typické su druhy ťažkých pôd znášajúce zamokrenie a vysušenie. Z drevín sa okrem dominantných dubov, duba letného (Quercus robur), duba zimného (Q. petraea) a krušiny jelšovej (Frangula alnus) môžu vyskytnúť lieska obyčajná (Corylus avellana) a borovica lesná (Pinus sylvestris). V nedrevnatej synuzii podrastu sú zastúpené betonika lekárska (Betonica officinalis), ostrica horská (Carex montana), klinček pyšný (Dianthus superbus), lipkavec severný (Galium boreale), hrachor čierny (Lathyrus niger), chlpaňa hájna (Luzula luzuloides), mednička zafarbená (Melica picta), bezkolenec trsťovnikovitý (Molinia arundinacea), nátržník biely (Potentilla alba), pľúcnik Murinov (Pulmonaria murini), iskerník mnohokvetý (Ranunculus polyanthemos), kosienka farbiarska (Serratula tinctoria), vika kašubska (Vicia cassubica) a i.

Obrázok 12 *Potenciálna prirodzená vegetácia okresu Prešov*

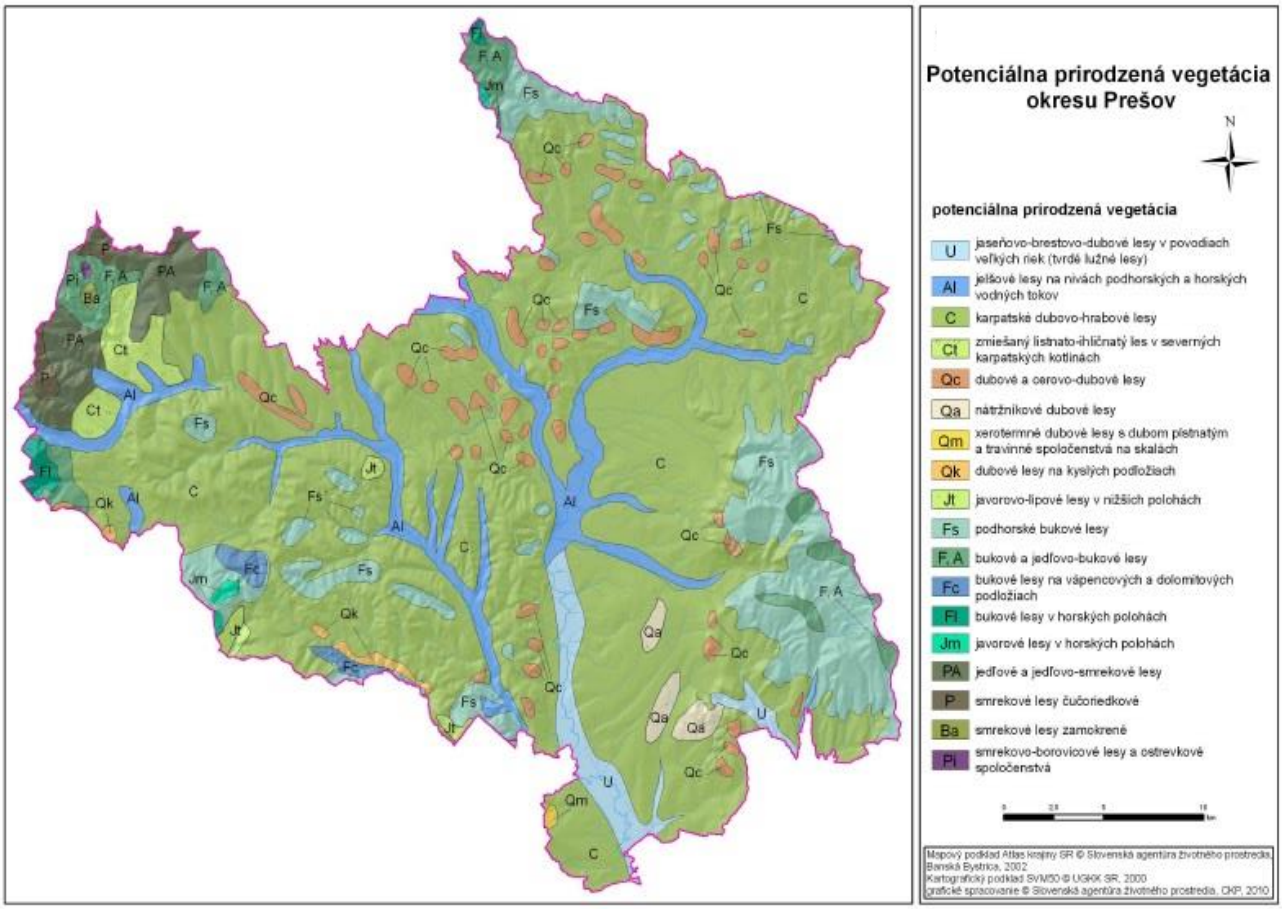

/Zdroj: RÚSES okresu Prešov, 2010/

Živočíšstvo

Územie okresu Prešov, mimo vymedzených vyhlásených chránených území v rôznej kategórii a stupni ochrany, spadá do priestoru, v ktorom sa stretajú svojimi okrajmi tri rôzne zoogeografické provicie. Ostré rozhranie tvorí hranica, ktorá prebieha v smere sever – juh mestom Prešov medzi provinciou Západných a Východných Karpát. Západné Karpaty dosahujú po Prešov na severozápade vonkajším obvodom, zastúpeným beskydským okrskom a východným podokrskom. Juhozápadne od Prešova ich zastupuje zasa vnútorný obvod s centrálnym okrskom zastúpeným rudohorským podokrskom. Východné Karpaty severovýchodne od Prešova reprezentuje prechodný obvod s nízkobeskydským okrskom a juhovýchodne slanský okrsok. K druhovým špecifikám, ktorých pôvod je vo Východných Karpatoch a rozšírili sa z tohto prostredia cez územie okresu západným smerom, patrí sova dlhochvostá (Strix uralensis), krkavec čierny (Corvus corax). Údolím rieky Torysa po Prešov z juhu vystupuje aj Panónska provincia vo vnútrokarpatskej zníženine, reprezentovanej Košickým okrskom v juhoslovenskom obvode. K druhom, ktoré vystupujú z tohto prostredia a šíria sa cez územie okresu severným smerom, patrí napr. hrdlička záhradná (Streptopelia decaocto), ďateľ hnedkavý (Denrocopos syriacus), ryšavka tmavopása (Apodemus agrarius).

Druhovú skladbu živočíchov územia okresu Prešov môžeme všeobecne označiť ako ubiquistickú s typickými zástupcami ako je myš domová (mus musculus), potkan obyčajný (Rattus norvegicus), hranostaj obyčajný (Mustella erminea) a ako spoločenstvo listnatých lesov so zástupcami druhov tchor obyčajný (Putorius putorius), raniak hrdzavý (Nyctalus noctula) a plch obyčajný (Glis glis). Z hľadiska chrobákov je pre okres charakteristické spoločenstvo listnatých lesov, v ktorom vystupujú ako charakteristickí zástupcovia bystruška kožovitá (Carabus coriaceus), svietivka svätojánska (Lampyrus noctiluca), pestroš mravcový (Thanasimus formicarius), svižník hôrny (Cicindela silvicola), krasoň lesklý (Anthaxia nitidula), drvinár hnedý (Hylecoetus demestoides) a i.

V pomerne jednotvárnom prostredí krajiny vystupuje priestor južných, presvetlených, teplých svahov vulkanitov a priľahlých tvrdošov bradlového pásma a flyša severne od mesta ako izolovaný ostrov suchomilných a teplomilných spoločenstiev hmyzu. Svedčí o tom výskyt a prítomnosť druhov ako je koník modrokrídly (Oedipoda coerulescens), svrček poľný (Gryllus campestris), bzdocha pásavá (Graphosoma lineatum), chrústik letný (Amphimallon solstitialis), drevár fialový (Xylocopa violacea), lišaj mliečnikový (Celerio euphorbiae), modlivka zelená (Manthis religiosa) a i.

Zoocenózy v krajine

Diverzita druhov živočíchov územia všeobecne a teda aj územia okresu Prešov závisí predovšetkým od typov prostredia, v ktorých sa vyvíjajú charakteristické spoločenstvá živočíchov v úzkej interakcii s ostatnými prírodnými zložkami - horninovým prostredím, pôdou, vodou, klímou a rastlinstvom (v prípade živočíchov tolerujúcich urbánne či antropogénne prostredie aj v interakcii s urbánnymi a technickými prvkami).

Na území okresu Prešov registrujeme viacero typov zoocenóz, príznačných pre jeho prírodné prostredie: Zoocenózy listnatých lesov, zoocenózy ihličnatých a zmiešaných lesov, zoocenózy lúk a pasienkov, zoocenózy lúk a pasienkov sukcesne zarastajúce, zoocenózy prameníst a vlhkých stanovíšť, vrátane vlhkých lúk (s výnimkou vodných tokov a vodných nádrží), zoocenózy vodných tokov a vodných nádrží, zoocenózy s ornou pôdou, zoocenózy zastavaného územia, záhrad a inej sídelnej zelene.

Každá z uvedených zoocenóz je z hľadiska kvalitatívneho i kvantitatívneho výskytu živočíšnych druhov významná, pričom susediace zoocenózy alebo prelínajúce sa sú vzájomne ovplyvňované a obohacované.

Všetky vymenované typy zoocenóz sú v rôznej miere poznačené antropogénnou činnosťou (v minulosti i v súčasnosti), v podstate neexistuje typ zoocenózy s absolútnou absenciou vplyvu činnosti človeka.

Najmenej sú antropogénnou činnosťou poznačené prírodné lesy, zoocenózy prameníst, vodných tokov (mimo zastavaných území) a niektorých sezónnych zamokrených depresií a deluviálnych svahov.

Lúky a pasienky bez nelesnej drevinovej vegetácie alebo aj sukcesne zarastené (alebo zarastajúce) vznikli historicky odlesnením, teda antropogénnym pôsobením, významná časť z nich je polopríродného až prírodného charakteru a predstavuje v podstate náhradné biotopy za pôvodné lesné.

Najviac antropogénnou činnosťou sú poznačené ostatné zoocenózy – zoocenózy záhrad, zastavaného územia (urbánne) a zoocenózy s ornou pôdou.

Zoocenózy listnatých, ihličnatých a zmiešaných lesov

Ucelené lesné spoločenstvá vystupujú na území okresu v geografických celkoch Slanské vrchy, Volovské vrchy a Branisko. Ostatné lesné komplexy (Čergova, Beskydského predhoria, Spišsko-šarišského medzihoria, Bachurne, Šarišskej vrchoviny, Čiernej hory a Košickej kotliny) vystupujú mozaikovito rozptýlené v severovýchodnej, severnej, centrálnej a juhozápadnej časti územia. Svojou plošnou rozlohou dosahujú väčšie i menšie celky vystupujúce na vrcholkoch pahorkatiny a vrchoviny, prípadne schádzajú málo dostupnými údoliami potokov. Svojou prítomnosťou významne vylepšujú ekologický koeficient krajiny a ekologicky stabilizujú územie. Sú významnou zložkou štruktúry krajiny, ktorá priaznivo ovplyvňuje

druhovú diverzitu živočíšnych spoločenstiev. Pre výskyt druhov vytvárajú areálové hniezdne možnosti (myšiak lesný – Buteo buteo, jastrab lesný - Accipiter gentilis, orol krikľavý – Aquila pomarina, orol skalný – Aquila chrysaetos, sokol lastovičiar – Falco subbuteo, včelár lesný - Pernis apivorus, bocian čierny – Ciconia nigra, sova dlhochvostá – Strix uralensis a i.), úkrytové možnosti (srnec hôrny – Capreolus capreolus, jeleň európsky – Cervus elaphus, sviňa divá – Sus scrofa, vlk dravý – Canis lupus, rys ostrovid – Lynx lynx, medveď hnedý – Ursus arctos a i.) a potravné možnosti pre celý diapazón živočíchov využívajúcich lesné prostredie. Niektoré druhy živočíchov sú troficky viazané výlučne na ihličnaté, prípadne zmiešané lesy s vysokým podielom ihličnatých stromov (predovšetkým smreka) Braniska, Čiernej hory a Bachurne (orešnica perlovaná – Nucifraga caryocatactes, sýkorka chochlatá – Parus cristatus, králik zlatohlavý – Regulus regulus a i.). To všeobecne platí aj pre bezstavovce, u ktorých výskyt druhov nie je (aj v rámci Slovenska) kontinuálne preskúmaný.

Všeobecne zoocenózy lesov disponujú bohatou škálou druhov vtákov – z významnejších uvádzame okrem dravcov uvedených vyššie bociana čierneho (Ciconia nigra), jariabka hôrneho (Bonasia bonasia), sluku lesnú (Scolopax rusticola), výra skalného (Bubo bubo), sovu lesnú (Strix aluco), sovu dlhochvostú (Strix uralensis), lelka lesného (Caprimulgus europaeus), viaceré druhy ďatľovcov a mnohé druhy spevavcov.

Z hmyzožravcov tu žije piskor lesný (Sorex araneus), vo vlhkejších lesných biotopoch piskor malý (Sorex minutus), pri lesných bystrinách dulovnica väčšia (Neomys fodiens). Z hlodavcov v lesných spoločenstvách žijú veverica stromová (Sciurus vulgaris), plch sivý (Glis glis), predovšetkým na rúbaniskách plch lieskový (Muscardinus avellanarius), v lesoch s dostatkom podrastu plch lesný (Dryomys nitedula). Významné sú viaceré druhy netopierov viažucich sa na lesné prostredie.

Zoocenózy lúk a pasienkov bez sukcesie drevín, resp. sukcesne zarastajúce

Spoločenstvo živočíchov predstavuje celá škála druhov, ktorá je výsledkom zmiešania viacerých typov spoločenstiev.

Z obojživelníkov sa v zoocenózach lúk a pasienkov vyskytujú ropucha bradavičnatá (Bufo bufo), kunka žltobruchá (Bombina variegata) – na dlhšie zamokrených poľných cestách a v zamokrených plytkých depresiách.

Plazy v prostredí lúk a pasienkov reprezentujú užovka obojková (Natrix natrix), užovka hladká (Coronella austriaca), vretenica severná (Vipera berus) - útržkovito, jašterica bystrá (Lacerta agilis) a slepúch lámavý (Anguis fragilis).

Oproti lesnému prostrediu je čo do diverzity druhov avifauna početne menej zastúpená. Podstatná je ale skutočnosť, že viaceré druhy hniezdiace a žijúce v lesných komplexoch disponujú trofickou základňou,

situovanou aj v trvalých trávnych porastoch; týka sa to predovšetkým väčšiny druhov dravcov a krkavca čierneho (Corvus corax) a druhov, komunikujúcich medzi lesom, ostrovčekmi remízok a lesíkov a sukcesne porastenými lúkami - drozda čvíkotavého (Turdus pilaris), drozda plavého (Turdus philomelos).

Z druhov vtákov jednoznačne patriacich do zoocenózy lúk a pasienkov na území okresu Prešov žijú myšiak severský (Buteo lagopus) – len v zimných mesiacoch, migrant zo severu, jarabica poľná (Perdix perdix), prepelica poľná (Coturnix coturnix), chriašteľ poľný (Crex crex) – v prostredí sviežich a vlhkých lúk, škovránok poľný (Alauda arvensis) a strnádka lúčna (Miliaria calandra).

Nivné lúky v okolí vodných tokov Torysa a Sekčov využíva počas migrácie, ale aj na hniezdenie cíbik chochlatý (Vanellus vanellus).

Z cicavcov viac menej „holé“ biotopy lúk a pasienkov využívajú krt obyčajný (Talpa europaea), líška hrdzavá – vyhrabáva si tu aj nory. Horskými a podhorskými lúkami sa pohybuje vlk dravý (Canis lupus) v rámci kontroly svojho teritória (predovšetkým v zime vo svorkách). Hmyz tu loví viacero druhov netopierov prilietajúcich z lesa alebo zo stavaného územia. Z myšovitých sa v tomto biotope na vlhkých lúkach vyskytuje ryšavka tmavopása (Apodemus agrarius), z hrabošovitých hraboš poľný (Microtus arvalis).

V ostatných desaťročiach vzácnym druhom nielen pre územie okresu, ale pre celé Slovensko sa stal dovtedy bežný teplomilný obyvateľ suchších lúk, planín a strání – syseľ pasienkový (Spermophyllus citellus). Na území okresu Prešov sa nachádza už len niekoľko lokalít, v ktorých prežívajú zostatky pôvodných populácií (v katastroch obcí Ovčie, Hrabkov). Vinou absencie tradičných foriem obhospodarovania lúk a pasienkov alebo ich rozoraním zaniklo množstvo pôvodných lokalít.

Ako potravinová základňa sú lúky a pasienky využívané hlavne lesnou zverou - srncom hôrnym (Capreolus capreolus), jeleňom karpatským (Cervus elaphus), zajacom poľným (Lepus europaeus) a diviakom lesným (Sus scropha), ktoré patria k navštevujúcim druhom tohto typu prostredia, aj keď úkrytovými miestami disponujú v lesných zoocenózach, resp. v okrajových ekotónových zónach.

Osobitný význam majú lúčne predely medzi lesnými celkami v pahorkatinovej a vrchovinovej časti územia v juhozápadnej časti okresu. Zachovalé lúčne spoločenstvá a trvalé trávnaté porasty tu nadobúdajú charakter horských lúk s výskytom typických druhov polí ako je škovránok poľný (Alauda arvensis), prepelica poľná (Coturnix coturnix), ale aj živočíšnych druhov vyšších polôh ako je chrapkáč poľný (Crex crex), ľabtuška lesná (Anthus trivialis).

V zoocenózach lúk a pasienkov so sukcesiou drevín je diverzita evertebrat – hmyzu viac menej totožná s predchádzajúcou zoocenózou, jej kvalitatívne, prípadne kvantitatívne zmeny závisia od intenzity sukcesného procesu. Podobne to platí aj pre diverzitu druhov a početnosť v rámci druhu u obojživelníkov

a predovšetkým plazov a drobných zemných cicavcov, v súvislosti s postupujúcou sukcesiou sa oba ukazovatele zvyšujú, limitujúcim faktorom je prechod sukcesie do iniciačného štádia lesa. V podstate je skladba druhov bezstavovcov, obojživelníkov, plazov a drobných zemných cicavcov v tejto zoocenóze takmer totožná so skladbou druhov v zoocenóze lúk a pasienkov s absenciou sukcesie drevín.

V zoocenóze lúk a pasienkov so sukcesiou drevín (najmä krovín) okrem druhov vtákov uvedených v predchádzajúcej zoocenóze pristupujú ďalšie druhy, využívajúce nielen prostredie trvalých trávnych porastov, ale aj sukcesiu krovín a stromov na neudržiavaných trávnych porastoch: z veľkej škály druhov uvádzame len niektoré: viaceré druhy pŕhľaviarov, peníc, sýkoriek, vrabcov, stehlíkov, strnádiek a strakoša červenochrbtého (Lanius collurio).

Z cicavcov sukcesiou porastené biotopy využívajú jež východoeurópsky (Erinaceus concolor), bielozúbka bielobruchá (Crocidura leucodon), bielozúbka krpatá (Crocidura suaveolens), lasica obyčajná (Mustela nivalis).

Zoocenózy prameníst a vlhkých stanovíšť, vrátane vlhkých lúk (s výnimkou vodných tokov a vodných nádrží)

Sú špecifickým stanovišťom, ktorý obohacuje krajinu a jej diverzitu o ďalšie živočíšne druhy. Žijú tu špecifické druhy mäkkýšov, pavúkov, mnohonôžok, motýľov , dvojkrídlovcov a chrobákov.

V terénnych zníženinách relatívne plytko naplnených vodou žijú a rozmnožujú sa kunka žltobruchá (Bombina variegata), ropucha bradavičnatá (Bufo bufo), menej ropucha zelená (Bufo viridis) a rosnička zelená (Hyla arborea). Menej často sa v takýchto malých depresiách objavujú mloky, napr. mlok hrebenatý (Triturus cristatus). Na vlhkých lúkach i mokrých zníženinách bežne žije užovka obojková (Natrix natrix), objavuje sa aj vretenica severná (Vipera berus). Zvýšený výskyt obojživelníkov i plazov priťahuje bociana bieleho (Ciconia ciconia), zriedkavejšie i bociana čierneho (Ciconia nigra). Svieže a vlhké lúky, mozaikovito zamokrené sú prirodzeným biotopom chriašteľa poľného (Crex crex), cíbika chochlatého (Vanellus vanellus) a pŕhľaviara červenkastého (Saxicola rubetra).

V takýchto zoocenózach žijú niektoré, predovšetkým drobné zemné cicavce - zriedkavo piskor malý (Sorex minutus), častejšie sa vyskytujú ryšavka tmavopása (Apodemus agrarius), hraboš močiarny (Microtus agrestis) a hrabáč podzemný (Pitimys subterraneus).

Zoocenózy vodných tokov a vodných nádrží

V krajinno-ekologickej štruktúre okresu vystupujú ako významný prvok tečúce vody. Rieky Torysa, Sekčov, Delňa, Svinka a Sopotnica sú kostrou hydrickej ekologickej štruktúry územia.

Analýza vodnej zložky s dôrazom na lotické biotopy a v rámci nich na ichtyofaunu a čiastočné hodnotenie lentických biotopov a ostatných zložiek akvatickej fauny (Koščo, Druga, 2010) je spracovaná podrobnejšie v samostatnej prílohe tohto dokumentu. Obsahuje hydrologickú charakteristiku, metodiku a výsledky pozorovaní pre ichtyofaunu, makrozoobentos. Súčasťou je aj hodnotenie povodia Torysy z hľadiska významu pre Územný systém ekologickej stability okresu Prešov.

Na Torysu (a podobnými podmienkami čiastočne aj na niektoré jej rozhodujúce prítoky) najmä na už zriedkavé ešte kvalitné lužné lesy s mozaikov zamokrených terénnych zníženín, prirodzených kanálov, pribrežných depresií so stojatou alebo veľmi pomaly odtekajúcou vodou, izolovaných od tečúcich vôd rieky štrkovými akumuláciami sa viaže pobyt a reprodukcia predovšetkým skokana hnedého (Rana temporaria), skokana rapotavého (Rana ridibunda), ropuchy bradavičnatej (Bufo bufo), ropuchy zelenej (Bufo viridis) a rosničky zelenej (Hyla arborea). Na bystriny v lesoch výskyt salamandry škvrnitej (Salamandra salamandra).

Z plazov v týchto podmienkach troficky naviazané predovšetkým na túto batrachofaunu žijú užovka obojková (Natrix natrix), menej užovka fŕkaná (Natrix tesselata), v sprievodnej vegetácii Torysy a Sekčova bola zistená aj užovka stromová (Zamenys longissima).

Lužné lesy Torysy a jej prítokov (t.z. drevinová vegetácia v sprievodnej vegetácii toku) a priamo aj vodné toky sú po klasických lesoch druhým prostredím najbohatším na avifaunu.

Neregulované korytá tokov a neupravené úseky vytvárajú nenahraditeľné biotopy vyšších stien riečnych korýt a náplavových štrkových lavíc s možnosťami na hniezdenie pre rybárika riečneho (Alcedo atthis), včelárika zlatého (Merops apiaster), brehuľu riečnu (Riparia riparia), kulíka riečneho (Charadrius dubius).

Na území okresu v riečnych ekosystémoch žije kačica divá (Anas platyrhynchos), volavka popolavá (Ardea cinerea), kulík riečny (Charadrius dubius) – na štrkových akumuláciách hniezdi, trasochvost biely (Motacilla alba) a trasochvost horský (Motacilla cinerea) - hniezdia v dutinách stromov v blízkosti vodných tokov. V brehoch potokov v horách a podhorí, ale i v telesách mostov hniezdi vodnár potočný (Cinclus cinclus). V ostatných rokoch v súvislosti s prirodzeným rozširovaním sa kormorána veľkého (Phalacrocorax carbo) pozdĺž riek severným smerom sa na stromoch v pobrežných porastoch Torysy a Sekčova sporadicky tento druh zdržiava a je len otázkou krátkej doby, kedy bude v zimnom období vytvárať v brehových porastoch Torysy i príležitostné nocoviská s desiatkami jedincov v skupine. Zatiaľ kormorán veľký na území okresu Prešov nehniezdi.

Významným fenoménom je prítomnosť niektorých vodných a pri vode žijúcich živočíchov – vydry riečnej (Lutra lutra), dulovnice väčšej (Neomys fodiens), dulovnice menšej (Neomys anomalus), hryzca vodného

(Arvicola terrestris), nepôvodnej ondatry pižmovej (Ondatra zibethicus).

Z hľadiska budúcnosti sa veľmi skoro očakáva prenikanie populácií bobra vodného (Castor fiber), ktorý v ostatných rokoch úspešne osídľuje geograficky blízke toky a vodné nádrže, predovšetkým Topľu, Ondavu, Laborec, Poprad, Dunajec a ich prítoky.

V popisovanom priestore chýbajú stabilizačné väčšie vodné plochy s otvorenou vodnou hladinou a s dostatočným plošným zastúpením makrofytov. Z toho dôvodu početnosť typických zástupcov vodných a pri vode žijúcich druhov fauny je v území celoročne malý a iba v čase migrácie prechodne narastie. Z ekostabilizačných vodných priestorov má významné postavenie úsek riečneho koryta Torysy pod Šarišským hradom. Napriek legálnej ťažbe štrku a piesku v riečišti dochádza v území aj k nelegálnej ťažbe, čo ovplyvňuje výskyt a reprodukciu živočíšnych druhov viazaných na tento typ biotopu.

Vodné plochy typu vodných nádrží či rybníkov v okrese až na zopár výnimiek chýbajú. Pokiaľ neberieme do úvahy vodnú nádrž v rekreačnej oblasti Sigord na Delni, stojatými vodami s otvorenou vodnou hladinou a polopriroderným prostredím je rybník pri Fričovciach a štrkové jamy – nedobudované rybníky na ľavostrannej nive Torysy pri Veľkom Šariši. Oba tieto pôvodne technické prvky v krajine viažu potencionálne na seba predovšetkým batrachofaunu a vodné a pri vode žijúce vtáctvo.

Zoocenózy s ornou pôdou

Sú to otvorené priestory situované spravidla najbližšie k zastavaným územiam obcí (s ekonomicky podloženou dostupnosťou), v ktorých prevláda orná pôda. Keďže priestory patria medzi najviac atakované ľudskou činnosťou, predstavujú tieto zoocenózy pobytové, potravné a niekedy i reprodukčné možnosti pre úzky diapazón druhov, tolerujúcich takéto podmienky.

V krajine okresu Prešov sú to veľkoblokové i maloblokové plochy ornej pôdy, prípadne i mozaiky políčok umiestnené v blízkosti sídiel, v ktorých sa sekundárne prírodné podmienky často (každoročne) menia v závislosti od spôsobu hospodárenia a výberu plodín (kultúr).

Z významných druhov živočíchov sa v takejto zoocenóze viac menej stabilne vyskytujú obojživelníky, plazy, vtáky a cicavce: z obojživelníkov predovšetkým ropucha bradavičnatá (Bufo bufo), ropucha zelená (Bufo viridis), kunka žltobruchá (Bombina variegata) – v sezónnych mlákach poľných ciest a terénnych depresií, z plazov užovka obojková (Natrix natrix). Vtáctvo je paradoxne reprezentované prítomnosťou viacerých druhov európskeho alebo národného významu – prepelicou poľnou (Coturnix coturnix), viacej jarabicou poľnou (Perdix perdix), bažantom poľovným (Phasianus colchicus), prhľaviarom čiernohlavým (Saxicola torquata), strnádkou lúčnou (Miliaria calandra), strnádkou žtou (Emberiza citrinella), pipíškou chochlatou (Galerida cristata) ale i cíbikom chochlatým (Vanellus vanellus), ktorý zahniezdi aj v poľných kultúrach.

Cicavce reprezentuje napríklad zajac poľný (Lepus europaeus), hranostaj čiernochvostý (Mustela erminea), piskor malý (Sorex minutus) a bežné druhy hlodavcov – škodcov poľnohospodárskych kultúr.

Zoocenózy zastavaného územia, záhrad a inej sídelnej zelene

Zastavané územia obcí na jednej strane a záhrady na druhej sa môžu samozrejme posudzovať aj oddelene, no v podmienkach predovšetkým vidieka a jeho koloritu sa prelínajú až tak, že záhrady sú súčasťou zastavaného územia, podobne v niektorých obciach aj historické parky komponované pri historických objektoch (kaštiele). K zachovaniu vyššej druhovej pestrosti územia významnou mierou prispieva členitosť a neupravenosť priestoru v bezprostrednom okolí ľudských sídiel a stavieb. Rôznorodý materiál uložený vo dvoroch domov, ako aj dožívajúce hospodárske stavby vytvárajú priestor pre existenciu a reprodukciu pre niektoré druhy ešte existujúcich populácií živočíchov intravilánu, napr. tchora obyčajného (Putorius putorius), potkana hnedého (Rattus norvegicus), myši domovej (Mus musculus), ale i kuny skalnej (Martes foina).

Povahu stavieb využíva na pobyt a reprodukciu i viacero druhov vtákov. Bežnými obyvateľmi sídiel na vidieku je belorítka domová (Delichon urbica), lastovička domová (Hirundo rustica), vrabec domový (Passer domesticus), žltochvost domový (Phoenicurus ochruros), kuvik plačlivý (Athene noctua), plamienka driemavá (Tyto alba), v ostatných rokoch menej už pipíška chochlatá (Galerida cristata).

Špecificky povaly niektorých klasických stavieb – kostolov, hospodárskych budov i niektorých domov, obývajú netopiere (často v kolóniách), napríklad podkovár malý (Rhinolophus hipposideros), netopier obyčajný (Myotis myotis), večernica malá (Pipistrellus pipistrellus).

Výrazným prostredím pre niektoré druhy avifauny a chiropterofauny sú mestské sídliská s bytovými domami (činžiakmi) v Prešove a solitéry bytových domov v niektorých ďalších sídlach; tie poskytujú vďaka svojej morfológii vynikajúce úkrytové a reprodukčné možnosti pre dážďovníka tmavého (Apus apus), belorítku domovú (Delichon urbica) a sokola myšiara (Falco tinnunculus), tiež pre večernicu malú (Pipistrellus pipistrellus) a raniaka hrdzavého (Nyctalus noctula). V ostatných rokoch však ich počty na sídliskách povážlivo klesajú v súvislosti so zatepľovaním budov (dážďovníky, netopiere) a výmenou drevených rámov okien za plastové (belorítky).

Záhrady v pôvodnom zmysle slova a verejná zeleň vyskytujúca sa takmer výlučne v intravilánoch obcí výraznou mierou ubudli z krajinného prostredia dožitím statných drevín, chorobami (pagaštan, brest), resp. pod tlakom urbanistickej prestavby ľudských sídiel. Jej náhrada nie je primeraná úbytku a rovnako aj druhová skladba drevín náhradnej výsadby nezodpovedá potenciálnej vegetácii a jej pôvodnej štruktúre,

drevinám domácej (miestnej) proveniencie. V súčasnosti preferovaná drevitá vegetácia ako verejná zeleň je nepôvodná (tuja, sumach, ihličnaté dreviny a i.) a aj vekovou skladbou nevytvára dominantnú kulisu, resp. monumentálnu oporu v ekologickej kostre a v štruktúre prostredia. V záhradách takmer úplne absentujú vekovo staré ovocné dreviny vhodné pre dutinové hniezdiče (orechy, hrušky, jablone).

Zeleň cintorínov má svoje osobitné postavenie aj vo vzťahu k uzavretosti prostredia. Toto prostredie je často miniareálom s početným výskytom živočíšnych druhov a vhodnými živnými rastlinami na reprodukciu bezstavovcov, ako aj ostatných druhov (myšiarka ušatá – Asio otus, hrdlička záhradná – Streptopelia decaocto, drozd plavý – Turdus philometos, slávik krovinový – Luscinia megarhynchos a i.). Toto špecifikum vyplýva aj zo sezónnosti využitia tohto prostredia a zo zachovania nenarušenosti v čase reprodukcie.

Osobitné postavenie v rámci niektorých zastavaných území obcí (Demjata, Fintice, Fričovce, Hermanovce, Ličartovce, Ľubovec - Ruské Pekľany, Petrovany, Prešov – Nižná Šebastová, Šarišské Bohdanovce a Župčany) majú tiež historické parky, komponované v minulosti pri teraz už historických objektoch pamiatkového charakteru. Druhová skladba, vek drevín a relatívne malá vzdialenosť parkov od lesov, prípadne od kvalitných lužných lesov sprevádzajúcich vodný tok, umožnili osídlenie týchto parkov predovšetkým druhmi avifauny, viažucimi sa v prirodzených podmienkach na lesné biotopy (najčastejšie sa jedná o sokola myšiara – Falco tinnunculus, hrdličky – Streptopelia turtur a S.decaocto, sovu lesnú – Strix aluco, myšiarku ušatú – Asio otus, krutihlava hnedého – Jynx torquilla, ďatľa veľkého – Dendrocopos major, ďatľa hnedkavého – D.syriacus, viaceré druhy lesných spevavcov).

Informácia vo vzťahu k environmentálne obzvlášť dôležitým oblastiam, akými sú navrhované chránené vtáčie *územia*, územia európskeho významu, súvislá európska sústava chránených území (Natura 2000), chránené vodohospodárske oblasti a pod.

NATURA 2000 - je názov sústavy chránených území členských štátov Európskej únie (EÚ), ktorej cieľom je zachovať prírodné dedičstvo významné pre EÚ ako celok a nielen pre príslušný členský štát.

Slovensko patrí svojimi prírodnými hodnotami k najbohatším krajinám EÚ. Vysokú rozmanitosť všetkých foriem života podmieňuje jeho poloha medzi Karpatmi a Panónskou nížinou, zložitá geologická stavba, veľká rôznorodosť geomorfologických, pôdnych, klimatických a hydrologických pomerov. K vysokej hodnote územia Slovenska z hľadiska biodiverzity prispieva najmä rozmanitosť biotopov (životné prostredie organizmov). Do siete NATURA 2000 patria dva druhy chránených území, a to územia európskeho významu a chránené vtáčie územia.

Územia európskeho významu

Sú vyhlasované podľa smernice o biotopoch (smernica Rady č.92/43/EHS o ochrane biotopov, voľne žijúcich živočíchov a voľne rastúcich rastlín). Za územie európskeho významu možno vyhlásiť územie, na ktorom sa nachádzajú biotopy európskeho významu, alebo druhy európskeho významu. Národný zoznam území európskeho významu schválila vláda SR uznesením č. 239 zo 17. marca 2004. Územie európskeho významu po prijatí Európskou komisiou vyhlási orgán ochrany prírody za chránené územie alebo zónu chráneného územia podľa zákona o ochrane prírody chránený areál, prírodnú rezerváciu alebo chránený krajinný prvok. To znamená, že v územiach európskeho významu (ÚEV) orgán ochrany prírody stanovuje osobitné stupne ochrany (druhý až piaty) v zmysle zákona o ochrane prírody.

V okrese Prešov sa nachádza 9 ÚEV, ktoré boli prijaté rozhodnutím Komisie 2008/218/ES z 25. januára 2008, ktorým sa podľa smernice Rady 92/43/EHS prijíma prvý aktualizovaný zoznam lokalít európskeho významu v alpskom biogeografickom regióne. Týchto 9 ÚEV zaberá plochu 2391,65 ha okresu, čo predstavuje 3,14 % z celkovej výmery. 8 ÚEV patrí celou svojou plochou do okresu, len ÚEV Čergov, ktoré je zároveň plošne najväčšie (6063,43 ha), zasahuje svojou majoritnou časťou (5111,29 ha) aj do iných okresov.

Na základe záverov biogeografikého seminára požiadala Európska komisia Slovenskú republiku o doplnenie národného zoznamu ÚEV o ďalšie územia pre nedostatočne pokryté biotopy a druhy rastlín a živočíchov európskeho významu v alpskom biogeografickom regióne. Na základe tejto požiadavky sú v okrese Prešov navrhované na doplnenie národného zoznamu tri územia.

Tabuľka 4 *Územia európskeho významu v okrese Prešov*

Kód územia	Názov územia	Katastrálne územie	Rozloha (ha)	Správca územia
ÚEV prijaté				
SKUEV0207	**Kamenná baba**	Lačnov, Lipovce	339,98	RCOP v Prešove
SKUEV0320	**Šindliar**	Šindliar	7,69	RCOP v Prešove
SKUEV0321	**Salvátorské lúky**	Lipovce, Šindliar	2,68	RCOP v Prešove
SKUEV0322	**Fintické svahy**	Fintice, Kapušany, Terňa, Tulčík, Veľký Šariš, Záhradné, Fulianka	753,9	RCOP v Prešove
SKUEV0323	**Demjatské kopce**	Demjata, Veľký Slivník	8,68	RCOP v Prešove
SKUEV0330	**Dunitová skalka**	Sedlice	1,48	RCOP v Prešove
SKUEV0332	**Čergov***	Babin Potok, Bodovce, Fričkovce, Hertník, Hradisko pri Terni, Kríže, Livov, Olejníkov, Ratvaj, Šiba	6063,43 (952,14)	RCOP v Prešove
SKUEV0390	**Pusté pole**	Zlatá Baňa	90,35	RCOP v Prešove
SKUEV0401	**Dubnícke bane**	Červenica, Zlatá Baňa	234,75	RCOP v Prešove
ÚEV navrhované				

SKUEV0746	**Hornádske lúky***	Sedlice, Malá Lodina	66,49 (1,17)	RCOP v Prešove
SKUEV0747	**Gýmešský jarok**	Drienov, Petrovany	40,07	RCOP v Prešove
SKUEV0748	**Šimonka***	Hermanovce n/T., Pavlovce, Petrovce, Zámutov, Zlatá Baňa	4563,84 (560,93)	RCOP v Prešove

/Zdroj: RÚSES okresu Prešov, 2010/

Územie európskeho významu Kamenná baba

Identifikačný kód: SKUEV0207

Katastrálne územie: Okres Prešov: Lačnov, Lipovce

Výmera lokality: 339,98 ha

Stupne ochrany: 2, 3, 5

Časová doba platnosti podmienok ochrany: od 1.1. do 31.12. každého roka

Odôvodnenie návrhu ochrany: Územie je navrhované z dôvodu ochrany biotopov európskeho významu: Lipovo-javorové sutinové lesy (*9180), Pionierske porasty na plytkých karbonátových a bázických substrátoch zväzu Alysso-Sedion albi (*6110), Suchomilné travinnobylinné a krovinové porasty na vápnitom podloží (6210), Karbonátové skalné steny a svahy so štrbinovou vegetáciou (8210), Kyslomilné bukové lesy (9110), Reliktné vápnomilné borovicové a smrekovcové lesy (91Q0), Bukové a jedľové kvetnaté lesy (9130), Vápnomilné bukové lesy (9150), Nesprístupnené jaskynné útvary (8310), Nížinné a podhorské kosné lúky (6510) a druhov európskeho významu: poniklec slovenský (* Pulsatilla slavica), črievičník papučkový (Cypripedium calceolus), vlk dravý (*Canis lupus), vydra riečna (Lutra lutra), netopier obyčajný (Myotis myotis), netopier brvitý (Myotis emarginatus), uchaňa čierna (Barbastella barbastellus) a podkovár malý (Rhinolophus hipposideros).

Územie európskeho významu Šindliar

Identifikačný kód: SKUEV0320

Katastrálne územie: Okres Prešov: Šindliar

Výmera lokality: 7,69 ha

Stupne ochrany: 4

Časová doba platnosti podmienok ochrany: od 1.1. do 31.12. každého roka

Odôvodnenie návrhu ochrany: Územie je navrhované z dôvodu ochrany biotopu európskeho významu: Kyslomilné bukové lesy (9110) a druhu európskeho významu: rys ostrovid (Lynx lynx).

Územie európskeho významu Salvátorské lúky

Identifikačný kód: SKUEV0321

Katastrálne územie: Okres Prešov: Lipovce, Šindliar

Výmera lokality: 2,68 ha

Stupne ochrany: 4

Časová doba platnosti podmienok ochrany: od 1.1. do 31.12. každého roka

Odôvodnenie návrhu ochrany: Územie je navrhované z dôvodu ochrany biotopov európskeho významu: Lužné vŕbovo-topoľové a jelšové lesy (*91E0), Slatiny s vysokým obsahom báz (7230), Vlhkomilné vysokobylinné lemové spoločenstvá na poriečnych nivách od nížin do alpínskeho stupňa (6430), Bezkolencové lúky (6410) a druhu európskeho významu: jazyčník sibírsky (Ligularia sibirica).

Územie európskeho významu Fintické svahy

Identifikačný kód: SKUEV0322

Katastrálne územie: Okres Prešov: Fintice, Fulianka, Kapušany, Terňa, Tulčík, Veľký Šariš, Záhradné

Výmera lokality: 753,90 ha

Stupne ochrany: 2, 3, 4, 5

Časová doba platnosti podmienok ochrany: od 1.1. do 31.12. každého roka

Odôvodnenie návrhu ochrany: Územie je navrhované z dôvodu ochrany biotopov európskeho významu: Pionierske spoločenstvá plytkých silikátových pôd (8230), Silikátové skalné steny a svahy so štrbinovou vegetáciou (8220), Subpanónske travinnobylinné porasty (*6240), Eurosibírske dubové lesy na spraši a piesku (91I0), Teplomilné panónske dubové lesy (*91H0), Lipovo-javorové sutinové lesy (*9180), Kyslomilné bukové lesy (9110), Bukové a jedľové kvetnaté lesy (9130) a druhov európskeho významu: kosatec bezlistý uhorský (Iris aphylla subsp. hungarica), poniklec veľkokvetý (Pulsatilla grandis), poniklec otvorený (Pulsatilla patens), ohniváčik veľký (Lycaena dispar), spriadač kostihojový (*Callimorpha quadripunctaria), ohniváčik (Lycaena helle), mlynárik východný (Leptidea morsei) a kunka žltobruchá (Bombina variegata).

Územie európskeho významu Demjatské kopce

Identifikačný kód: SKUEV0323

Katastrálne územie: Okres Prešov: Demjata, Veľký Slivník

Výmera lokality: 8,68 ha

Stupne ochrany: 4

Časová doba platnosti podmienok ochrany: od 1.1. do 31.12. každého roka

Odôvodnenie návrhu ochrany: Územie je navrhované z dôvodu ochrany biotopov európskeho významu: Porasty borievky obyčajnej (5130), Suchomilné travinnobylinné a krovinové porasty na vápnitom podloží (6210), Pionierske porasty na plytkých karbonátových a bázických substrátoch zväzu Alysso-Sedion albi (*6110) a druhov európskeho významu: hadinec červený (Echium russicum), poniklec veľkokvetý (Pulsatilla grandis), kunka žltobruchá (Bombina variegata) a netopier obyčajný (Myotis myotis).

Územie európskeho významu Dunitová skalka

Identifikačný kód: SKUEV0330

Katastrálne územie: Okres Prešov: Sedlice

Výmera lokality: 1,48 ha

Stupne ochrany: 3, 4

Časová doba platnosti podmienok ochrany: od 1.1. do 31.12. každého roka

Odôvodnenie návrhu ochrany: Územie je navrhované z dôvodu ochrany biotopov európskeho významu: Subpanónske travinnobylinné porasty (*6240), Silikátové skalné steny a svahy so štrbinovou vegetáciou (8220), Teplomilné panónske dubové lesy (*91H0) a druhov európskeho významu: slezinník nepravý (Asplenium adulterinum), koník východný (Odontopodisma rubripes) a Isophya stysi.

Územie európskeho významu Čergov

Identifikačný kód: SKUEV0332

Katastrálne územie: Okres Bardejov: Fričkovce, Hertník, Kríže, Livov, Šiba, Prešov: Babin Potok, Hradisko, Sabinov: Bodovce, Olejníkov, Ratvaj

Výmera lokality: 6063,43 ha

Stupne ochrany: 2, 3, 5

Časová doba platnosti podmienok ochrany: od 1.1. do 31.12. každého roka

Odôvodnenie návrhu ochrany: Územie je navrhované z dôvodu ochrany biotopov európskeho významu: Vlhkomilné vysokobylinné lemové spoločenstvá na poriečnych nivách od nížin do alpínskeho stupňa (6430), Nížinné a podhorské kosné lúky (6510), Kyslomilné bukové lesy (9110), Lipovo-javorové sutinové lesy (*9180), Javorovo-bukové horské lesy (9140), Bukové a jedľové kvetnaté lesy (9130), Kvetnaté vysokohorské a horské psicové porasty na silikátovom substráte (*6230) a druhov európskeho významu: kunka žltobruchá (Bombina variegata), mlok karpatský (Triturus montandoni), rys ostrovid (Lynx lynx), medveď hnedý (*Ursus arctos) a vlk dravý (*Canis lupus).

Územie európskeho významu Pusté pole

Identifikačný kód: SKUEV0390

Katastrálne územie: Okres Prešov: Zlatá Baňa

Výmera lokality: 90,35 ha

Stupne ochrany: 2, 4

Časová doba platnosti podmienok ochrany: od 1.1. do 31.12. každého roka

Odôvodnenie návrhu ochrany: Územie je navrhované z dôvodu ochrany biotopov európskeho významu: Lužné vŕbovo-topoľové a jelšové lesy (*91E0), Nížinné a podhorské kosné lúky (6510), Vlhkomilné vysokobylinné lemové spoločenstvá na poriečnych nivách od nížin do alpínskeho stupňa (6430), Subpanónske travinnobylinné porasty (*6240) a druhov európskeho významu: poniklec veľkokvetý (Pulsatilla grandis), koník východný (Odontopodisma rubripes) a Isophya stysi.

Územie európskeho významu Dubnícke bane

Identifikačný kód: SKUEV0401

Katastrálne územie: Okres Prešov: Červenica, Zlatá Baňa

Výmera lokality: 234,75 ha

Stupne ochrany: 2, 4

Časová doba platnosti podmienok ochrany: od 1.1. do 31.12. každého roka

Odôvodnenie návrhu ochrany: Územie je navrhované z dôvodu ochrany biotopov európskeho významu: Lužné vŕbovo-topoľové a jelšové lesy (*91E0), Kyslomilné bukové lesy (9110), Lipovo-javorové sutinové lesy (*9180), Bukové a jedľové kvetnaté lesy (9130), Nížinné a podhorské kosné lúky (6510) a druhov európskeho významu: spriadač kostihojový (*Callimorpha quadripunctaria), koník východný (Odontopodisma rubripes), kunka žltobruchá (Bombina variegata), vlk dravý (*Canis lupus), netopier obyčajný (Myotis myotis), netopier brvitý (Myotis emarginatus), netopier pobrežný (Myotis dasycneme), netopier ostrouchý (Myotis blythi), netopier veľkouchý (Myotis bechsteini), uchaňa čierna (Barbastella barbastellus), podkovár malý (Rhinolophus hipposideros) a podkovár veľký (Rhinolophus ferrumequinum). Pozn. Symbol* označuje prioritný biotop alebo druh

Chránené vtáčie územia

Sú vyhlasované podľa smernice o vtákoch (smernica Rady č.79/409/EHS o ochrane voľne žijúcich vtákov). Smernica chráni všetky pôvodné európske druhy, a to počas celého ich života, teda vajcia, mláďatá a hniezda. Okrem toho chráni aj biotopy, na ktoré sa jednotlivé druhy vtákov viažu. V praxi to znamená, že nikto nesmie usmrcovať, odchytávať alebo inak poškodzovať žiaden vtáčí druh ani jeho hniezdo a biotop, v ktorom žije. Zvláštny režim sa uplatňuje v prípade, ak ide o druhy, na ktoré sa môže poľovať. Smernica uvádza zoznam 181 druhov a poddruhov vtákov, pre ktoré sa spolu so sťahovavými vtákmi musia vyčleniť špeciálne chránené územia - chránené vtáčie územia.

Z Národného zoznamu navrhovaných chránených vtáčích území schváleného uznesením vlády SR č. 636/2003 z 9. júla 2003 do okresu Prešov zasahujú dve chránené vtáčie územia (CHVÚ). Obidve sa nachádzajú v južnej časti okresu. Ide o CHVÚ Slanské vrchy (SKCHVU025), ktoré v rámci okresu pokrývajú plochu 12 163,59 ha (13,02 %). Dostatok lesných komplexov s lúkami, poliami a pasienkami tu nachádzajú druhy viazané hniezdením na lesné biotopy a potravným teritóriom na ich široké okraje a otvorenú krajinu. Typickými predstaviteľmi Slanských vrchov sú orol kráľovský (Aquila heliaca), výr skalný (Bubo bubo), orol krikľavý (Aquila pomarina), včelár lesný (Pernis apivorus), žltochvost lesný (Phoenicurus phoenicurus) a bocian čierny (Ciconia nigra). CHVÚ Volovské vrchy (SKCHVU036) pokrývajú 2073,26 ha okresu (2,22 %). Jeho význam spočíva hlavne v ochrane dravcov a sov, ako aj ďatľa trojprstého (Picoides tridactylus), žlny sivej (Picus canus) i strakoša červenochrbtého (Lanius collurio) a iných. Možno povedať, že tieto územia zasahujú do okresu Prešov len okrajovo, ich celková výmera je podstatne väčšia. V rámci okresu aj širšieho okolia však plnia dôležitú funkciu hniezdisk a migračných trás vtákov.
CHVÚ Slanské vrchy bolo vyhlásené vyhláškou MŽP SR č. 193/2010 zo 16.4.2010 a CHVÚ Volovské vrchy vyhláškou MŽP SR č. 193/2010 zo 16.4.2010. Okrem CHVÚ Slanské vrchy a Volovské vrchy, ktorých vyhlášky začali platiť od 15.5.2010 sa pripravuje aj návrh na vyhlásenie CHVÚ Čergov. Čergov je jedným z piatich najvýznamnejších území na Slovensku pre hniezdenie sovy dlhochvostej (Strix uralensis) a pravidelne tu hniezdi viac ako 1% národnej populácie ďalších druhov, napr. muchárik bielokrký (Ficedula albicollis), muchárik červenohrdlý (Ficedula parva), jariabok hôrny (Bonasa bonasia), penica jarabá (Sylvia nisoria) a ďalšie druhy. Z celkovej výmery CHVÚ 35 849, 71 ha do okresu Prešov zasahuje 2 408,19 ha.

Vyhlásené chránené vtáčie územie Slanské vrchy

Výmera [ha]: 60 247,42

z toho v okrese Prešov: 12 464 ha

Prekryv so sieťou CHÚ: 1 %

V pôsobnosti: RCOP v Prešove, CHKO Latorica

Lokalizácia chráneného územia :

Kraj: Košický, Prešovský

Okres: Košice okolie, Prešov, Trebišov, Vranov nad Topľou

Kataster: Blažice, Bohdanovce, Boliarov, Ďurkov, Herľany, Kalša, Kecerovské Kostoľany, Kecerovský Lipovec, Košický Klečenov, Mudrovce, Nižná Kamenica, Nižná Myšľa, Nový Salaš, Opiná, Rákoš, Rankovce, Ruskov, Skároš, Slančík, Slanec, Slanská Huta, Slanské Nové Mesto, Svinica, Trstené pri Hornáde, Vyšná Kamenica, Vyšná Myšľa, Žirovce, Abranovce, Brestov, Červenica, Kokošovce, Lesíček, Lúčina, Mirkovce, Okružná, Podhradík, Ruská Nová Ves, Šarišská Poruba, Tuhrina, Vyšná Šebastová, Zlatá Baňa, Žehňa, Bačkov, Brezina, Byšta, Dargov, Kravany, Kuzmice, Malé Ozorovce, Sečovce, Slivník, Stankovce, Trnávka, Veľké Ozorovce, Veľký Kazimír, Zbehňov, Zemplínska Teplica, Banské, Cabov, Davidov, Hanušovce nad Topľou, Hermanovce nad Topľou, Hlinné, Juskova Voľa, Kamenná Poruba, Pavlovce, Petrovce, Rudlov, Sečovská Polianka, Vechec, Zámutov, Zlatník

Charakteristika: Dostatok lesných komlexov s lúkami, poliami a pasienkami tu nachádzajú druhy viazané hniezdením na lesné biotopy a potravným teritóriom na ich široké okraje a otvorenú krajinu.

Účelom vyhlásenia CHVÚ je zachovanie biotopov druhov vtákov európskeho významu orla kráľovského (Aquila heliaca), výra skalného (Bubo bubo), bociana čierneho (Ciconia nigra), orla krikľavého (Aquila pomarina), včelára lesného (Pernis apivorus,) ďatľa bielochrbtého (Dendrocopos leucotos), ďatľa prostredného (Dendrocopos medius), sovy dlhochvostej (Strix uralensis), penice jarabej (Sylvia nisoria), muchárika červenohrdlého (Ficedula parva), muchárika bielokrkého (Ficedula albicollis), strakoša červenochrbtého (Lanius collurio), orla skalného (Aquila chrysaetos), lelka lesného (Caprimulgus europaeus), škovránka stromového (Lullula arborea), jariabka hôrneho (Bonasa bonasia), prepelice poľnej (Coturnix coturnix), žltochvosta lesného (Phoenicurus poenicurus), krutihlava hnedého (Jynx torquilla), muchára sivého (Muscicapa striata), hrdličky poľnej (Streptopelia turtur), prhľaviara čiernohlavého (Saxicola torquata), chriašteľa poľného (Crex crex), žlny sivej (Picus canus) a ďatľa čierneho (Dryocopus martius).

Vyhlásené chránené vtáčie územie Volovské vrchy

Výmera [ha]: 121 420,65

z toho v okrese Prešov: 2 073 ha

Prekryv so sieťou CHÚ: 23 %

V pôsobnosti: NP Slovenský kras, NP Slovenský raj, RCOP v Prešove

Lokalizácia chráneného územia : Kraj :Košický, Prešovský Okres : Rožňava, Košice okolie, Košice I, Spišská Nová Ves, Gelnica, Prešov

Kataster : Bôrka, Čučma, Dobšiná, Drnava, Gemerská Poloma, Kováčová, Lúčka, Pača, Rožňava, Vlachovo, Bukovec, Hačava, Hodkovce, Hýľov, Jasov, Kostoľany nad Hornádom, Košická Belá, Košické Hámre, Kysak, Malá Ida, Malá Lodina, Medzev, Nováčany, Opátka, Poproč, Rudník, Ružín, Šemša, Sokoľ, Štós, Trebejov, Veľká Lodina, Vyšný Klátov, Vyšný Medzev, Zlatá Idka, Čermeľ, Kamenné, Kavečany, v okrese Spišská Nová Ves v katastrálnych územiach Hnilčík, Hnilec, Chrasť nad Hornádom, Kolinovce, Krompachy, Markušovce, Matejovce nad Hornádom, Mlynky, Nižné Slovinky, Olcnava, Poráč, Rudňany, Spišská Nová Ves, Spišské Vlachy, Šafárka, Teplička, Vítkovce, Vyšné Slovinky, Gelnica, Helcmanovce, Henclová, Kluknava, Kojšov, Margecany, Mníšek nad Hnilcom, Nálepkovo, Prakovce, Rolova Huta, Smolník, Smolnícka Huta, Stará Voda, Švedlár, Úhorná, Veľký Folkmar, Závadka, Žakarovce, Hrabkov, Klenov, Miklušovce a Sedlice.

Charakteristika : Výmerou najväčšie územie. Je tvorené viacerými typmi lesných porastov (ihličnaté, listnaté, zmiešané). Účelom vyhlásenia CHVÚ je zachovanie biotopov druhov vtákov európskeho významu bociana čierneho (Ciconia nigra), ďatľa bielochrbtého (Dendrocopos leucotos), ďatľa čierneho (Dryocopus martius), ďatľa prostredného (Dendrocopos medius), ďatľa trojprstého (Picoides tridactylus), hrdličky poľnej (Streptopelia turtur), jariabka hôrneho (Bonasa bonasia), krutihlava hnedého (Jynx torquilla), kuvika kapcavého (Aegolius funereus), kuvika vrabčieho (Glaucidium passerinum), muchárika bielokrkého (Ficedula albicollis), muchárika červenohrdlého (Ficedula parva), muchára sivého (Muscicapa striata), orla krikľavého (Aquila pomarina), orla skalného (Aquila chrysaetos), penice jarabej (Sylvia nisoria), prepelice poľnej (Coturnix coturnix), rybárika riečneho (Alcedo atthis), sovy dlhochvostej (Strix uralensis), strakoša červenochrbtého (Lanius collurio), tetrova hlucháňa (Tetrao tetrix), tetrova hoľniaka (Tetrao urogallus), včelára lesného (Pernis apivorus), výra skalného (Bubo bubo), žlny sivej (Picus canus) a biotopov sťahovavých druhov vtákov a zabezpečenie ich prežitia a rozmnožovania.

Navrhované chránené vtáčie územie Čergov

Výmera [ha]: 35 849,71 ha

z toho v okrese Prešov: 2 408 ha

Prekryv so sieťou CHÚ : %

V pôsobnosti : RCOP v Prešove, PIENAP

Lokalizácia chráneného územia :

Kraj : Prešovský

Okres : Bardejov, Stará Ľubovňa, Prešov, Sabinov

Kataster: Bogliarka, Fričkovce, Hertník, Hervartov, Kríže, Kružlov, Lenartov, Livov, Livovská Huta, Lukov, Malcov, Osikov, Richvald, Šiba, Venécia, Babin Potok, Geraltov, Hradisko pri Terni, Malý Slivník, Mošurov, Terňa, Závadka pri Terni, Bodovce, Červená Voda, Červenica pri Sabinove, Drienica, Hanigovce, Jakovany, Jakubovany pod Čergovom, Kamenica, Ľutina, Milpoš, Olejníkov, Pečovská Nová Ves, Ratvaj, Sabinov, Šarišské Sokolovce, Zálesie, Čirč, Kyjov, Ľubotín, Obručné, Ruská Voľa nad Popradom, Šarišské Jastrabie
Odôvodnenie návrhu ochrany:
Účelom vyhlásenia CHVÚ bude zabezpečenie priaznivého stavu biotopov druhov vtákov európskeho významu a biotopov sťahovavých druhov vtákov, a to: sova dlhochvostá (Strix uralensis), muchárik bielokrký (Ficedula albicollis), muchárik červenohrdlý (Ficedula parva), jariabok hôrny (Bonasa bonasia). penica jarabá (Sylvia nisoria), ďateľ bielochrbtý (Dendrocopos leucotos), ďateľ čierny (Dryocopus martius), chriašteľ poľný (Crex crex), žlna sivá (Picus canus), kuvik vrabčí (Glaucidium passerinum), ďateľ trojprstý (Picoides tridactylus), kuvik kapcavý (Aegolius funereus), lelek lesný (Caprimulgus europaeus), orol krikľavý (Aquila pomarina), rybárik riečny (Alcedo atthis), včelár lesný (Pernis apivorus), bocian čierny (Ciconia nigra), tetrov hôlniak (Tetrao tetrix), orol skalný (Aquila chrysaetos), muchár sivý (Muscicapa striata), pŕhľaviar čiernohlavý (Saxicola torquata), krutihlav hnedý (Jynx torquilla), žltochvost lesný (Phoenicurus phoenicurus) a prepelica poľná (Coturnix coturnix) a zabezpečenie podmienok ich prežitia a rozmnožovania.

Cieľom ochrany v CHVÚ je zachovanie a obnova ekosystémov významných pre druhy vtákov, pre ktoré je oblasť vyhlásená v ich prirodzenom areáli rozšírenia, ako aj zabezpečenie podmienok pre zachovanie populácie týchto druhov v priaznivom stave z hľadiska ich ochrany. Rozhodujúce pre zachovanie populácie druhov vtákov je preto zachovanie, prípadne zlepšenie ekologického stavu biotopov, na ktoré sú tieto druhy viazané.

Lokality vyhlásené podľa medzinárodných dohovorov

Majú za cieľ výraznejšie potvrdiť nadnárodný význam lokalít, môžu byť súčasťou chránených, resp. navrhovaných chránených území. Zakresľujú sa plošne, ale aj bodovo:

- lokality podľa Dohovoru o mokradiach majúcich medzinárodný význam, najmä ako biotopy vodného vtáctva (Ramsarská konvencia),
- lokality podľa Dohovoru o ochrane svetového kultúrneho a prírodného dedičstva,

- biosférické rezervácie Programu UNESCO "Človek a biosféra" (MaB) a i.

V okrese Prešov sa nenachádzajú žiadne z vyššie spomínaných lokalít vyhlásených podľa medzinárodných dohovorov.

Chránené druhy rastlín a živočíchov (druhová ochrana)

Druhová ochrana rastlín a živočíchov je zabezpečená zákonom NR SR č. 543/2002 Z. z. o ochrane prírody a krajiny v znení neskorších predpisov a o zmene a doplnení niektorých zákonov a jeho vykonávacou vyhláškou MŽP SR č. 24/2003, novelizovanou vyhláškou MŽP SR č. 492/2006, ktorou sa vykonáva zákon NR SR č. 543/2002 Z. z. o ochrane prírody a krajiny v znení neskorších predpisov, ale aj Zákonom NR SR č. 15/2005 Z. z. o ochrane druhov voľne žijúcich živočíchov a voľne rastúcich rastlín reguláciou obchodu s nimi a o zmene a doplnení niektorých zákonov, vyhláškou MŽP SR č. 110/2005 Z. z., ktorou sa vykonávajú niektoré ustanovenia zákona o ochrane druhov voľne žijúcich živočíchov a voľne rastúcich rastlín reguláciou obchodu s nimi a o zmene a doplnení niektorých zákonov, zákonom NR SR č. 452/2007 Z. z., ktorým sa mení a dopĺňa zákon NR SR č. 15/2005 Z. z. o ochrane druhov voľne žijúcich živočíchov a voľne rastúcich rastlín reguláciou obchodu s nimi a o zmene a doplnení niektorých zákonov, v znení zákona NR SR č. 672/2006 Z. z.

Chránené druhy rastlín

Rastlinstvo okresu Prešov sa vyznačuje zastúpením rôznych typov spoločenstiev, z ktorých niektoré vykazujú vysokú druhovú diverzitu a vyskytujú sa v nich viaceré chránené, vzácne a ohrozené druhy rastlín. Zoznam najcennejších rastlinných druhov na území okresu Prešov, podľa kategórií ohrozenosti IUCN, je uvedený v tabuľke. č. 5.

Tabuľka 5 *Prehľad chránených druhov flóry okresu Prešov*

Latinský názov	Slovenský názov	Ochrana	Ohrozenie
Aconitum moldavicum	prilbica moldavská	§ N	VU
Adonis aestivalis	hlaváčik letný		LR:nt
Anemone sylvestris	veternica lesná		LR:nt
Aquilegia vulgaris	orlíček obyčajný		LR:nt
Asplenium adulterinum	slezinník nepravý	§ E	CR
Asplenium cuneifolium	slezinník klinovolistý	§ N	CR
Aster amelloides	astra spišská		LR:nt
Asyneuma canescens	klasovec sivastý	§ N	EN
Blechnum spicant	rebrovka rôznolistá	§ N	VU
Butomus umbellatus	okrasa okolíkatá		VU
Campanula bononiensis	zvonček boloňský	§ N	LR:nt
Carex canescens	ostrica sivastá		LR:nt
Carex distans	ostrica vzdialená		LR:nt

Carex flava	ostrica žltá		VU
Carex paniculata	ostrica metlinatá		VU
Carex transsilvanica	ostrica sedmohradská		VU
Centarium pulchellum	zemežlč spanilá	§ N	VU
Cephalanthera rubra	prilbovka červená	§ N	VU
Cephalanthera damasonium	prilbovka biela	§ N	VU
Cephalanthera longifolia	prilbovka dlholistá	§ N	VU
Cerasus fruticosa	čerešňa krovitá		VU
Chenopodium urbicum	mrlík mestský		VU
Chenopodium vulvaria	mrlík smradľavý		VU
Chimaphila umbellata	zimoľub okolíkatý	§ N	EN
Clematis alpina	plamienok alpínsky	§ N	VU
Clematis recta	plamienok rovný		LR:nt
Conringia orientalis	konringia východná		EN
Convallaria majalis	konvalinka voňavá		LR:nt
Corallorhiza trifida	koralica lesná	§ N	VU
Crocus heuffelianus	šafran karpatský	§ N	EN
Cyanus segutm	nevädza poľná		LR:nt
Cypripedium calceolus	črievičník papučkový	§ E	VU
Cystopteris sudetica	pľuzgiernik sudetský		LR:nt
Dactylorhiza incarnata	vstavačovec strmolistý	§ N	EN
Dactylorhiza majalis	vstavačovec májový	§ N	VU
Dactylorhiza sambucina	vstavačovec bazový	§ N	VU
Daphne cneorum	lykovec voňavý	§ N	EN
Dianthus superbus subsp. superbus	klinček pyšný pravý	§ N	EN
Drosera rotundifolia	rosička okrúhlolistá	§ N	EN
Echium russicum	hadinec červený	§ E	EN
Epipactis helleborine	kruštík širokolistý		LR:nt
Epipactis palustris	kruštík močiarny	§ N	VU
Epipactis purpurata	kruštík modrofialový		VU
Equisetum pratense	prasličkа lúčna		LR:nt
Eryngium planum	kotúč modrastý	§ N	VU
Gagea minima	krivec najmenší	§ N	CR
Galanthus nivalis	snežienka jarná		LR:nt
Gentiana cruciata	horec krížatý		LR:nt
Gentiana pneumonanthe	horec pľúcny	§ N	EN
Gentianopsis ciliata	pahorec brvitý		LR:nt
Gladiolus imbricatus	mečík škridlicovitý	§ N	VU
Goodyera repns	smrečinovec plazivý	§ N	VU
Hppochaete variegata	prasličkovka pestrá	§ N	EN
Iris aphylla subsp. hungarica	kosatec bezlistý uhorský	§ E	CR
Iris graminea	kosatec trávolistý	§ N	VU
Iris sibirica	kosatec sibírsky	§ N	VU
Lactuca perennis	šalát trváci		LR:nt
Leersia oryzoides	tajnička ryžovitá		VU
Ligularia sibirica	jazyčník sibírsky	§ E	VU
Lilium martagon	ľalia zlatohlavá		LR:nt

Linum austriacum	ľan rakúsky		LR:nt
Linum flavum	ľan žltý		LR:nt
Listera ovata	bradáčik vajcovitý		VU
Lycopodium annotinum	plavúň pučivý	§ N	LR:nt
Lycopodium clavatum	plavúň obyčajný	§ N	LR:nt
Molinia caerulea	bezkolenec belasý		VU
Moneses uniflora	jednokvietok veľkokvetý		LR:nt
Myricaria germanica	myrikovka nemecká		VU
Oenanthe banatica	halucha banátska	§ N	VU
Ophioglossum vulgatum	hadivka obyčajná	§ N	EN
Ophrys insectifera	hmyzovník muchovitý	§ N	VU
Orchis mascula	vstavač mužský	§ N	VU
Orchis militaris	vstavč vojenský	§ N	VU
Orchis morio	vstavač obyčajný	§ N	VU
Parnassia palustris	bielokvet močiarny		LR:nt
Platanthera bifolia	vemenník dvojlistý		VU
Platanthera chlorantha	vemenník zelenkastý	§ N	EN
Primula auricula	prvosienka holá	§ N	VU
Pseudorchis albida	bieloprst belavý	§ N	EN
Pulsatilla grandis	poniklec veľkokvetý	§ E	VU
Pulsatilla patens	poniklec otvorený	§ E	EN
Pulsatilla slavica	poniklec slovenský	§ E*	EN
Pulsatilla subslavica	poniklec prostredný	§ E*	EN
Pyrola chlorantha	hruštička zelená	§ N	VU
Ranunculus arvensis	iskerník roľný		LR:nt
Ranunculus lingua	iskeník veľký	§ N	VU
Salix rosmarinifolia	vŕba rozmarínolistá	§ N	VU
Salix starkeana	vŕba sivozelená	§ N	CR
Schoenoplectus tabernaemontani	škripinec dvojbliznový		LR:nt
Scorzonera humilis	hadomor nízky		EN
Scrophularia umbrosa	krtičník tôňomilný		LR:nt
Scutellaria hastifolia	šišak gracovitý		VU
Stipa pulcherrima	kavyľ pôvabný	§ N	EN
Tetragonolobus maritimus	paľadenc prímorský		VU
Thalictrum lucidum	žltuška lesklá		EN
Thymelaea passerina	vrabcovník obyčajný		LR:nt
Traunsteinera globosa	pavstavač hlavatý	§ N	VU
Utricularia vulgaris	bublinatka obyčajná	§ N	VU
Veronica scutellata	veronika štítovitá	§ N	LR:nt
Viola rupestris	fialka skalná		LR:nt
Waldsteinia geoides	valdštejnka kuklíkovitá	§ N	LR:nt
Woodsia ilvensis	vudsia skalná		VU

/Zdroj: ŠOP SR, RCOP Prešov, 2010

Vysvetlivky:
§ E - chránený druh európskeho významu
§ N - chránený druh národného významu
* - prioritný druh

Kategórie ohrozenosti podľa IUCN:
CR (critically endangered) - kriticky ohrozený
EN (endangered) - ohrozený
VU (vulnerable) - zraniteľný
LR (lower risk) - menej ohrozený
podkategória:nt (near threatened) - takmer ohrozený

Chránené druhy živočíchov

Živočíšstvo okresu Prešov sa vyznačuje zastúpením viacerých druhov fauny, z nich niektoré vykazujú vysokú druhovú diverzitu a vyskytujú sa medzi nimi viaceré chránené, vzácne a ohrozené druhy.

Zoznam najcennejších živočíšnych druhov na území okresu Prešov, podľa kategórií ohrozenosti IUCN, je uvedený v tabuľke. č. 6.

Tabuľka 6 *Prehľad chránených druhov fauny okresu Prešov*

Obojživelníky - Amphibia

Druh /vedecké meno/	Threat	Ohrozenie druhy	druhy	Name
			európskeho významu	národného významu	
Bombina variegata (Linnaeus, 1758) – kunka žltobruchá		LR:cd	+	+
Bufo bufo (Linnaeus, 1758) – ropucha bradavičnatá	LR:cd		+	
Bufo viridis Laurenti,1768 – ropucha zelená		LR:cd	+	+
Hyla arborea (Linnaeus, 1758) – rosnička zelená	LR:nt	+	+	
Pelobates fuscus (Laurenti, 1768) – hrabavka škvrnitá		LR:cd	+	+
Rana dalmatina Bonaparte, 1839 – skokan štíhly		LR:lc	+	+
Rana kl. esculenta Linnaeus, 1758 – skokan zelený	LR:nt		+	
Rana temporaria Linnaeus, 1758 – skokan hnedý	LR:lc		+	
Salamandra salamandra (Linnaeus, 1758) – salamandra škvrnitá	LR:nt		+	
Triturus montandoni (Boulenger, 1880) – mlok karpatský		VU		+
Triturus vulgaris (Linnaeus, 1758) – mlok bodkovaný	VU		+	

Plazy – Reptilia

Druh /vedecké meno/	Threat	Ohrozenie druhy	druhy	Name
			európskeho významu	národného významu	
Anguis fragilis Linnaeus, 1758 – slepúch lámavý		LR:nt		+
Coronella austriaca Laurenti, 1768 – užovka hladká	VU	+	+	
Lacerta agilis Linnaeus, 1758 – jašterica obyčajná		+	+	
Natrix natrix (Linnaeus, 1758) – užovka obyčajná	LR:lc		+	
Podarcis (Lacerta) muralis (Laurenti, 1768) – jašterica múrová	LR:lc	+	+	
Vipera berus (Linnaeus, 1758) - vretenica obyčajná	VU		+	

Vtáky – Aves

Druh /vedecké meno/	Threat	Ohrozenie druhy európskeho významu	druhy národného významu	Name
Accipiter gentilis (Linnaeus, 1758) – jastrab lesný	LR:lc		+	
Accipiter nisus (Linnaeus, 1758) – jastrab krahulec	LR:lc		+	
Acrocephalus palustris (Bechstein, 1798) – trsteniarik spevavý			+	
Acrocephalus schoenobaenus (Linnaeus, 1758) – trsteniarik pásikový			+	
Actitis hypoleucos (Linnaeus, 1758) – kalužiak riečny	LR:lc		+	
Aegithalos caudatus (Linnaeus, 1758) – mlynárka dlhochvostá			+	
Alauda arvensis Linnaeus, 1758 – škovránok poľný			+	
Alcedo atthis (Linnaeus, 1758) – rybárik riečny		LR:nt	+	+
Anas clypeata Linnaeus, 1758 – kačica lyžičiarka	VU		+	
Anas platyrhynchos Linnaeus, 1758 – kačica divá		+	+	
Anthus trivialis (Linnaeus, 1758) – ľabtuška lesná			+	
Apus apus (Linnaeus, 1758) – dážďovník tmavý				+
Aquila chrysaetos (Linnaeus, 1758) – orol skalný	VU	+	+	
Aquila pomarina Brehm, 1831 – orol krikľavý		LR:nt	+	+
Ardea cinerea Linnaeus, 1758 – volavka popolavá	LR:nt		+	
Asio otus (Linnaeus, 1758) – myšiarka ušatá				+
Bubo bubo (Linnaeus, 1758) – výr skalný	NE	+	+	
Buteo buteo (Linnaeus, 1758) – myšiak lesný		LR:lc		+
Carduelis cannabina (Linnaeus, 1758) – stehlík konopiar				+
Carduelis carduelis (Linnaeus, 1758) – stehlík pestrý			+	
Carduelis chloris (Linnaeus, 1758) – stehlík zelený			+	
Carduelis spinus (Linnaeus, 1758) – stehlík čížavý			+	
Certhia familiaris Linnaeus, 1758 – kôrovník dlhoprstý			+	
Ciconia ciconia (Linnaeus, 1758) – bocian biely		LR:lc	+	+
Ciconia nigra (Linnaeus, 1758) – bocian čierny		LR:nt	+	+
Circus aeruginosus (Linnaeus, 1758) – kaňa močiarna		LR:lc	+	+
Coccothraustes coccothraustes (Linnaeus, 1758) – glezg hrubozobý				+
Columba oenas Linnaeus, 1758 – holub plúžik		LR:lc		+
Columba palumbus Linnaeus, 1758 – holub hrivnák			+	
Corvus corax Linnaeus, 1758 – krkavec čierny				+
Corvus corone cornix Linnaeus, 1758 – vrana túlavá			+	
Coturnix coturnix (Linnaeus, 1758) – prepelica poľná	LR:nt		+	
Crex crex (Linnaeus, 1758) – chrapkáč poľný		LR:cd	+	+
Cuculus canorus Linnaeus, 1758 – kukučka jarabá			+	
Delichon urbica (Linnaeus, 1758) – belorítka domová			+	
Dendrocopos leucotos (Bechstein, 1803) – ďateľ bielochrbtý	LR:nt	+	+	
Dendrocopos major (Linnaeus, 1758) – ďateľ veľký			+	
Dendrocopos medius (Linnaeus, 1758) - ďateľ prostredný			+	+
Dendrocopos minor (Linnaeus, 1758) – ďateľ malý			+	
Dendrocopos syriacus (Linnaeus, 1758) – ďateľ hnedkavý			+	+
Dryocopus martius (Linnaeus, 1758) – ďateľ čierny		+	+	
Emberiza citrinella Linnaeus, 1758 – strnádka žltá			+	
Emberiza schoeniclus (Linnaeus, 1758) – strnádka trsťová				+
Erithacus rubecula (Linnaeus, 1758) – slávik červienka				+

Falco subbuteo Linnaeus, 1758 – sokol lastovičiar	LR:nt				+	
Falco tinnunculus Linnaeus, 1758 – sokol myšiar	LR:lc				+	
Ficedula albicollis (Temminck, 1815) muchárik bielokrký				+		+
Ficedula parva (Bechstein, 1794) – muchárik červenohrdlý	NE		+		+	
Fringilla coelebs Linnaeus, 1758 – pinka lesná						+
Fulica atra Linnaeus, 1758 – lyska čierna					+	
Galerida cristata (Linnaeus, 1758) – pipíška chochlatá	LR:nt				+	
Garrulus glandarius (Linnaeus, 1758) – sojka škriekavá						+
Hippolais icterina (Linnaeus, 1758) – sedmohlások hájový						+
Hirundo rustica Linnaeus, 1758 – lastovička domová					+	
Jynx torquilla Linnaeus, 1758 – krutihlav hnedý						+
Lanius collurio Linnaeus, 1758 – strakoš červenochrbtý				+		+
Lanius excubitor Linnaeus, 1758 – strakoš sivý		LR:nt				+
Locustella fluviatilis (Wolf, 1810) – svrčiak riečny					+	
Lullula arborea (Linnaeus, 1758) – škovránok stromový				+		+
Luscinia megarhynchos CH. L. Brehm, 1831 – slávik krovinový					+	
Merops apiaster Linnaeus, 1758 – včelárik zlatý		LR:nt				+
Miliaria calandra (Linnaeus, 1758) – strnádka lúčna	NE				+	
Motacilla alba Linnaeus, 1758 – trasochvost biely					+	
Motacilla cinerea Linnaeus, 1758 – trasochvost horský						+
Motacilla flava (Linnaeus, 1758) – trasochvost žltý	LR:lc				+	
Oriolus oriolus (Linnaeus, 1758) – vlha hájová						+
Parus caeruleus Linnaeus, 1758 – sýkorka belasá					+	
Parus major Linnaeus, 1758 – sýkorka bielolíca						+
Parus montanus (Baldenstein, 1827) – sýkorka čiernohlavá					+	
Parus palustris Linnaeus, 1758 – sýkorka lesklohlavá					+	
Passer domesticus (Linnaeus, 1758) – vrabec domový						+
Passer montanus (Linnaeus, 1758) – vrabec poľný					+	
Perdix perdix (Linnaeus, 1758) – jarabica poľná		LR:nt				+
Pernis apivorus (Linnaeus, 1758) – včelár lesný		LR:lc		+		+
Phasianus colchicus Linnaeus, 1758 – bažant poľovný						+
Phoenicurus ochruros (Gmelin, 1774) – žltochvost domový					+	
Phylloscopus collybita (Vieillot, 1817) - kolibkárik čipčavý					+	
Phylloscopus sibilatrix (Bechstein, 1793) – kolibkárik sykavý					+	
Phylloscopus trochilus (Linnaeus, 1758) – kolibkárik spevavý					+	
Pica pica (Linnaeus, 1758) – straka čiernozobá						+
Picoides tridactylus Linnaeus, 1758 – ďateľ trojprstý			+		+	
Picus canus Gmelin, 1788 – žlna sivá				+		+
Picus viridis Linnaeus, 1758 – žlna zelená					+	
Saxicola rubetra (Linnaeus, 1758) – přhľaviar červenkastý		LR:lc		+		+
Saxicola torquata (Linnaeus, 1766) – přhľaviar čiernohlavý					+	
Scolopax rusticola Linnaeus, 1758 – sluka lesná						+
Serinus serinus (Linnaeus, 1766) – kanárik záhradný					+	
Sitta europaea Linnaeus, 1758 – brhlík lesný						+
Streptopelia decaocto (Linnaeus, 1758) – hrdlička záhradná					+	
Streptopelia turtur (Linnaeus, 1758) – hrdlička poľná					+	
Strix aluco Linnaeus, 1758 – sova lesná					+	
Sturnus vulgaris Linnaeus, 1758 – škorec lesklý						+
Sylvia atricapilla (Linnaeus, 1758) – penica čiernohlavá						+

Sylvia borin (Boddaert, 1783) – penica slávikovitá				+	
Sylvia communis Latham, 1787 – penica hnedokrídla				+	
Sylvia curruca (Linnaeus, 1758) – penica popolavá				+	
Sylvia nisoria (Bechstein, 1795) – penica jarabá			+		+
Tachybaptus ruficolis (Pallas, 1764) – potápka hnedá				+	
Troglodytes troglodytes (Linnaeus, 1758) – oriešok hnedý					+
Turdus merula (Linnaeus, 1758) – drozd čierny					+
Turdus philomelos CH. L. Brehm, 1831 – drozd plavý				+	
Turdus pilaris (Linnaeus, 1758) – drozd čvíkotavý				+	
Turdus viscivorus (Linnaeus, 1758) – drozd trskotavý				+	
Upupa epops Linnaeus, 1758 – dudok chochlatý		VU			+
Vanellus vanellus Linnaeus, 1758 – cíbik chochlatý	LR:lc			+	

Cicavce – Mammalia

Druh /vedecké meno/	Threat	Ohrozenie druhy	druhy	Name
		európskeho významu	národného významu	
Barbastella barbastellus (Schreber, 1774) – uchaňa čierna		LR:cd	+	+
Cricetus cricetus (Linnaeus, 1758) – chrček poľný	DD	+	+	
Crocidura suaveolens Pallas, 1811 – bielozubka krpatá		LR:lc		+
Eptesicus nilssoni (Keyserling Blasius, 1839)		LR:lc	+	+
Eptesicus serotinus (Schreber, 1774) – večernica pozdná		DD	+	+
Erinaceus concolor Linnaeus, 1758 – jež východoeurópsky			+	
Felis silvestris Schreber, 1775 – mačka divá		VU	+	+
Glis glis (Linnaeus, 1766) – plch sivý				+
Lutra lutra (Linnaeus, 1758) – vydra riečna	VU	+	+	
Lynx lynx (Linnaeus, 1758) – rys ostrovid	EN	+	+	
Muscardinus avellanarius (Linnaeus, 1758) – plšik lieskový	LR:lc	+	+	
Myotis bechsteini (Kuhl, 1817) – netopier veľkouchý	LR:lc	+	+	
Myotis blythi (Tomes, 1857) – netopier ostrouchý	LR:cd	+	+	
Myotis brandti (Eversmann, 1845) – netopier Brandtov		VU	+	+
Myotis dasycneme (Boie, 1825) – netopier pobrežný	VU	+	+	
Myotis daubentoni (Kuhl, 1817) – netopier vodný	LR:lc	+	+	
Myotis emarginatus (E. Geffroy, 1806) – netopier brvitý		VU	+	+
Myotis myotis (Borkhausen, 1797) – netopier obyčajný		LR:cd	+	+
Myotis mystacinus (Kuhl, 1817) – netopier fúzatý	VU	+	+	
Myotis nattereri (Kuhl, 1817) – netopier riasnatý		LR:nt	+	+
Neomys fodiens (Pennant, 1771) – dulovnica väčšia	LR:nt		+	
Neomys anomalus Mottaz, 1907 – dulovnica menšia	LR:nt		+	
Nyctalus leisleri (Kuhl, 1817) – raniak malý	DD	+	+	
Nyctalus noctula (Schreber, 1774) – raniak hrdzavý	LR:lc	+	+	
Pipistrellus pipistrellus (Schreber, 1774) – večernica malá		LR:lc	+	+
Plecotus auritus (Linnaeus, 1758) – ucháč svetlý		LR:nt	+	+
Plecotus austriacus (Fischer, 1829) – ucháč sivý		LR:nt	+	+
Rhinolophus ferrumequinum (Schreber,1774) – podkovár veľký	EN	+	+	
Rhinolophus hipposideros (Bechstein, 1800) – podkovár malý	LR:cd	+	+	
Sciurus vulgaris Linnaeus, 1758 – veverica obyčajná	LR:lc		+	
Sorex minutus Linnaeus, 1766 – piskor malý				+

Sorex araneus Linnaeus, 1758 – piskor obyčajný			+
Vespertilio murinus Linnaeus, 1758 – večernica pestrá	DD	+	+

/Zdroj: Fulín, 2010/

Kategórie ohrozenosti podľa IUCN:
EN – Endangered - ohrozený VU – Vulnerable – zraniteľný
LR – Lower Risk – menej ohrozený
s podkategóriamicd – Conservation Dependent – závislý na ochrane
nt – Near Threatened – takmer ohrozený lc – Least Concern – najmenej ohrozený
DD – Data Deficient – údajovo nedostatočný

2. Charakteristika životného prostredia vrátane zdravia v oblastiach, ktoré budú významne ovplyvnené.

Stav životného prostredia POSK je pravidelne aktualizovaný v Správach o stave životného prostredia Slovenskej republiky, ktoré MŽP SR zverejňuje v zmysle zákona č. 17/1992 Zb. o životnom prostredí a zákona č. 205/2004 Z.z. o zhromažďovaní, odovzdávaní a šírení informácií o životnom prostredí a o zmene a doplnení niektorých zákonov. Podrobnejšie informácie o stave životného prostredia sú dostupné v dokumente Územný plán regiónu Prešovského kraja (www.prešov-vuc.sk). Informácie o jednotlivých zložkách životného prostredia sú verejne prístupné tiež na portáli www.enviroportal.sk.

Kvalita ovzdušia je spomedzi všetkých faktorov určujúcich kvalitu životného prostredia obyvateľmi najčastejšie pociťovaná a hodnotená. Preto ho môžeme považovať za jeden z najvýznamnejších faktorov spokojnosti obyvateľstva so životným prostredím.

Lokálne znečistenie ovzdušia

Zákon o ovzduší č. 478/2002 harmonizoval princípy hodnotenia kvality ovzdušia s legislatívou EÚ. V súlade s týmito požiadavkami bolo územie SR rozdelené do zón a aglomerácií a v každej boli vyhodnotené príslušné monitorovacie režimy.

Tabuľka 7 *Vyhodnotenie znečistenia ovzdušia podľa limitných hodnôt na ochranu ľudského zdravia a limitných hodnôt zvýšených o medzu tolerancie (MT) na monitorovacích staniciach v Prešovskom kraji za rok 2018*

Zložka	**Ochrana zdravia**									**VHP[2)]**	
	SO_2		**NO_2**		**NO_2+MT**		**PM_{10}**		**Benzén**	**SO_2**	**NO_2**
Doba spriemerovania	1 hod	24 hod	1 hod	1 rok	8 hod[1].	1 rok	24 hod	1 rok	1 rok	3 hod kĺzavý priemer	3 hod kĺzavý priemer
Limitná hodnota [µg/m³](počet prekročení)	350 (24)	125 (3)	200 (18)	40	10 000	40	50 (35)	40	5	500	400
Prešov, Solivarská			0	19,1	0	19,1	**64**	35,3	1,3		0

/Zdroj: OÚ PO/

1) maximálna osemhodinová koncentrácia

2) Limitné hodnoty pre výstražné hraničné prahy
Znečisťujúce látky, ktoré prekročili limitnú hodnotu sú zvýraznené hrubým písmom
Označenie výťažnosti: > 90%, a 75–90 %, b 50–75 %, c < 50 % platných meraní
Hlavný podiel na znečisťovaní ovzdušia majú mestské kotolne, automobilová doprava, ako aj sekundárna prašnosť.

Zóna Prešovský kraj

Na monitorovacej stanici Prešov - Solivarská počty prekročení dennej limitnej hodnoty na ochranu zdravia ľudí pre PM10 v roku 2008 vzrástli v porovnaní s rokom 2007 viac ako 2 -násobne a prekročili 24 - hodinovú limitnú hodnotu. Ostatné znečisťujúce látky neprekročili limitné ani cieľové hodnoty. Na základe výsledkov štatistickej analýzy je možné predpokladať, že príspevok lokálnych zdrojov k znečisteniu ovzdušia PM10 sa v tejto zóne pohybuje v rozsahu od 15 % do 35 %. Hlavné lokálne zdroje sú podobné, ako v iných zónach, t.j. najmä doprava, suspenzia a resuspenzia častíc z nedostatočne čistených komunikácií, stavenísk, skládok sypkých materiálov, vykurovanie domov na tuhé palivá a poľnohospodárstvo, ktoré priamo vplývajú na úroveň znečistenia.

Jemné suspendované častice - PM10

Najväčší problém predstavuje v súčasnosti znečistenie suspendovanými časticami (PM10). Úroveň znečistenia ovzdušia PM10 môžeme charakterizovať ako závažnú, preto podrobná analýza znečistenia modelovými výpočtami je dôležitá z dôvodu zistenia pôvodu emisií. Určenie pôvodu, resp. podielu jednotlivých zdrojov znečisťovania ovzdušia k celkovej úrovni znečistenia ovzdušia s PM10 patrí k najproblematickejšej úlohe (zimný posyp). Možnosti lokálnych opatrení na redukciu úrovne PM10 sú s ohľadom na vysoké pozadie obmedzené. Kým pre ostatné hodnotené znečisťujúce látky úroveň pozaďovej koncentrácie predstavuje podiel z limitnej hodnoty do 20 %, pre PM10 je to až do 70 %, čo znamená prekračovanie hornej medze na hodnotenie kvality ovzdušia už samotným pozadím. Mestské pozadie PM10 v blízkosti väčších miest na Slovensku (nad 50 000 obyvateľov) sa predpokladá medzi 25–30 µg.m–3. Vo všetkých týchto mestách je vysoká pravdepodobnosť prekračovania priemernej ročnej koncentrácie 40 µg.m–3 a najmä priemerných denných koncentrácií 50 µg.m–3 vo väčšom počte ako v 35 dňoch. V štruktúre výrobcov tepla na širšom území mesta Prešov dominujú zdroje väčšie ako 300 kW s celkovým množstvom vyrobeného tepla 1 500 TJ, 41 bytových kotolní Spravbytu, a. s. Prešov s celkovým množstvom vyrobeného tepla 1 170 TJ a Tepláreň Košice, a. s., prekleňovací zdroj tepla Prešov s 1 130 TJ. Týchto dominantných výrobcov tepla dopĺňajú zdroje od 50 do 300 kW s celkovým množstvom vyrobeného tepla 230 TJ a lokálne zdroje tepla v rodinných domoch s celkovým množstvom vyrobeného tepla 470 TJ.

Celkové množstvo vyrobeného tepla na širšom území mesta Prešov tak dosahuje 3 500 TJ. Pri výrobe cca 3 500 TJ tepla na širšom území mesta Prešov vznikne 197 050 ton emisií CO2.

Zaťaženie prostredia hlukom

Hluk je akustický fenomén zvuku. Nebezpečnosť jeho pôsobenia na človeka spočíva v tom, že zvuková energia podlieha entropii a v porovnaní s napr. chemickými látkami nezanecháva žiadne rezíduá. Podľa poznatkov zdravotníctva hluková hladina 65 dB (A) predstavuje hranicu, od ktorej začína byť negatívne ovplyvňovaný vegetatívny nervový systém. Podľa vyhlášky Ministerstva zdravotníctva č. 14/1977 Zb. sú stanovené prípustné hodnoty hluku 60 dB (A) pre dennú dobu a 50 dB (A) pre nočnú dobu. Problematikou zaťaženia obyvateľov hlukom sa zaoberá Štátny zdravotný ústav Slovenskej republiky. Základná úprava na úseku ochrany zdravia pred nepriaznivými účinkami hluku a vibrácií je v súčasnosti upravená§13 zákona NR SR č. 514/2001 Z.z., ktorým sa mení a dopĺňa zákon NR SR č. 272/1994 Z.z. o ochrane zdravia ľudí v znení neskorších predpisov. Nariadenie vlády SR č. 40/2002 Z.z. o ochrane zdravia pred hlukom a vibráciami vyplývajúce z vyššie citovaného zákona zrušilo vyhlášku MZ SSR č. 14/1997 a zároveň zabezpečilo komplexné riešenie tejto problematiky - v súlade s najnovšími poznatkami, ako aj požiadavkami Európskej únie.

S výnimkou mesta Prešov sa v žiadnom sídle na území okresu nevykonáva monitoring hlukovej záťaže z cestnej dopravy. Výrazný zdroj hlukovej záťaže v otvorenej krajine predstavuje predovšetkým trasa diaľnice D1 v úseku Tunel Branisko – Fričovce a Prešov – hranica okresu Košice okolie, cesta I/68 v úseku hranica okresu Sabinov – Prešov a cesta I/73 v úseku Lipníky – hranica okresu Svidník. Výrazný zdroj hlukovej záťaže v krajine i pre obyvateľstvo v jednotlivých dotknutých sídlach, v priamej závislosti od intenzity dopravy, predstavuje predovšetkým cesta I/18 v úsekoch Fričovce – Prešov a Prešov – Lipníky a cesta II/545 v úseku Kapušany - Demjata. Vplyvom peážneho trasovania diaľnice D1 je intenzita dopravy a z toho vyplývajúca hluková záťaž na ceste I/18 v úseku hranica okresu Levoča – Fričovce a ceste I/68 v úseku Prešov – Bretejovce výrazne nižšia. Doprava na najviac zaťažených úsekoch ciest v meste Prešov je zdrojom nadmerného hluku, ktorý môže siahať približne do vzdialenosti 150 – 200 m od cestných komunikácií. Pritom doprava je na existujúcich prieťahoch štátnych ciest na dlhých úsekoch cez zóny bytovej výstavby predovšetkým na Levočskej ulici, uliciach Obrancov mieru a 17. novembra, Sabinovskej ulici a Šafárikovej ulici. Nadmerným hlukom len pozdĺž prieťahu štátnej cesty I/18 (E 50) cez mesto Prešov je v súčasnosti bezprostredne ovplyvnených viac ako 8 000 obyvateľov samotného mesta. V meste Prešov bolo obyvateľstvo na základe výsledkov monitorovania hluku v roku 1998 podľa ekvivalentných hladín hluku z cestnej dopravy atakované hlukom v nasledovnom rozsahu:

Tabuľka 8 *Počet obyvateľov zaťažených hlukom z cestnej dopravy v meste Prešov*

Hladina hluku	% obyvateľov zaťažených hlukom z cestnej dopravy
>55 dB(A)	23,3
>60 dB(A)	15,2
>65 dB(A)	5,5
>70 dB(A)	2,5

/Zdroj: : ŠZÚ SR /

Znečistenie vôd

Významný prítok Hornádu Torysa je v hornej časti čistým tokom. Negatívny vplyv priemyselných a splaškových odpadových vôd mesta Prešov a prítoku Sekčov sa prejavuje v mieste odberu Torysa–Kendice (rkm 49,9), aj keď sa situácia uvedením mechanicko-biologickej ČOV mesta Prešov čiastočne zlepšila. V roku 2007 boli sledované len niektoré organické látky. Podľa NV len jeden z 9 hodnotených ukazovateľov nevyhovuje odporúčaným hodnotám, je to dusitanový dusík. Triedy kvality podľa STN sa pohybujú od I. po IV. triedu kvality, IV. triedu kvality dosahuje fosforečnanový fosfor. V predchádzajúcich rokoch boli do IV. triedy zatriedené ChSKCr, koliformné baktérie a NELUV v rokoch 2006 a 2007 neboli sledované. Prítok Olšava v mieste odberu Olšava - ústie (rkm 0,6) 3 ukazovatele zo 17 hodnotených ukazovateľov nevyhovuje NV, sú to ChSKCr, celkový fosfor a dusitanový dusík. Všetky ukazovatele sa pohybujú od I. až do V. triedy kvality. Do V. triedy kvality je zatriedená ChSKCr, čo je zhoršenie o jednu triedu kvality oproti predchádzajúcemu hodnotenému obdobiu (2005-2006). Do IV. triedy kvality je zatriedený fosforečnanový fosfor a celkový fosfor.

Tabuľka 9 *Významné priemyselné a ostatné zdroje znečistenia povrchových vôd*

Typ VÚ Kód VÚ	NEC	Názov Prevádzky	Názov toku, rkm	Výrobná aktivita	Spôsob čistenia	Množstvo odp. vôd (tis.m³/rok)	CHSK-Cr (t/rok)	RAS (t/rok)	N - celk. (t/rok)	P — celk. (t/rok)
K2S SKH0016	H2290QVQ	Pivovary Topvar, a.s., Veľký Šariš	Torysa 66,0	Výroba nápojov	mechanicko - biologické	522,452	14,3	RL 736,9		1,2
K2S SKH0020	H2400SVA	Kronospan Slovakia, s. r. o. Prešov	Sekčov 6,2	Drevo-výroba	mechanické	149,50	6,4	44,9		
K2S SKH0020	H2920PVA	Solivary, a. s. Prešov	Sekčov 1,7	Výroba soli	mechanické	64,50		RL 103,7		CL_minus 48,8
K2M SKH0046	H2920QVA	Doma, s. r. o., Prešov	Delňa 1,1	Chov zvierat	mechanicko - biologické	15,30	1,0	9,8		

/Zdroj: Plán manažmentu čiastkového povodia Hornádu, MŽP SR 2009/

Bariéry na vodných tokoch

Vodné toky okresu majú prírodný charakter priebehu, či už s výskytom brehovej sprievodnej vegetácie alebo bez nej, avšak vo väčšine prípadoch sú v rámci zastavaných území obcí vodné toky upravované. Najvýraznejšie bariéry na vodných tokoch z hľadiska migrácie ichtyofauny sa v rámci terénneho prieskumu lokalizovali na rieke Torysa a Sekčov v zastavanom území mesta Prešov. Spresnená lokalizácia je znázornená na mape v prílohe Správy o ichtyofaune. Rieka Sekčov je vodný tok s oveľa väčším potenciálom regionálneho biokoridora, ako plní v súčasnom období. Preteká stredom okresu (aj mesta), čo na jednej strane spôsobuje jeho antropizáciu (spevnenie brehov, pravidelná údržba až vyrub sprievodnej zelene,...), ale na druhej strane, pri minimálnych nákladoch a úpravách by mohol slúžiť nielen ako refúgium pre biotu Torysy, ale aj ako samostatný stabilizačný prvok. Migračné bariéry sú buď minimálne, alebo ľahko opraviteľné, údržba brehovej zelene by mohla byt lepšie koordinovaná a ak by sa zakomponoval do rekreačnej sféry sídliska Sekčov, vedľa ktorého preteká, mohol by tvoriť kostru ekologickej stability v tejto často mesta. Teraz je to iba kanál s niekoľkými prahmi, bez sprievodnej drevinnej zelene, čo negatívne ovplyvňuje ich tyocenózy a ďalšiu biotu. Ak by sa urobila náhradná výsadba aspoň na jednom (slnečnom) brehu, dosť by to pomohlo nielen vodnej biote, ale aj vtáctvu a ostatným terestrickým zložkám. Ďalším problémom je rieka Torysa. Pokiaľ vzácne druhy ichtyofauny sa vyskytujú až v úseku pod Prešovom a charakter toku a jeho úpravy v meste ich priamo nepostihujú, ostatné druhy rýb a vodnej bioty sú negatívne ovplyvnené najmä migračnými bariérami v meste. Ide hlavne o dve hate nachádzajúce sa pri Sídlisku III. Ani jedna nie je pre ryby priechodná, na prvej je síce rybochod, ale zjavne nefunkčný, druhá je bez rybochodu. Z hľadiska plnenia funkcie biokoridoru je nevyhnutné ich spriechodniť.

Poškodenie vegetácie

Z hľadiska zdravotného stavu lesov (Atlas krajiny Slovenskej republiky, 2002) na území okresu Prešov plošne prevládajú veľmi slabo poškodené porasty (defoliácia 11 – 20 %) a slabo poškodené porasty (defoliácia 21 – 30%), miestami sa vyskytujú i plochy zdravých porastov (defoliácia 0 – 10 %). V najvyšších polohách pohorí Branisko, Slanské vrchy, Čergov a Čierna hora, severne od mesta Prešov a miestami a ojedinele i na ostatnom území okresu sa vyskytujú plochy stredne poškodených lesných porastov (defoliácia 31 - 40 %) a silne poškodených porastov (defoliácia > 40 %). Z hľadiska zaťaženia lesných drevín (Atlas krajiny Slovenskej republiky, 2002) koeficient zaťaženia ťažkými kovmi KZ sa v tomto katastrálnom území pohybuje v intervale 1,001 – 2,000, v pohoriach Branisko a Čierna hora v intervale 2,001 – 2,5000. Koeficient zaťaženia sírou KS sa pohybuje v intervale 2,001 – 3,000, v pohoriach

Branisko a Čierna hora sú jeho hodnoty > 3. Koeficient zaťaženia ortuťou KHg sa v Slanských vrchoch, Spišsko – šarišskom medzihorí pohybuje v intervale 3,001 – 5,000, vo východnej časti Šarišskej vrchoviny a na Čergove v intervale 3,001 – 7,000, v západnej časti Šarišskej vrchoviny, Čiernej hore, Bachurni a Branisku sú jeho hodnoty > 7. Vo všeobecnosti môžeme povedať, že lesy okresu Prešov sú v relatívne dobrom zdravotnom stave. Hoci je väčšina porastov jednoetážová (absentuje vertikálna štruktúra), ich druhové zloženie v mnohých prípadoch aproximuje s pôvodným zložením (vyšší stupeň prirodzenosti), čo zvyšuje stabilitu lesných ekosystémov. Zdravotný stav sa najmä v posledných dvoch desaťročiach vplyvom úbytku ťažkého priemyslu, hutníctva a zavádzaniu nových, ekologickejších metód výroby výrazne zlepšil. Je však potrebné povedať, že len veľmi malé percento lesov okresu Prešov patrí medzi chránené, väčšina je intenzívne hospodársky využívaná, často s použitím menej vhodných, ale efektívnych metód, čo môže spôsobovať naopak zníženie stability týchto porastov.

Pásma hygienickej ochrany (PHO)

Juhovýchodná a čiastočne i južná časť Šarišskej vrchoviny, vrátane okolia mesta Prešov, je situovaná v ochrannom pásme letiska Prešov – Nižná Šebastová, pričom je potrebné rešpektovať výškové obmedzenia z toho vyplývajúce.

Monokultúry

Pestré zloženie lesných spoločenstiev na území okresu narúša výskyt smrekových monokultúr, vyčlenených na základe zmapovania lesných spoločenstiev. Väčšie plochy smrekových monokultúr sú lokalizované v pohorí Čierna hora pod Roháčkou, v pohorí Branisko v oblasti Homôlka a tesne pod vrcholom Magury. Mimo lesnej krajiny sa plochy monokultúr nachádzajú na území Šarišskej vrchoviny v katastrálnych územiach obcí Víťaz a Štefanovce (Ortáš), výraznejšie plochy sa nachádzajú v katastrálnych územiach Hendrichovce a Bertotovce na severných svahoch Jakubovianskej hory. Menšie rozptýlené enklávy sledujeme v Slanských vrchoch – Tri chotáre, v pohorí Branisko v okolí Zvolenskej i v pohorí Čergov v okolí Hradovej hory.

Výskyt inváznych druhov

V rámci okresu sa mapuje aj výskyt inváznych druhov rastlín. Mapovanie však nie je úplné, preto spomenieme aspoň niektoré lokality výskytu.

Turanec kanadský *(Conyza canadensis)* – severoamerická stredne vysoká rastlina rastie na neúrodných, na živiny chudobných stanovištiach. Uprednostňuje suché piesočnato-hlinité pôdy na poliach, úhoroch, popri cestách, rúbaniskách. V rámci okresu Prešov je jej výskyt lokalizovaný napr. v k.ú. Víťaz, Červenica,

Prešov, Hendrichovce, Medzany.

Ježatec laločnatý (*Echinocystis lobata*) – pôvodom severoamerická popínavá rastlina s plodom štetinatej chlpatej bobule obľubuje brehy vodných tokov, okraje lužných lesov, rumoviština, okolia sídel. Výskyt v rámci okresu Prešov v k.ú. Chabžany, Bretejovce.

Slnečnica hľuznatá *(Helianthus tuberosus)* – topinambur – severoamerická trváca rastlina, rozmnožuje sa jedlými podzemkovými hľuzami. Agresívne sa šíri do prirodzených biotopov, kde potláča pôvodnú vegetáciu. Najčastejšie rastie popri vodných tokoch v pobrežnej nitrofilnej vegetácii. Výskyt bol lokalizovaný najmä okolo toku Torysy v k.ú. obcí ležiacich pri Toryse a to na viacerých miestach v celom úseku od Veľkého Šariša po Seniakovce.

Netýkavka malokvetá *(Impatiens parviflora)* – pôvodom zo severovýchodnej Ázie sa začala šíriť z botanických záhrad aj do prirodzených spoločenstiev. Rozšírená takmer po celom Slovensku. Vyskytuje sa v pobrežnej vegetácii, v krovinách, v podraste lesov, popri cestách, v parkoch, záhradách. Pri mapovaní sa lokalizovala, napr. v k.ú. Fričovce na podhorí Braniska, ďalej v k. ú. Kapušany, Fintice, Prešov, Malý Šariš, Kokošovce, Zlatá Baňa.

Lupina mnoholistá *(Lupinus polyphyllus*) – známa ako vlčí bôb, pochádza zo severnej Ameriky. Pestuje sa ako okrasná trvalka, osídľuje rúbaniská, okraje lesných ciest, z týchto stanovíšť sa potom rozširuje do prirodzených a poloprirodzených spoločenstiev. Lokalizácia výskytu mimo okrasné záhradky v k.ú. Široké, Hendrichovce.

Agát biely *(Robinia pseudacacia)* – pôvodom zo severnej Ameriky. Rastie v lesoch, pozdĺž ciest, alejách, na násypoch, v záhradách, parkoch, na chudobných i výživných pôdach, prevažne suchších. Výskyt dokladovaný z k.ú. Prešov, Malý Šariš, Záhradné, Fintice, Kapušany, Demjata, Chmeľovec.

Javorovec jaseňolistý *(Negundo aceroides)* – druh pochádzajúci zo Severnej Ameriky, obľúbená okrasná drevina, nenáročná na obsah živín v pôde, odolná voči nepriaznivým vplyvom mestského prostredia, šíri sa najmä pozdĺž vodných tokov. Zastúpený je najmä v brehových porastoch a v sprievodnej vegetácii Torysy.

Pohánkovec japonský, pohánkovec český (***Fallopia japonica***, ***Fallopia × bohemica***) - pohánkovec japonský pochádza z východnej Ázie. Je to trváca dvojdomá rastlina s drevnatejúcim podzemkom, ktorý dorastá až do vzdialenosti 20 m od materskej rastliny. Na miestach výskytu vytvára až nepreniknuteľne husté porasty krovitého vzrastu. Vyskytuje sa najmä okolo vodných tokov, ciest, na synantropných stanovištiach. Vyskytuje sa na mnohých miestach najmä pozdĺž Torysy, väčšia populácia je zaznamenaná aj v k. ú. Kokošovce. Pohánkovec český je kríženec medzi pohánkovcom japonským a pohánkovcom sachalínskym.

Bol opísaný ešte v roku 1983, ale pomerne dlho sa nerozlišoval, preto jeho rozšírenie nie je ešte dostatočne zmapované a viaceré lokality pohánkovca japonského vyžadujú preverenie.

Zlatobyľ obrovská, zlatobyľ kanadská *(Solidago gigantea, Solidago canadensis)* - trváce byliny pôvodne zo severnej Ameriky, vyskytujú sa na synantropných stanovištiach, odkiaľ prenikajú do poloprirodzených a prirodzených spoločenstiev. Osídľujú ľahko nevyužívané plochy a plochy človekom vytvorené, ruderalizované. Lokalizácia výskytu v rámci mapovania v k.ú. Lipovce, Fričovce, Hendrichovce, Medzany, Veľký Šariš, Prešov, Žehňa, Tuhrina, Lúčina, Červenica, Mirkovce, Záborské, Varhaňovce, Bretejovce, hojný je výskyt okolo Torysy, Sekčova, Delne.

Syntéza a hodnotenie celkového zaťaženia územia stresovými faktormi

Z hľadiska zaťaženia územia stresovými faktormi (Atlas krajiny Slovenskej republiky 2002) sa na území Košickej kotliny prejavuje **zaťaženie územia prírodno – antropogénnymi faktormi spôsobené kumuláciou antropogénnych stresových faktorov a svahovými procesmi,** na území Šarišskej vrchoviny, Bachurne, Beskydského predhoria, Spišsko – šarišského medzihoria **zaťaženie územia prírodnými stresovými faktormi** spôsobené kumuláciou geodynamických procesov, na území Slanských vrchov **zaťaženie územia prírodnými stresovými faktormi** spôsobené svahovými procesmi, na území Braniska a Čiernej hory **zaťaženie územia antropogénnymi stresovými faktormi** spôsobené znečistením ovzdušia a kontaminovanou pôdou a na území Čergova **zaťaženie územia antropogénnymi stresovými faktormi** spôsobené miernym poškodením lesnej vegetácie**.** Územie Košickej kotliny patrí medzi poloprírodné a poloprírodno - antropogénne areály územného systému stresových faktorov (Atlas krajiny Slovenskej republiky 2002). Z vybraných stresových faktorov dominantnú úlohu zohráva **silné, resp. veľmi silné znečistenie ovzdušia a svahové procesy.** Ostatné územie okresu patrí medzi antropogénne areály územného systému stresových faktorov. Z vybraných stresových faktorov dominantnú úlohu zohrávajú na území Slanských vrchov svahové procesy, na území Beskydského predhoria, Spišsko – šarišského medzihoria a Šarišskej vrchoviny vodná a výmoľová erózia, na území Čergova vodná erózia a svahové procesy, na území Braniska veľmi silné znečistenie ovzdušia a svahové procesy. Stupeň narušenosti pôvodného prírodného prostredia je závislý predovšetkým od stupňa ekonomickej aktivity a s tým súvisiacej intenzity antropických vplyvov. Na základe analýzy socioekonomických pomerov a stavu zložiek životného prostredia na území okresu Prešov **sa takto vymedzené územie vyznačuje predovšetkým silným znečistením ovzdušia v meste Prešov a jeho bezprostrednom okolí, absenciou environmentálne vyhovujúceho spôsobu zneškodňovania odpadových vôd v prevažnej väčšine sídiel a rovnako i negatívnym vplyvom intenzívnej poľnohospodárskej výroby.** Na juhozápadnom okraji na území okresu

Prešov plošne zasahuje Rudniansko – gelnická zaťažená oblasť a väčšinu územia Košickej kotliny vrátane mesta Prešov plošne pokrýva Košicko – prešovská zaťažená oblasť, obe vyčlenené v zmysle environmentálnej regionalizácie SR z roku 1997 a jej aktualizácií z roku 2002 a v roku 2005.

3. *Environmentálne problémy vrátane zdravotných problémov, ktoré sú relevantné z hľadiska strategického dokumentu.*

Predmetom tejto kapitoly je identifikácia výziev, limitov a problémov z vonkajšieho prostredia (jednak v zmysle územia a jednak v zmysle kompetencií a legislatívy-národná úroveň) rozčlenená podľa jednotlivých veľkých skúmaných oblastí strategického dokumentu: sociálno- ekonomická, územno-technická a prírodno-environmentálna. Vonkajšie prostredie sa jednak chápe vo vzťahu k územiu ale aj vo vzťahu k systémových veciam ako napríklad legislatíva na úrovni štátu a pod. Identifikácia najväčších výziev a problémov bola spracovaná na základe výsledkov analytickej časti strategického dokumentu ako aj na základe dotazníkových prieskumov, individuálnych stretnutí a pracovných skupín so zástupcami obcí, mesta Prešov a sociálno-ekonomických partnerov.

Hlavné environmentálne problémy mesta a obcí UMR Prešov priamo súvisia s jeho povinnosťami, ktoré musí vykonávať v zmysle originálnych a prenesených kompetencií. Ide hlavne o problémy s udržiavaním a zveľaďovaním mesta zameraných na ochranu a údržbu existujúcej verejnej zelene, zabránenie ďalšiemu znižovaniu podielu zelených plôch v zastavanom území mesta, ich rozdrobovaniu a zmysluplné riadenie výstavby a využívania územia. Na znečistení ovzdušia sa v rámci územia UMR Prešov podieľajú najmä energetické zdroje priemyselných podnikov, centrálne tepelné zdroje, blokové kotolne, domáce kúreniská, automobilová doprava a prach z ulíc, z nespevnených plôch a poľnohospodárskej pôdy. Uvedené environmentálne problémy sa častokrát premietajú do zdravotných problémov obyvateľstva: zhoršovanie zdravotného stavu stredného veku, rast počtu srdcovo-cievnych chorôb, rast nádorových ochorení tráviaceho traktu, vysoký výskyt alergických ochorení.

Stav životného prostredia PSK je pravidelne aktualizovaný v Správach o stave životného prostredia Slovenskej republiky, ktoré MŽP SR zverejňuje v zmysle zákona č. 17/1992 Zb. o životnom prostredí a zákona č. 205/2004 Z.z. o zhromažďovaní, odovzdávaní a šírení informácií o životnom prostredí a o zmene a doplnení niektorých zákonov. Kvalita ovzdušia je spomedzi všetkých faktorov určujúcich kvalitu životného prostredia obyvateľmi najčastejšie pociťovaná a hodnotená. Preto ho môžeme považovať za jeden z najvýznamnejších faktorov spokojnosti obyvateľstva so životným prostredím.

Územie mesta Prešov a obce Ľubotice patrí k vymedzeným oblastiam s riadením kvality ovzdušia.

Sociálno-ekonomická oblasť

Problémy a výzvy rozvoja

- Prítomnosť obyvateľstva trvalo nebývajúceho v meste spôsobuje, že na území mesta sa nachádza podstatne viac obyvateľstva, ktoré zaťažuje všetky funkčné systémy mesta, zariadenia občianskej vybavenosti, dopravné, komunikačné a inžinierske siete;
- Nesystematické financovanie športu;
- Nejasné pravidlá pre prevádzkovanie prírodných jazier a štrkovísk na kúpanie, veľké množstvo vlastníkov;
- Nevyhovujúci stavebno-technický stav národných kultúrnych pamiatok a ostatných pamiatkových objektov, s tým súvisiace nedostatočné využívanie potenciálu kultúrneho dedičstva;
- Pretrvávajúci nedostatok odborných a obslužných pracovníkov v zariadeniach sociálnych služieb (nedostatok odborných pracovníkov - opatrovateľ/ka, ošetrovateľ/ka) a obslužných pracovníkov;
- Sociálne služby pre ľudí bez domova so zdravotným postihnutím. V praxi je človek bez domova do zariadenia sociálnych služieb prijímaný spravidla ako bezodkladný, pretože nemá zázemie ani rodinu a tým je jeho život a zdravie ohrozené. Po príchode do zariadenia sociálnych služieb nie je schopný (ochotný) sa podriadiť režimu zariadenia, často býva konfliktný, ohrozujúci seba a ostatných, vytvára nevymáhateľnú dlžobu za poskytované služby.

Ďalšie environmentálne problémy vrátane zdravotných problémov

Všeobecné trendy na regionálnej úrovni

- nedostatočná starostlivosť o životné prostredie na všetkých úrovniach ľudskej činnosti;
- nedostatočná a neúčinná integrácia environmentálnych požiadaviek vo všetkých oblastiach ľudskej činnosti;
- nedostatočná integrácia environmentálnych aspektov do ekonomických a sektorových rozhodnutí;
- nedostatočné povedomie širokej verejnosti o ochrane a tvorbe životného prostredia a jeho vplyve na kvalitu života v regióne;
- nedostatočné využívanie miestneho rozvojového potenciálu.

Nepriaznivé trendy v oblasti ochrany prírody a krajiny na území UMR Prešov

- znižovanie biodiverzity, ruderalizácia a synantropizácia prírodného prostredia;

- environmentálne záťaže
- fragmentácia územia, izolácia populácií, vytváranie bariér;
- ovplyvnenie prirodzeného prostredia bioty zmenou abiotických podmienok a vodného režimu;
- zábery poľnohospodárskej pôdy na nepoľnohospodárske pomery;
- nedostatok pozornosti a finančných prostriedkov na údržbu a obnovu krajinného kultúrneho dedičstva.

Nepriaznivé trendy v oblasti ovzdušia a klímy

- produkcia skleníkových plynov a ich vplyv na klímu;
- územie mesta Prešov a obce Ľubotice ako vymedzená oblast riadenia kvality ovzdušia
- faktory ovplyvňujúce kvalitu ovzdušia v rámci UMR Prešov - vysoká intenzita dopravy v území, zdroje vykurovania, energetická náročnosť objektov, verejné osvetlenie
- dopravný systém mesta Prešov je poznamenaný nedostatočnou kapacitou cestnej siete.

4. Environmentálne ciele vrátane zdravotných cieľov zistených na medzinárodnej, národnej a inej úrovni, ktoré sú relevantné z hľadiska strategického dokumentu, ako aj to, ako sa zohľadnili počas prípravy strategického dokumentu.

Pri určovaní environmentálnych cieľov a priorít boli identifikované relevantné medzinárodné, národné a regionálne dokumenty, ktoré podporujú záujmy starostlivosti o životné prostredie alebo podporujú uplatňovanie trvalo udržateľného rozvoja. Medzi také patrí napríklad: Environmentálny akčný program Spoločenstva (Rozhodnutie 600/2002/ES Európskeho parlamentu a Rady z 22. júla 2002), Oznámenie Komisie Rade a Európskemu parlamentu. Tematická stratégia trvalo udržateľného využívania prírodných zdrojov, KOM(2005)670 v konečnom znení, Brusel 21. 12. 2005, Communication from the Commission to the Council and the European Parliament: On the review of the Sustainable Development Strategy – A platform for action. (Obnovená stratégia EÚ pre trvalo udržateľný rozvoj), COM(2005)658 final. Brussels. 14. 12. 2005, Oznámenie Komisie Rade a Európskemu parlamentu. Tematická stratégia pre životné prostredie v mestách, KOM(2005)718 v konečnom znení, Brusel 11. 1. 2006, Oznámenie Komisie. Zastavenie poklesu biodiverzity do r. 2010 – a v nasledujúcich rokoch.

Trvalo udržateľné ekosystémové služby v prospech ľudstva. KOM(2006)216 v konečnom znení, Brusel, 22. 5.2006. Smerom k trvalo udržateľnému rozvoju: Spoločné európske indikátory, technická správa. 2000.

Iniciatíva expertnej skupiny pre mestské životné prostredie generálneho direktoriátu pre životné prostredie, Európska komisia, Smernica Európskeho parlamentu a Rady 2005/.../ES z ...., ktorou sa zriaďuje infraštruktúra priestorových informácií v Európskom spoločenstve (INSPIRE) – návrh, 12064/2/05, Brusel 23. januára 2006, Stratégia EHK OSN pre výchovu a vzdelávanie k trvalo udržateľnému rozvoju, CEP/AC.13/2005/3/Rev.1, 23. 3. 2005, Oznámenie Komisie Rade a Európskemu parlamentu. Politika súdržnosti a mestá: prínos miest a aglomerácií k rastu a zamestnanosti v rámci regiónov, KOM(2006)385 v konečnom znení, Brusel, 13. 7. 2006, Národná stratégia trvalo udržateľného rozvoja SR (schválená uznesením vlády SR č. 978/2001 a uznesením NR SR č. 1989/2002) a Akčný plán trvalo udržateľného rozvoja v SR na r. 2005 – 2010 (schválený uzn. vlády SR č. 574/2005), Návrh aktualizácie Národného akčného plánu osídlenia a bývania v SR (schválený uzn. vlády SR č. 836/2002), Aktualizovaný akčný plán pre implementáciu Národnej stratégie ochrany biodiverzity na Slovensku na roky 2003-2010 (schválený uzn. vlády SR č.1209 zo 6.11.2002), Akčný plán pre životné prostredie a zdravie obyvateľov Slovenskej republiky III (schválené uzn. vlády SR č. 10/2006), Koncepcia vodohospodárskej politiky SR do r. 2015 (schválené uzn. vlády SR č. 117/2006), Koncepcia ochrany prírody a krajiny (schválená uznesením vlády SR č. 471/2006).

Určenie významných environmentálnych cieľov a priorít, vrátane zdravotných cieľov pre územie UMR Prešov

V posudzovanom dokumente boli špecifikované nasledovné priority a ciele, ktoré majú priamy vzťah k životnému prostrediu a zdraviu a zohľadňujú predchádzajúce priority a ciele SR a EÚ:

PRIORITA 1 UDRŽATEĽNÉ A ODOLNÉ PROSTREDIE			
STRATEGICKÝ CIEĽ 1.1		**STRATEGICKÝ CIEĽ 1.2**	
Podporiť dekarbonizáciu, udržateľnosť dopravnej infraštruktúry a energetiky		Zlepšiť stav životného prostredia	
Špecifický cieľ 1.1.1	**Špecifický cieľ 1.1.2**	**Špecifický cieľ 1.2.1**	**Špecifický cieľ 1.2.2**
Vybudovať udržateľný model multimodálnej a ekologickej mobility	Nastaviť systém energeticky efektívneho rozvoja	Koncepčný prístup k ochrane prírody a krajiny, prevencii rizík a adaptácii na nepriaznivé zmeny klímy	Skvalitniť a zefektívniť systém nakladania s odpadom

IV. ZÁKLADNÉ ÚDAJE O PREDPOKLADANÝCH VPLYVOV STRATEGICKÉHO DOKUMENTU VRÁTANE ZDRAVIA

Spoločný program hospodárskeho rozvoja a sociálneho rozvoja skupiny obcí na území udržateľného mestského rozvoja Prešov na obdobie 2023 - 2030 s výhľadom do roku obsahuje široké spektrum návrhov opatrení. Sú členené do troch prioritných oblastí, šiestich strategických cieľov a šestnástich špecifických cieľov.

1. Pravdepodobne významné environmentálne vplyvy na životné prostredie a vplyvy na zdravie (primárne, sekundárne, kumulatívne, synergické, krátkodobé, strednodobé, dlhodobé, trvalé, dočasné, pozitívne aj negatívne).

Požiadavky na vstupy

Niektoré navrhované zámery a opatrenia PHRSR UMR Prešov budú vyžadovať dočasný alebo aj trvalý záber pôdy, a to i v rámci zastavaného územia, poľnohospodárskeho pôdneho fondu, lesného pôdneho fondu, bez záberu plochy prvkov územného systému ekologickej stability.

Navrhované projekty, aktivity a opatrenia uvedené v PHRSR UMR Prešov budú mať aj ďalšie požiadavky na vstupy (napr. na suroviny, energetické zdroje a pracovné sily). Vzhľadom na nízku mieru ich konkretizácie však nie je možné veľkosť týchto vstupov špecifikovať.

Posudzovaný dokument neobsahuje žiadne údaje o nárokoch na priestor, záber poľnohospodárskej alebo inej plochy, na stavebný alebo iný materiál, na energie, pracovné sily a podobne.

Údaje o výstupoch

Vzhľadom na štruktúru navrhovaných opatrení v posudzovanom PHRSR UMR Prešov možno oprávnene predpokladať prevahu pozitívnych výstupov, ktoré vytvoria lepšie podmienky pre ďalší rozvoj územia, posilnia dopravnú infraštruktúru, zlepšia súčasný dopravný systém, znížia rôzne riziká a v konečnom dôsledku posilnia trend vývoja a zavádzania nových, šetrnejších a efektívnejších technológií. Prinesú tak úspory v energetických a materiálových zdrojoch.

Realizáciou navrhovaných opatrení, ktoré si budú vyžadovať intenzívnu stavebnú činnosť (napr. dobudovanie alebo rekonštrukcia dopravných komunikácií, výstavba zariadení environmentálnej infraštruktúry a pod.) môže dôjsť aj k lokálnemu znečisteniu životného prostredia (napr. znečistenie ovzdušia, produkcie odpadových vôd, zvýšenie hlukovej záťaže, terénne úpravy, zmeny vo využívaní krajiny) či už počas ich výstavby alebo prevádzky. Vzhľadom na nízku mieru konkretizácie projektov uvedených v posudzovanom dokumente, nie je možné tieto výstupy podrobnejšie špecifikovať.

Údaje o priamych, nepriamych, synergických a kumulatívnych vplyvoch na životné prostredie a zdravie obyvateľov

Keďže PHRSR UMR Prešov ako celok sleduje ciele zamerané na znižovanie negatívnych vplyvov na životné prostredie a zdravie obyvateľov, zlepšenie stavu životného prostredia v území, posilňovanie ochrany prírody a biodiverzity, znižovanie množstva CO2 v ovzduší vytvorením udržateľného modelu rozvoja dopravnej infraštruktúry a energetiky, zlepšenie dopravnej situácie, zabezpečenie dostupnosti služieb, podmienky pre zdravý životný štýl, využiť vysoký potenciál územia pre rozvoj cestovného ruchu možno oprávnene konštatovať, že pozitívne priame, nepriame, synergické a kumulatívne vplyvy výrazne prevyšujú nad potenciálne negatívnymi. Predpokladané vplyvy a ich miera sa však v tejto etape nedajú presnejšie určiť. Každá navrhovaná činnosť, ktorá podlieha zákonu č. 24/2004 Z. z. o posudzovaní vplyvov na životné prostredie, sa bude posudzovať samostatne v súlade s týmto zákonom.

Predpokladáme, že lokálne môže dôjsť aj k dočasným alebo trvalým negatívnym vplyvom na faunu, flóru a biodiverzitu (napr. pri zvýšení fragmentácie biotopov alebo vytvorením bariérových efektov), verejné zdravie, pôdu, vodu, ovzdušie, horninové prostredie. Navrhované aktivity môžu spôsobiť negatívne vizuálne vplyvy na obraz krajiny, zmenu využívania krajiny, prípadne môžu zvýšiť počet obyvateľov vystavených nadmernému hluku z dopravy.

Vzhľadom na charakter navrhovaných opatrení však predpokladáme, že realizovaním PHRSR UMR Prešov dôjde predovšetkým k významným pozitívnym vplyvom na kvalitu života a zdravotný stav obyvateľov, a to najmä dobudovaním dopravnej infraštruktúry a infraštruktúry životného prostredia i transferom nových technológií.

Ako príklad opatrení, ktoré by mohli pri nevhodnej implementácii viesť k nadmerným a nevhodným vplyvom na životné prostredie a zdravotný stav obyvateľov možno uviesť nasledovné opatrenia (vybrané z posudzovaného dokumentu):

- výstavba siete TEN-T a medzinárodného spojenia s Poľskom (R4)
- budovanie obchvatov obcí a miest
- integrácia verejnej železničnej, autobusovej prepravy a mestskej VOD vrátane cestovných poriadkov
- realizácia integrovaného dopravného systému IDS Východ

- modernizácie ciest II. a III. triedy
- obnova mostov v zlom až havarijnom stave

Realizácia niektorých opatrení môže mať krátkodobo až strednodobo negatívny vplyv na ekonomiku (napríklad uprednostňovanie environmentálne šetrnejších no finančne náročnejších technológií).

Zvlášť potrebné bude priebežné hodnotenie potenciálnych kumulatívnych vplyvov, ktoré by mohli nastať pri časovo alebo priestorovo nevhodnej implementácii opatrení. Rovnako aj vyvolané vplyvy, ktoré sa môžu v špecifických prípadoch pri tom prejaviť.

Potenciálne negatívny vplyv na kvalitu života obyvateľov UMR Prešov môže nastať v prípade nepriaznivého ekonomického vývoja, poklesu disponibilných príjmov jeho obyvateľov i príjmov samosprávnych orgánov, ktoré môžu viesť k nedostatku zdrojov na zabezpečenie ich funkcií. Príliš ambiciózna realizácia v dokumente navrhovaných opatrení na úkor iných funkcií a potrieb môže viesť k nespokojnosti obyvateľstva a k strate politickej podpory.

V.NAVRHOVANÉ OPATRENIA NA PREVENCIU, ELIMINÁCIU, MINIMALIZÁCIU A KOMPENZÁCIU VPLYVOV NA ŽIVOTNÉ PROSTREDIE A ZDRAVIE

1. Opatrenia na odvrátenie, zníženie alebo zmiernenie prípadných významných negatívnych vplyvov na životné prostredie vrátane zdravia, ktoré by mohli vyplynúť z realizácie strategického dokumentu.

Po preštudovaní posudzovaného strategického dokumentu **Spoločný program hospodárskeho rozvoja a sociálneho rozvoja skupiny obcí na území udržateľného mestského rozvoja prešov na obdobie 2023 - 2030 s výhľadom do roku 2035** možno konštatovať, že realizácia navrhnutých opatrení zásadne nenaruší životné prostredie a negatívne neovplyvní zdravie ľudí. Pokiaľ budú plánované aktivity jednotlivo posúdené a schválené podľa platných právnych predpisov, nemalo by prísť k zásadnému poškodeniu životného prostredia a zdravia obyvateľov. Navrhnúť opatrenia na prevenciu, elimináciu, minimalizáciu a kompenzáciu predpokladaných vplyvov na životné prostredie vrátane zdravia je možné v prípade strategických dokumentov len všeobecne.

Pri implementácii a realizácii v posudzovanom dokumente navrhovaných opatrení i pri výbere ich realizačných variantov odporúčame aplikovať nasledovné odporúčania:

- realizovať posudzovanie vplyvov na životné prostredie v súlade so zákonom č. 24/2006 Z. z. tak, aby bola zabezpečená technická a technologická optimalizácia, vhodná lokalizácia, výber najlepších

dostupných technológií, ako aj vyváženosť environmentálnych, sociálnych i ekonomických aspektov, a to aj v prípadoch, kde to príslušný zákon nevyžaduje

- brať do úvahy vplyv navrhovaných opatrení nielen na udržateľný regionálny rozvoj územia UMR Prešov, ale aj ďalšie časti Slovenska vrátane cezhraničných vplyvov na okolité krajiny
- sledovať nielen sociálny a ekonomický prínos aktivity a jej finančnú realizovateľnosť, ale aj mieru ohrozenia životného prostredia i hodnotu vyvolaných environmentálnych vplyvov a opatrení na ich elimináciu
- sledovať vyváženosť environmentálnych, sociálnych a ekonomických vplyvov na lokálnej i regionálnej úrovni s prihliadnutím na cezhraničné vplyvy
- sledovať možnosť dodržiavania štandardných platných technických, technologických, organizačných a bezpečnostných predpisov súvisiacich s navrhovanou aktivitou
- podporiť vzdelávanie v témach, ako je trvalo udržateľné využívanie zdrojov energie, modely trvalo udržateľnej výroby a spotreby, zdravie, zodpovedné občianstvo a pod.
- spolupracovať s rezortom zdravotníctva pri realizácii preventívnych opatrení na zlepšenie kvality ovzdušia i zvýšenie odolnosti populácie tak, aby sa znižovala chorobnosť na respiračné choroby
- podporovať využívanie obnoviteľných zdrojov energie, zmeniť (tam, kde je to efektívne) palivovú základňu energetických zdrojov na výrobu tepla a teplej vody v prospech využívania obnoviteľných zdrojov energie
- podporovať súlad medzi ochranou prírody a krajiny, ochranou pred povodňami a ochranou vôd cez integrovaný manažment krajiny
- spolupracovať s obcami pri starostlivosti o chránené územia, po metodickej i organizačnej stránke im pomáhať pri vyhlasovaní obecných chránených území
- vytvárať podmienky pre dosiahnutie rovnováhy medzi individuálnou a hromadnou dopravou
- pri jednotlivých realizačných projektoch brať zvýšený ohľad na najzraniteľnejších účastníkov dopravy, spolupracovať s obcami pri riešení dopravných problémov na lokálnej i regionálnej úrovni
- vytvárať podmienky pre zlepšenie ekonomických a environmentálnych výkonov rôznych druhov dopravy, v prípade potreby sa podieľať na realizácii opatrení vedúcich k optimalizácii toku cestujúcich a tovarov
- vytvárať podmienky pre zapojenie obcí do výmeny skúseností a osvedčených postupov pri riešení problémov životného prostredia a udržateľného rozvoja
- spolupracovať pri zavádzaní integrovaného environmentálneho riadenia

- podieľať sa na zlepšení informovanosti obyvateľstva o znečistení životného prostredia a nepriaznivých vplyvoch na zdravie
- podporovať inovácie, vedúce k zníženiu intenzity negatívnych vplyvov na životné prostredie, k účinnejšiemu a zodpovednejšiemu využívaniu prírodných zdrojov

VI. DÔVODY PRE VÝBER ZVAŽOVANÝCH ALTERNATÍV A POPIS TOHO, AKO BOLO VYKONANÉ VYHODNOTENIE VRÁTANE ŤAŽKOSTÍ S POSKYTOVANÍM POTREBNÝCH INFORMÁCIÍ, AKO NAPR. TECHNICKÉ NEDOSTATKY ALEBO NEURČITOSTI

Posudzovaný dokument s názvom „**Spoločný program hospodárskeho rozvoja a sociálneho rozvoja skupiny obcí na území udržateľného mestského rozvoja Prešov na obdobie 2023 - 2030 s výhľadom do roku 2035**“ bol spracovaný len v jednom realizačnom variante. Alternatívne návrhy riešenia a realizácie jednotlivých navrhovaných opatrení boli podľa vyjadrenia spracovateľa dokumentu priebežne zapracované do výsledného textu. Pri ich implementácii sa variantné riešenia môžu uplatniť na úrovni konkrétnych projektov. Ďalej sme preto porovnávali len navrhnutý variant vo vzťahu k takzvanému nulovému variantu. Ten chápeme ako stav, ktorý by nastal, ak by sa v posudzovanom dokumente navrhované opatrenia a aktivity nerealizovali. Vychádzame pri tom z predpokladu, že v takom prípade by boli zmeny v intenzite súčasných vplyvov a nimi vyvolaných zmien životného prostredia a zdravia obyvateľov zanedbateľné.

Porovnanie variantov a návrh optimálneho variantu

Tvorba súboru kritérií a určenie ich dôležitosti na výber optimálneho variantu

Výber kritérií použitých pri porovnaní realizačného a nultého variantu bol podmienený druhom, predpokladanou veľkosťou a významnosťou vplyvov a realizovateľnosťou možných opatrení na ich elimináciu, respektíve zmiernenie a ďalšími aspektmi, ako je celková antropogénna záťaž dotknutého územia, zaťaženie obyvateľstva, narušenie ekologických vzťahov ako aj ekonomickými súvislosťami.

Na základe analýzy celého spektra predpokladaných pozitívnych i negatívnych vplyvov, ktoré možno predpokladať pri realizácii PHRSR UMR Prešov boli vybrané nasledovné tri kritériá:

A. Vplyv na prírodné prostredie a prírodné zdroje

B. Vplyv na sídelné prostredie

C. Vplyv na sociálnu a ekonomickú zložku životného prostredia

Porovnanie, výber optimálneho variantu

V tomto kroku bola pre nulový a realizačný variant každému kritériu priradená bodová hodnota. Ich súčet umožnil stanoviť predpokladanú vhodnosť oboch variantov, stanoviť ich poradie a vybrať najvhodnejší. Výsledok hodnotenia je prezentovaný v nasledujúcej tabuľke.

Vzhľadom na skutočnosť, že sa posudzoval len jeden realizačný variant, nebolo potrebné použiť sofistikovanejšie metódy multikriteriálneho hodnotenia.

Výsledok hodnotenia je prezentovaný v nasledujúcej tabuľke. Vzhľadom na skutočnosť, že sa posudzoval len jeden realizačný variant, nebolo potrebné použiť sofistikovanejšie metódy multikriteriálneho hodnotenia.

Tabuľka 10 *Vhodnosť posudzovaných variantov*

Kritérium	**Posudzované varianty**	
	nultý	**realizačný**
Vplyv na prírodné prostredie a prírodné zdroje	0	+ 1
Vplyv na sídelné prostredie	0	+ 3
Vplyv na sociálnu a ekonomickú zložku životného prostredia	0	+ 6
Výsledné hodnotenie	**0**	**+ 10**

/Zdroj: vlastné spracovanie/

Nulový variant je z hľadiska zmeny intenzity vplyvov a následne vyvolaných zmien neutrálny – jednotlivé kritériá majú hodnotu **0**. U realizačného variantu možno predpokladať zmeny intenzity doterajších vplyvov, prípadne aj vyvolanie vplyvov nových – jednotlivé kritériá preto nadobúdajú hodnotu (+ -) 1 až (+ -) 6. Na základe vyššie uvedeného porovnania možno konštatovať, že **ako vhodnejší sa javí realizačný variant**. Suma potenciálnych vplyvov v jeho prípade nadobudla hodnotu **+ 10**.

Ťažkostí s poskytovaním potrebných informácií, technické nedostatky alebo neurčitosti

Vyššie prezentované hodnotenie je výsledkom kvalifikovaného expertného odhadu. Metóda porovnania výberu optimálneho variantu bola vybraná vzhľadom na mieru špecifikácie opatrení a aktivít posudzovaného strategického dokumentu.

Na základe informácií obsiahnutých v posudzovanom dokumente nie je možné jednoznačne špecifikovať

potenciálne negatívne vplyvy na životné prostredie. Pre aktivity, ktoré budú mať v rámci realizácie navrhovaných opatrení investičný charakter platí, ako aj pre všetky ostatné neinvestičné zámery, povinnosť postupovať v súlade so zákonom č. 24/2006 Z. z. o posudzovaní vplyvov na životné prostredie. Pri realizácii investičných opatrení bude uplatňovaný zákon č. 50/1976 Zb. o územnom plánovaní a stavebnom poriadku v aktuálnom znení, ako aj všetky prislúchajúce vykonávacie predpisy.

Vzhľadom na charakter navrhovaných opatrení však oprávnene predpokladáme, že realizovaním PHRSR UMR Prešov dôjde predovšetkým k významným pozitívnym vplyvom na kvalitu života a zdravotný stav obyvateľov.

VII. NÁVRH MONITOROVANIA ENVIRONMENTÁLNYCH VPLYVOV VRÁTANE VPLYVOV NA ZDRAVIE

Monitorovanie

Predstavuje činnosť, ktorá sa systematicky zaoberá zberom, triedením, zoskupením, vyhodnocovaním a ukladaním podstatných informácií pre potreby hodnotenia a kontroly riadených procesov v UMR Prešov. Proces monitorovania vychádza zo štruktúrovaného modelu riadenia na úrovni prioritných oblastí, strategických i špecifických cieľov, a najmä opatrení a aktivít. Monitorovanie a hodnotenie by mali zabezpečovať všetky subjekty zúčastnené na riadení a implementácii PHSR UMR Prešov v rozsahu zadefinovaných úloh a zodpovedností, ako aj subjekty, ktoré čerpajú finančné prostriedky z fondov. Monitorovanie by malo prebiehať dvoma spôsobmi – na základe systému dohodnutých ukazovateľov a na základe špecifických požiadaviek uvedených v pravidlách využívania externých zdrojov financovania, Európskych štrukturálnych a investičných fondov a podobne.

Ciele PHRSR UMR Prešov sa definujú a následne kvantifikujú v procese programovania prostredníctvom sústavy fyzických a finančných ukazovateľov. Pre účely monitorovania vplyvov na životné prostredie je možné tento systém použiť najmä na:

- zabezpečenie zberu štatistických a finančných údajov o realizácií projektov;
- sledovanie monitorovacích ukazovateľov environmentálnych efektov na úrovni jednotlivých opatrení a priorít PHRSR UMR Prešov;
- agregáciu výsledkov monitorovania za účelom vyhodnocovania efektov a efektivity projektov, jednotlivých prioritných osí a Programu ako celku.

Hlavným cieľom monitorovania PHRSR UMR Prešov na roky 2023 až 2030 je pravidelné sledovanie realizácie cieľov, deklarovaných v strategickom dokumente s využitím sústavy merateľných ukazovateľov k jednotlivým špecifickým cieľom a sústavy realizovaných aktivít. Je potrebné, aby sa tak dialo na báze priebežného porovnania jednotlivých dosiahnutých výsledkov a finančných nákladov pri plnení jednotlivých opatrení.

Pre nezávislé nastavenie monitorovania plnenia stanovených cieľov a efektívnosti by mali na zbere, spracovaní údajov, príprave Správy z hodnotenia pre potreby UMR Prešov spolupracovať aj Kooperačná rada UMR Prešov, tematické komisie UMR Prešov a vecne príslušné odborné útvary.

Pravidelné monitorovanie a hodnotenie progresu v napĺňaní PHRSR UMR Prešov bude vykonávané Úradom Prešovského samosprávneho kraja v zmysle zákona o podpore regionálneho rozvoja. Monitorovanie bude zabezpečované každoročne k 31.12. príslušného kalendárneho roka.

Pre proces monitoringu vplyvov na životné prostredie je možné využiť synergické efekty s procesom monitorovania fondov EÚ. Pre účely monitorovania vplyvov na životné prostredie je možné monitorovací systém využiť najmä na:

- zabezpečenie zberu štatistických a finančných údajov o realizácií projektu
- sledovanie monitorovacích ukazovateľov environmentálnych efektov na úrovni jednotlivých opatrení a priorít PHRSR UMR Prešov
- agregáciu výsledkov monitorovania za účelom vyhodnocovania efektov a efektivity projektov, opatrení i Programu ako celku

V Správe z hodnotenia bude vyhodnotené plnenie strategických a špecifických cieľov PHRSR UMR Prešov. Pri vyhodnotení plnenia cieľov sa využijú merateľné ukazovatele s cieľom vyhodnotiť efekt realizovaných aktivít, ktorý bude limitovaný alebo naopak podporený nezávislými okolnosťami. Hodnotenie plnenia cieľov je nevyhnutné pre ďalšie plánovanie a prípadnú úpravu aktivít vo väzbe na možnú aktualizáciu rozvojových dokumentov.

UMR Prešov má za úlohu príslušnému samosprávnemu kraju do 31. mája každoročne zasielať Správu o plnení cieľov a priorít svojho PHRSR a o zabezpečovaní ich súladu s územnoplánovacou dokumentáciou v zmysle písm. b) § 12 zákona č. 539/2008 Z. z. o podpore regionálneho rozvoja v znení neskorších predpisov. Následne každoročne do 30. júna samosprávny kraj spracuje Správu o hodnotení PHRSR samosprávneho kraja.

Na základe uvedeného je potrebné, aby obce dodržali zákonom stanovené termíny a nimi vypracované Správy o plnení cieľov a priorít príslušného spoločného PHRSR UMR Prešov včas zasielali na Úrad

Prešovského samosprávneho kraja.

VIII. PRAVDEPODOBNE VÝZNAMNÉ CEZHRANIČNÉ ENVIRONMENTÁLNE VPLYVY VRÁTANE VPLYVOV NA ZDRAVIE

Vzhľadom na geografickú polohu regiónu PHRSR UMR Prešov svojimi aktivitami nevytvára predpoklady zasahovať do územia susedných štátov.

IX. NETECHNICKÉ ZHRNUTIE POSKYTNUTÝCH INFORMÁCIÍ

Pri posudzovaní vplyvu tohto strategického dokumentu boli zhodnotené jeho predpokladané vplyvy na životné prostredie vrátane zdravia obyvateľstva a navrhnuté opatrenia na odvrátenie, zníženie alebo zmiernenie prípadných významných negatívnych vplyvov, ktoré by mohli vyplynúť z realizácie tohto strategického dokumentu.

Realizáciou PHRSR UMR Prešov možno oprávnene predpokladať prevažujúci pozitívny účinok na kvalitu životného prostredia a skvalitnenie životných podmienok obyvateľov územia. PHRSR UMR Prešov je rámcový dokument, preto je pochopiteľné, že neobsahuje podrobné informácie o spôsobe plánovanej realizácie navrhovaných opatrení. Jednotlivé investičné projekty budú podliehať samostatnému posudzovaniu vplyvov činností na životné prostredie (ak to bude vyplývať z aktuálneho znenia Zákona č. 24/2006 Z. z.).

Vplyvy strategického dokumentu, ktoré bolo možné predpokladať v rámci jeho posudzovania nie sú takého charakteru, aby spôsobili závažný negatívny vplyv na životné prostredie dotknutého územia. Po zohľadnení pripomienok uvedených v kapitole V. tejto Správy o hodnotení nie sú ďalšie prekážky, ktoré by bránili jeho schváleniu.

X.INFORMÁCIA O EKONOMICKEJ NÁROČNOSTI (AK TO CHARAKTER A ROZSAH STRATEGICKÉHO DOKUMENTU UMOŽŇUJE)

Pre stanovenie finančného rámca strategického dokumentu „**Spoločný program hospodárskeho rozvoja a sociálneho rozvoja skupiny obcí na území udržateľného mestského rozvoja Prešov na obdobie 2023 - 2030 s výhľadom do roku 2035**“ sú indikatívne finančné potreby a požiadavky subjektov pôsobiacich

v UMR Prešov, ktoré sú definované aktivitami plánovanými na realizáciu v rokoch 2023 až 2030.

Finančné zabezpečenie aktivít bude realizované formou viaczdrojového finančného zabezpečenia, a to prostredníctvom:

- európske štrukturálne a investičné fondy,
- štátny rozpočet,
- rozpočet mesta a obcí UMR Prešov,
- štátne účelové fondy,
- finančné prostriedky právnických a fyzických osôb,
- ďalšie finančné zdroje, vrátane ďalších zdrojov EÚ.

Mesto Prešov a obce územia UMR Prešov budú zostavovať vlastný akčný aj finančný plán na daný rozpočtový rok s výhľadom na dva roky, priebežne bude monitorovaný, vyhodnocovaný a aktualizovaný. Zámerom je dosiahnuť kompatibilitu s programovými rozpočtami mesta Prešov a samospráv územia UMR Prešov. Finančný plán implementácie PHRSR UMR Prešov identifikuje finančné objemy, charakter (grantové, revolvingové, investičné, neinvestičné aspekty), zdroje a spôsoby financovania projektov (vlastné zdroje, úverové zdroje, verejné financie, súkromné zdroje, grantové schémy, a pod.). SPHRSR UMR Prešov má aktuálne definovaných celkom 164 aktivít a projektov. Viac ako polovica z nich (94 = 57,3%) je zadefinovaných v rámci Priority 1 - Udržateľné a odolné prostredie, pričom až 44 projektov je zameraných na dopravnú infraštruktúru. Finančné požiadavky (finančné zdroje, potrebné na realizáciu rozvojových aktivít a projektov) sú detailne popísané v samostatnej prílohe k strategickému dokumentu s názvom Akčný plán 2030, predstavujú sumu 238,5 mil. €. Z uvedenej čiastky viac ako polovicu tvoria dopravné projekty (128 mil. €), kde sú nevyhnutné aj výrazné intervencie na regionálnej úrovni (cesty II. a III. triedy) a aj na národnej úrovni (rýchlostné cesty, obchvaty a pod.). Z vlastných zdrojov samospráv združených v UMR Prešov bude na realizáciu rozvojových aktivít a projektov každoročne využívaná suma zodpovedajúca daným aktuálnym možnostiam a rozhodnutiam zastupiteľstiev v súlade s Akčným plánom Prešov 2030 a Programovými rozpočtami samospráv.

Zjednodušený pohľad na indikatívny finančný plán UMR Prešov vo vzťahu k plneniu cieľov stratégie PHRSR UMR Prešov, zostavený podľa prioritných oblastí rozvoja, poskytuje tabuľka 11.

Tabuľka 11 *Indikatívny finančný plán stratégie SPHRSR UMR Prešov*

PRIORITA	ŠPECIFICKÝ CIEĽ	FINANČNÁ NÁROČNOSŤ PROJEKTOV				
		Mesto Prešov	Obec Haniska	Obec Ľubotice	Obec Záborské	SPOLU
UDRŽATEĽNÉ A ODOLNÉ PROSTREDIE	ŠC 1.1.1 - Doprava	109 795 828,05 €	3 160 000,00 €	5 737 898,88 €	10 047 000,00 €	**129 230 187,05 €**
	ŠC 1.1.2 - Energetika	12 108 163,61 €	80 000,00 €	1 700 000,00 €	1 200 000,00 €	**15 088 163,61 €**
	ŠC 1.2.1 - Klíma	14 007 799,48 €	2 220 000,00 €	250 000,00 €	3 640 000,00 €	**20 117 799,48 €**
	ŠC 1.2.2 - Odpad	6 512 086,84 €	100 000,00 €	350 000,00 €	50 000,00 €	**7 012 086,84 €**
	SPOLU	**142 423 877,98 €**	**5 560 000,00 €**	**8 037 898,88 €**	**14 937 000,00 €**	**170 958 776,86 €**
SLUŽBY PRE DÔSTOJNÝ ŽIVOT	ŠC 2.1.1 - Vzdelávanie	6 389 593,75 €	300 000,00 €	500 000,00 €	563 980,00 €	**7 753 573,75 €**
	ŠC 2.1.2 - Práca	1 183 489,31 €	250 000,00 €	0,00€	600 000,00 €	**2 033 489,31 €**
	ŠC 2.2.1 - Sociálne a zdravotnícke služby	7 015 610,00 €	0,00€	2 160 000,00 €	1 000 000,00 €	**10 175 610,00 €**
	ŠC 2.2.2 - Šport	30 001 813,34 €	500 000,00 €	1 056 000,00 €	812 000,00 €	**32 369 813,34 €**
	ŠC 2.2.3 - Bezpečnosť	1 435 037,72 €	60 000,00 €	450 000,00 €	270 000,00 €	**2 215 037,72 €**
	SPOLU	**46 025 544,12 €**	**1 110 000,00 €**	**4 166 000,00 €**	**3 245 980,00 €**	**54 547 524,12 €**
STRATEGICKÝ ROZVOJ A DOBRÉ SPRAVOVANIE	ŠC 3.1.1 - Kapacity	2 632 000,00 €	0,00€	0,00€	0,00€	**2 632 000,00 €**
	ŠC 3.1.2 - Digitalizácia	4 750 000,00 €	0,00€	0,00€	0,00€	**4 750 000,00 €**
	ŠC 3.1.3 - Spolupráca	1 800 000,00 €	0,00€	0,00€	0,00€	**1 800 000,00 €**
	ŠC 3.2.1 - Inovácie	0,00€	0,00€	0,00€	0,00€	**0,00€**
	ŠC 3.2.2 - Kultúrny a kreatívny priemysel	500 000,00 €	80 000,00 €	0,00€	0,00€	**580 000,00 €**
	ŠC 3.2.3 - Podnikanie	3 642 254,46 €	0,00€	0,00€	0,00€	**3 642 254,46 €**
	SPOLU	**13 324 254,46 €**	**80 000,00 €**	**0,00€**	**0,00€**	**13 404 254,46 €**
CELKOVÁ FINANČNÁ NÁROČNOŤ PROJEKTOV		**201 773 676,56 €**	**6 750 000,00 €**	**12 203 898,88 €**	**18 182 980,00 €**	**238 910 555,44 €**

/Zdroj: Vlastné spracovanie/

ZOZNAM OBRÁZKOV

Obrázok 1 *Územie udržateľného mestského rozvoja Prešov s vyznačením jadrového územia mesta Prešov* 16
Obrázok 2 *Sídelná štruktúra a poloha územia UMR Prešov v širších vzťahoch územia okresu Prešov*..... 17
Obrázok 3 *Tektonická schéma*..... 27
Obrázok 4 *Geochemické typy hornín okresu Prešov*..... 28
Obrázok 5 *Geomorfologické jednotky okresu Prešov*..... 30
Obrázok 6 *Geomorfologické podmienky okresu Prešov*..... 32
Obrázok 7 *Morfologicko-morfometrické typy reliéfu okresu Prešov*..... 33
Obrázok 8 *Sklonitosť svahov okresu Prešov* 35
Obrázok 9 *Orientácia svahov okresu Prešov* 36
Obrázok 10 *Pôdne typy poľnohospodárskych pôd okresu Prešov* 38
Obrázok 11 Klimatické oblasti okresu Prešov 42
Obrázok 12 *Potenciálna prirodzená vegetácia okresu Prešov* 49

ZOZNAM TABULIEK

Tabuľka 1 Časový harmonogram prípravy a schvaľovania PHRSR Prešov..... 10
Tabuľka 2 Územie okresu Prešov z hľadiska geomorfologických pomerov 29
Tabuľka 3 Charakteristické hydrologické údaje vodných tokov Torysa a Sekčov v meste Prešov..... 39
Tabuľka 4 Územia európskeho významu v okrese Prešov 59
Tabuľka 5 Prehľad chránených druhov flóry okresu Prešov 68
Tabuľka 6 Prehľad chránených druhov fauny okresu Prešov..... 71
Tabuľka 7 Vyhodnotenie znečistenia ovzdušia podľa limitných hodnôt na ochranu ľudského zdravia a limitných hodnôt zvýšených o medzu tolerancie (MT) na monitorovacích staniciach v Prešovskom kraji za rok 2018..... 75
Tabuľka 8 Počet obyvateľov zaťažených hlukom z cestnej dopravy v meste Prešov..... 78
Tabuľka 9 Významné priemyselné a ostatné zdroje znečistenia povrchových vôd 78
Tabuľka 10 Vhodnosť posudzovaných variantov 92
Tabuľka 11 Indikatívny finančný plán stratégie SPHRSR UMR Prešov 96

ZOZNAM POUŽITÝCH ZDROJOV

- Atlas krajiny Slovenskej republiky, 2002, Bratislava: Ministerstvo životného prostredia SR, Banská Bystrica: Slovenská agentúra životného prostredia, 1. vyd., 344 s.
- Čepelák, J., 1980: Živočíšne regióny, 1 : 1 000 000. In: Atlas SSR. VII. Rastlinstvo, živočíšstvo a fenológia. Bratislava: Veda SAV a SÚGK, 1980
- Futák, J., 1982: Fytogeografické členenie. In: Atlas SSR, SAV a SÚGK Bratislava, mapa č. 14, mierka 1:1 000 000
- Malík, P., Švasta, J. 2002: Hlavné hydrogeologické regióny SR, mapa 1 : 1 500 000. In: Atlas krajiny Slovenskej republiky, 2002: Bratislava: Ministerstvo životného prostredia SR, Banská Bystrica: Slovenská agentúra životného prostredia.
- MŽP SR, 2010: Environmentálna regionalizácia SR, 2010
- Národný Emisný Informačný Systém
- Ružičková, H., Halada, Ľ., Jedlička, L., Kalivodová, E. a kol., 1996: Biotopy Slovenska. Ústav krajinnej ekológie SAV, Bratislava
- SAŽP, 2010: Regionálny územný systém ekologickej stability okresu Prešov
- Štatistický úrad SR, SODB, 2011
- www.enviroportal.sk
- stromy.enviroportal.sk
- zbgis.skgeodesy.sk
- www.geology.sk
- www.podnemapy.sk
- www.shmu.sk
- Vyhláška MŽP SR č. 24/2003 Z. z.
- Vyhláška MŽP SR č. 211/2005 Z. z.
- Zákon NR SR č. 543/2002 Z. z. o ochrane prírody a krajiny
- Zákon NR SR č. 364/2004 Z. z. o vodách
- Zákon NR SR č. 24/2006 Z. z. o posudzovaní vplyvov na životné prostredie o zmene a doplnení niektorých zákonov

ZOZNAM SKRATIEK

PHRSR Plán hospodárskeho rozvoja a sociálneho rozvoja

UMR Územie udržateľného mestského rozvoja

SEA Posudzovanie vplyvov strategického dokumentu na životné prostredie

IÚS Integrovaná územná stratégia

MIRRI Ministerstvo investícií, regionálneho rozvoja a informatizácie

MŽP SR Ministerstvo životného prostredia Slovenskej republiky

PSK Prešovský samosprávny kraj

ÚAaS Útvar analýz a stratégií

RÚSES Regionálny územný systém ekologickej stability

CHVÚ Chránené vtáčie územie

MIESTO A DÁTUM VYHOTOVENIA SPRÁVY O HODNOTENÍ STRATEGICKÉHO DOKUMENTU PHRSR UMR PREŠOV NA ROKY 2023 – 2030 S VÝHĽADOM DO ROKU 2030

Prešov, máj/2024

SPRACOVATEĽ SPRÁVY O HODNOTENÍ

Ing. Jozef Bogľarský, PhD.

V Prešove, 20.5.2024 ----------

spracovateľ