SPOLOČNÝ PROGRAM HOSPODÁRSKEHO ROZVOJA A SOCIÁLNEHO ROZVOJA OBCÍ NA ÚZEMÍ UDRŽATEĽNÉHO MESTSKÉHO ROZVOJA PREŠOV NA OBDOBIE ROKOV 2023 - 2030 S VÝHĽADOM DO ROKU 2035

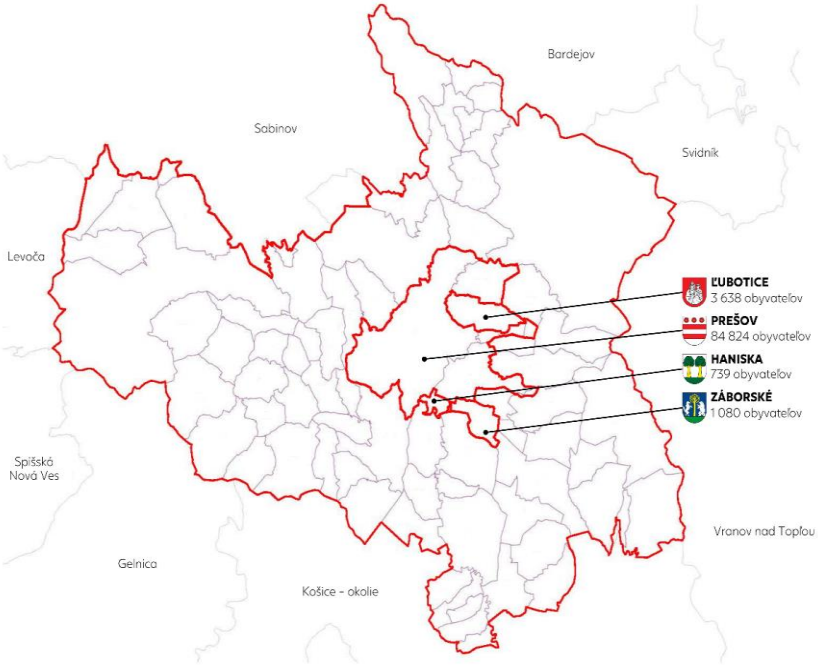

PREŠOV 2030

Názov	Spoločný program hospodárskeho rozvoja a sociálneho rozvoja obcí na území udržateľného mestského rozvoja Prešov na obdobie rokov 2023 - 2030 s výhľadom do roku 2035 (PREŠOV 2030)
Územné vymedzenie:	UMR Prešov
Územný plán obce/VÚC schválený:	áno - ~~nie~~
Dátum schválenia SPHRSR:	12.12.2024
Dátum platnosti:	2023 - 2030
Verzia	1.1
Publikovaný verejne:	2024

[1]Prvé prijaté znenie sa označuje číslom 1.0. V prípade zásadnej zmeny sa ďalšie aktualizované verzie označujú 2.0, 3.0 atď. V prípade malých zmien sa označuje 1.1.

1. ÚVOD ... 4
1.1. IMPULZY PRE SPRACOVANIE NOVÉHO DOKUMENTU ... 5
1.2. ŠTRUKTÚRA DOKUMENTU ... 9
1.3. PROCES TVORBY DOKUMENTU ... 10
1.3.1. RIADIACI TÍM ... 11
1.3.2. PRACOVNÉ SKUPINY ... 12
1.3.3. HARMONOGRAM ... 13
1.4 VSTUPNÁ SPRÁVA ... 13
1. ANALYTICKÁ ČASŤ ... 14
2.1. ÚVODNÉ ZHRNUTIE ... 14
2.2. ZÁKLADNÁ CHARAKTERISTIKA ÚZEMIA UMR PREŠOV ... 15
2.3. ZHODNOTENIE STRATEGICKÝCH DOKUMENTOV NA ÚZEMÍ UMR PREŠOV ... 17
2.4. IDENTIFIKÁCIA VÝZIEV A PROBLÉMOV ... 17
2.5. VÝSTUPY ZO SWOT ANALÝZY ... 22
2. STRATEGICKÁ ČASŤ ... 24
3.1. VÍZIA ROZVOJA A HLAVNÝ CIEĽ ... 24
3.2. PRIORITY, STRATEGICKÉ CIELE, ŠPECIFICKÉ CIELE ... 26
3.3. INTERVENČNÝ RÁMEC ... 28
4. PROGRAMOVÁ ČASŤ ... 29
4.1 PRIORITA 1 - UDRŽATEĽNÉ A ODOLNÉ PROSTREDIE ... 29
4.2 PRIORITA 2 - SLUŽBY PRE DÔSTOJNÝ ŽIVOT ... 33
4.3 PRIORITA 3 - STRATEGICKÝ ROZVOJ A DOBRÉ SPRAVOVANIE ... 39
5. REALIZAČNÁ ČASŤ ... 45
5.1. NÁSTROJE NA IMPLEMENTÁCIU ... 45
5.2. POSTUP PRI IMPLEMENTÁCII ... 45
5.3. SYSTÉM MONITOROVANIA A HODNOTENIA ... 47
5.4. ORGANIZAČNÉ ZABEZPEČENIE REALIZÁCIE STRATÉGIE ... 49
6. FINANČNÁ ČASŤ ... 50
7. RIZIKÁ IMPLEMENTÁCIE A ICH PREVENCIA ... 53
8. ODPORÚČANIA A POŽIADAVKY ... 54
9. PRÍLOHY ... 55
9.1. VYHODNOTENIE STRATEGICKÝCH DOKUMENTOV ... 55
1.1.1. PHSR HANISKA - VYHODNOTENIE ... 55
1.1.2. PHSR OBCE ĽUBOTICE NA OBDOBIE 2015 - 2023 – VYHODNOTENIE ... 56
1.1.3. PROGRAM ROZVOJA MESTA PREŠOV – VYHODNOTENIE ... 58
9.1.4. PHRSR OBCE ZÁBORSKÉ NA ROKY 2015 - 2025 - VYHODNOTENIE ... 60
9.2. ZOZNAM INTERVENCIÍ (AKTIVÍT A PROJEKTOV) NA NAPLNENIE CIEĽOV A VÍZIE STRATÉGIE PREŠOV 2030 S VYUŽITÍM ZDROJOV V RÁMCI PROGRAMU SLOVENSKO ... 63
ZOZNAM OBRÁZKOV, TABULIEK A GRAFOV ... 67
ZOZNAM POUŽITÝCH SKRATIEK ... 68

1. ÚVOD

Spoločný program hospodárskeho rozvoja a sociálneho rozvoja obcí na obdobie rokov 2023 - 2030 s výhľadom do roku 2035 (ďalej len „PREŠOV 2030“) je strednodobým strategickým dokumentom. Spracovaný je v súlade so zákonom č. 539/2008 Z. z. o podpore regionálneho rozvoja pre územie udržateľného mestského rozvoja (ďalej len „UMR Prešov“), ktoré tvorí jadrové mesto Prešov a obce Haniska, Ľubotice a Záborské.

Strategický dokument je nástrojom pre využívanie zdrojov na rozvoj územia, vrátane zdrojov z fondov Európskej únie v aktuálnom programovom období 2021 - 2027. V súlade s článkom 29 Nariadenia Európskeho parlamentu a Rady Európy 2018/0196 (COD), bod (23), strategický dokument **plní aj úlohu Integrovanej územnej stratégie - základného strategického nástroja pre zabezpečenie integrovaného územného rozvoja podporovaného nástrojmi územnej implementácie fondov EÚ, ako sú integrované územné investície.**

Pri tvorbe stratégie, definovaní vízie, prioritných oblastí rozvoja a cieľov boli reflektované najvážnejšie problémy rozvojového územia a jeho obyvateľov s ohľadom aj na možné zdroje finančného plnenia. V dokumente je stanovená **dlhodobá vízia rozvoja územia UMR Prešov**, ktorá **zahŕňa hlavný cieľ.** Za účelom naplnenia vízie boli určené **3 prioritné oblasti rozvoja**, **6 strategických a 15 špecifických cieľov,** ktoré vyplynuli z analýz a prieskumov. Hlavnou intenciou stratégie je prostredníctvom navrhovaných intervencií (konkrétnych aktivít a projektov) nastaviť rozvoj tých ukazovateľov a oblastí, ktoré môžu vytvoriť optimálne podmienky pre dlhodobo udržateľný rozvoj územia, efektívne a ekologické využitie potenciálu a zdrojov územia a jeho zatraktívnenie. Pridanou hodnotu stratégie je uplatňovanie smart konceptu, participácie a budovanie inovačných partnerstiev v území.

Naplnenie stratégie bude prebiehať v súlade s plánom implementácie a akčným plánom, v zmysle navrhnutého časového a finančného harmonogramu, ktorý je flexibilný - umožňuje v čase operatívne reagovať na aktuálny stav (technické, finančné a inštitucionálne možnosti).

Postupným napĺňaním stratégie PREŠOV 2030 sa územie UMR Prešov v horizonte desiatich rokov môže stať miestom pre plnohodnotný život, kde sú využívané moderné a efektívne riešenia s minimalizáciou environmentálnych dopadov v oblasti dopravy a energetickej efektívnosti, kde sa účinne intervenuje do ochrany aj obnovy environmentálneho ekosystému a implementácie adaptačných opatrení, či cirkulárnej ekonomiky. Kvalita života v území bude založená aj na modernom vzdelávaní prepojenom s potrebami na trhu práce, dostupnosti zdravotnej a sociálnej starostlivosti, prijateľnom bývaní a vytvorení vhodných podmienok pre kultúrne vyžitie, šport, či aktívne trávenie voľného času. **UMR Prešov je miestom potenciálu - je ho potrebné systematicky a efektívne premieňať na reálne možnosti pre všetkých.**

1.1. IMPULZY PRE SPRACOVANIE NOVÉHO DOKUMENTU

Mestá a obce v súčasnosti čelia bezprecedentným výzvam súvisiacim nielen s dopadom klimatickej zmeny, celosvetovej pandémie, ale aj s dôsledkami vojnového konfliktu na Ukrajine. Všetky tieto faktory znásobujú efekt dlhodobo neriešených problémov v území. Strategický dokument reflektuje na tieto výzvy územia udržateľného mestského rozvoja Prešov a zároveň zohľadňuje nielen nový inštitucionálny rámec v podobe zastrešenia regionálneho rozvoja pod jedno ministerstvo, novú filozofiu manažovania eurofondov v rámci Programu Slovensko, ale aj prístup k regionálnemu rozvoju v podobe budovania partnerského prístupu a potreby spoločných riešení v rámci územnej spolupráce. S tým súvisí potreba prípravy Integrovanej územnej stratégie, založenej na integrovanom prístupe k strategickému plánovaniu v rámci UMR Prešov.

Legislatívnym východiskom pre spracovanie strategického dokumentu je zákon č. 539/2008 Z. z. o podpore regionálneho rozvoja v znení neskorších predpisov, v zmysle ktorého PREŠOV 2030 predstavuje strednodobý rozvojový dokument, ktorý je vypracovaný podľa záväzných častí územnoplánovacích dokumentácií obcí tvoriacich územie UMR Prešov. Strategický dokument je vypracovaný aj v súlade s cieľmi a prioritami ustanovenými v Programe hospodárskeho rozvoja a sociálneho rozvoja Prešovského samosprávneho kraja na roky 2021 - 2030, na území ktorého sa obce územia UMR Prešov nachádzajú, ako aj v súlade s dlhodobou stratégiou udržateľného rozvoja Slovenskej republiky - Slovensko 2030, ktorá je zároveň základným implementačným dokumentom plnenia národných priorít Agendy 2030 pre udržateľný rozvoj Organizácie spojených národov. Agenda udržateľného rozvoja obsahuje 17 cieľov v oblasti udržateľného rozvoja (viď. obrázok 1), ktoré vyvažujú tri aspekty udržateľného rozvoja - ekonomický, sociálny a environmentálny. Uvedené aspekty adekvátne zohľadňuje aj PREŠOV 2030.

Obrázok 1 Ciele agendy 2030[2]

Strategický dokument PREŠOV 2030 podlieha zároveň Smernici 2001/42/ES Európskeho parlamentu a Rady z 27. júna 2001 o posudzovaní účinkov určitých plánov a programov na životné prostredie a Zákonu č. 24/2006 Z. z. o posudzovaní vplyvov na životné prostredie a o zmene a doplnení niektorých zákonov v znení neskorších predpisov.

Integrovanú územnú stratégiu, ako integrálnu súčasť PREŠOV 2030, definuje článok 29 Všeobecného nariadenia EÚ.[3]

[2] Zdroj: https://agenda2030.statistics.sk/Agenda2030/indikatory-globalna-uroven/

Schematické znázornenie vybraných úloh, ktoré plní PREŠOV 2030 ako základný strednodobý program rozvoja UMR Prešov (viď. obrázok 2).

Obrázok 2 Vybrané úlohy PREŠOV 2030 [4]

V programovom období 2021 - 2027 sa ako základný strategický nástroj pre zabezpečenie integrovaného územného rozvoja využíva koncept Integrovaných územných stratégií, podporovaný nástrojmi územnej implementácie fondov EÚ, ako sú integrované územné investície. **Integrovaná územná stratégia** (ďalej len „IÚS“) **UMR Prešov je vypracovaná v súlade s § 5, písm. d) a § 8a) Zákona č. 539/2008 o podpore regionálneho rozvoja Z.z. v znení jeho neskorších zmien ako spoločný program hospodárskeho a sociálneho rozvoja.** Členovia UMR Prešov sa spoločne prostredníctvom memoranda o spolupráci dohodli, že IÚS bude spracovaná v takom rozsahu, že členovia UMR Prešov nemusia spracovávať osobitný Program hospodárskeho rozvoja a sociálneho rozvoja podľa zákona o podpore regionálneho rozvoja. IÚS je komplexná rozvojová stratégie územia UMR Prešov, integrujúca všetky aspekty rozvoja a rozvojové aktivity v území. IÚS vychádza z analytickej, strategickej a programovej časti strategického dokumentu PREŠOV 2030, vypracovaných podľa zákona o regionálnom rozvoji.

Jedným z kľúčových nástrojov implementácie IÚS prostredníctvom zdrojov fondov EÚ v programovom období 2021 - 2027 sú integrované územné investície (IÚI). IÚI vzniká prepojením minimálne jedného kľúčového projektu s jedným doplnkovým projektom, ktoré sú identifikované v projektovom zásobníku, resp. Akčnom pláne PREŠOV 2030. Podľa článku 30 Všeobecného nariadenia EÚ sú IÚI realizované prostredníctvom podpory z jedného alebo viacerých fondov, jedného alebo viacerých programov alebo z viac ako jednej priority toho istého programu. Projektové aktivity IÚI a ich logická väzba je identifikovaná vo formulári projektového zámeru IÚI. IÚI sú v rámci strategického dokumentu PREŠOV 2030 spracované

[3] Nariadenie Európskeho parlamentu a Rady (EÚ) 2021/1060, ktorým sa stanovujú spoločné ustanovenia o Európskom fonde regionálneho rozvoja, Európskom sociálnom fonde plus, Kohéznom fonde, Fonde na spravodlivú transformáciu a Európskom námornom, rybolovnom a akvakultúrnom fonde a rozpočtové pravidlá pre uvedené fondy, ako aj pre Fond pre azyl, migráciu a integráciu, Fond pre vnútornú bezpečnosť a Nástroj finančnej podpory na riadenie hraníc a vízovú politiku

[4] Vlastné spracovanie

ako podmnožina programovej časti (viď. Príloha 9.2.) s využitím zdrojov v rámci Programu Slovensko, ktorá pokrýva oblasti a typy aktivít oprávnených v Programe Slovensko, v implementačnej kompetencii Kooperačnej rady UMR Prešov.

Strategický dokument PREŠOV 2030 definuje systém priorít, cieľov a k nim prislúchajúcich intervencií (rozvojových aktivít a projektov), ktoré sú územne, vecne a časovo koordinované v rámci integrovaných projektových balíčkov a financované z rôznych zdrojov - fondov EÚ, grantov, dotácií, štátneho rozpočtu, rozpočtu VÚC, rozpočtov samospráv UMR Prešov, súkromných investorov a pod. Integrované projektové balíčky pozostávajú z kľúčových (spravidla investičných) projektov a doplnkových projektov, združených v tematických investičných balíčkoch.

Hlavným účelom integrovaného územného rozvoja je zabezpečiť realizáciu investícií v rámci viacerých špecifických cieľov Programu Slovensko tak, aby bola podporená komplementárnosť aktivít integrovanej investície a boli finančne podporené v rámci integrovaných, nie dopytovo-orientovaných výziev. Prostredníctvom demokratického a participatívneho územného dialógu predstavuje tento koncept odklon od implementačného mechanizmu zameraného na dopytovo orientované výzvy k rozhodovaniu o využití finančných zdrojov na úrovni regiónov. UMR Prešov dosiahne tieto zámery vytvorením kooperujúcich sietí, partnerstiev a prepojením aktivít aktérov verejného, ale aj občianskeho a súkromného sektora pri dosahovaní multiplikačného efektu jednotlivých investícií v území.

Nasledujúca časť ponúka prehľad kľúčových strategických programových dokumentov na národnej, regionálnej a lokálnej úrovni, ktoré boli východiskom pre tvorbu strategického dokumentu PREŠOV 2030.

NÁRODNÁ ÚROVEŇ - kľúčové strategické a koncepčné dokumenty:

- Partnerská dohoda SR na roky 2021 - 2027
- Plán obnovy a odolnosti Slovenskej republiky
- Východiskový návrh priorít SR pre politiku súdržnosti na programové obdobie 2021 - 2027
- Návrh národných priorít implementácie Agendy 2030
- Vízia a stratégia rozvoja Slovenska do roku 2030 - dlhodobá stratégia udržateľného rozvoja Slovenskej republiky - Slovensko 2030 (Národná stratégia regionálneho rozvoja)
- Stratégia hospodárskej politiky SR do roku 2030
- Koncepcia územného rozvoja Slovenska (skrátene KURS)
- Stratégia výskumu a inovácií pre inteligentnú špecializáciu SR 2021 - 2027 (SK RIS3 2021+)
- Koncepcia inteligentného priemyslu pre Slovensko a jej akčný plán
- Podpora inovatívnych riešení v slovenských mestách
- Koncepcia mestského rozvoja SR do roku 2030
- Strategický plán rozvoja dopravy SR do roku 2030 - Fáza II
- Národná stratégia rozvoja cyklistickej dopravy a cykloturistiky v Slovenskej republike
- Stratégia rovnosti, inklúzie a participácie Rómov do roku 2030
- Národný program rozvoja vzdelávania - Kvalitné a dostupné vzdelanie pre Slovensko, NPRVV 2018 - 2027

- Stratégia celoživotného vzdelávania a poradenstva na roky 2021 - 2030
- Strategický rámec starostlivosti o zdravie pre roky 2014 - 2030
- Implementačná stratégia - systém integrovaného poskytovania zdravotnej starostlivosti: Modernizácia zdravotníckej infraštruktúry a zlepšenie dostupnosti kvalitných služieb v primárnej a akútnej lôžkovej zdravotnej starostlivosti

REGIONÁLNA ÚROVEŇ - kľúčové strategické a koncepčné dokumenty:

- Územný plán Prešovského samosprávneho kraja
- Program hospodárskeho rozvoja a sociálneho rozvoja Prešovského samosprávneho kraja na roky 2021 - 2030
- Plán udržateľnej mobility Prešovského samosprávneho kraja
- Kostrová sieť cyklistických trás v Prešovskom samosprávnom kraji
- Stratégia PSK pre mládež na roky 2015 - 2020 s výhľadom do roku 2025
- Koncepcia rozvoja sociálnych služieb v Prešovskom samosprávnom kraji na roky 2020 - 2025
- "Quo vadis, Romale?" - analyticko-strategický dokument o rómskych komunitách na území PSK
- Adaptačná stratégia na zmenu klímy PSK (v návrhu), Prešovský samosprávny kraj
- Nízkouhlíková stratégia organizácií v zriaďovateľskej pôsobnosti PSK (v návrhu), Prešovský samosprávny kraj

LOKÁLNA ÚROVEŇ - kľúčové strategické a koncepčné dokumenty:

Mesto Prešov

- Program rozvoja mesta Prešov na roky 2015 - 2020 s výhľadom do roku 2025[5]
- Stratégia udržateľného rozvoja dopravy mesta Prešov[6]
- Akčný plán udržateľného energetického rozvoja mesta Prešov[7]
- Základná stratégia adaptácie na nepriaznivé dôsledky zmeny klímy na území mesta Prešov[8]
- Komunitný plán sociálnych služieb mesta Prešov na roky 2018 - 2025[9]
- Potenciál mesta Prešov v oblasti Smart City[10]
- Stratégia rozvoja kultúry mesta Prešov 2021 - 2026 (2031)[11]
- Systém energetického manažérstva mesta Prešov
- Program rozvoja bývania mesta Prešov do roku 2030[12]

[5] Uznesením z 11. zasadnutia Mestského zastupiteľstva mesta Prešov č. 403/2023 zo dňa 13.12.2023 bola platnosť Programu rozvoja mesta Prešov na roky 2015 - 2020 s výhľadom do roku 2025 predĺžená do konca kalendárneho roku 2024

[6] https://www.presov.sk/masterplan.html

[7] https://mycovenant.eumayors.eu/storage/web/mc_covenant/documents/8/hMYUncIT_RHCbDUpxSJB43eily7MO7QU.pdf

[8] https://mycovenant.eumayors.eu/storage/web/mc_covenant/documents/18/Guc7PL1wdSWYEX9RLp2g79-AT7ky9Qar.pdf

[9] https://www.presov.sk/komunitny-plan-socialnych-sluzieb-0.html

[10] interný dokument mesta

[11] https://www.presov.sk/download_file_f.php?id=1606842

[12] https://www.presov.sk/download_file_f.php?id=1900828

- Koncepcia rozvoja cestovného ruchu v regióne Dolný Šariš v kontexte širších vzťahov medzi prirodzenými destináciami a vzájomného prepojenia aktivít na území Prešovského samosprávneho kraja
- Detailné hodnotenie zraniteľnosti na dopady zmeny klímy - vlny horúčav[13]
- Bezpečnostná stratégia kybernetickej bezpečnosti, Prešov 2021

Obec Haniska:

- Program hospodárskeho a sociálneho rozvoja obce Haniska 2015 - 2020 s predĺženou platnosťou do roku 2023[14]
- Komunitný plán sociálnych služieb 2018 - 2023[15]
- Nízkouhlíková stratégia obce Haniska na roky 2021 - 2031[16]

Obec Ľubotice:

- Program hospodárskeho a sociálneho rozvoja obce Ľubotice na obdobie 2015 - 2023[17]
- Komunitný plán sociálnych služieb obce Ľubotice na roky 2018 - 2027[18]

Obec Záborské:

- Program hospodárskeho a sociálneho rozvoja obce Záborské na roky 2015 - 2025[19]
- Komunitný plán Záborské (2016 – 2025)[20]
- Program ochrany obce Záborské pred lokálnymi záplavami, zosuvmi, suchom a na ozdravovanie klímy katastra obce[21] (podkladom pre spracovanie dokumentu bol aj dokument Naše Tri prúty,[22] ktorý pre potreby územia vypracovala Miestna akčná skupina MAS Tri prúty).

Mesto Prešov, ako aj obce UMR Prešov majú za účelom systematického riešenia spoločenských výziev a príležitostí v oblasti zvyšovania kvality života, v nadväznosti na nepriaznivé dôsledky klimatických zmien, či rozvojové potreby územia, vypracované viaceré sektorové strategické a koncepčné dokumenty. Vzhľadom k uvedenej skutočnosti boli pri spracovaní strategického dokumentu PREŠOV 2030 využité analytické podklady sektorových strategických a koncepčných dokumentov samospráv UMR Prešov - v zhutnenej podobe sú prezentované iba relevantné dáta, výsledky analýz a formulovaných problémov, ktoré sa následne premietli do reálneho návrhu riešení.

1.2. ŠTRUKTÚRA DOKUMENTU

V súlade s § 8 zákona č. 539/2008 Z. z. o podpore regionálneho rozvoja v znení neskorších predpisov, čl. 29 Nariadenia Európskeho parlamentu a Rady Európskej Únie 2021/1060

[13] interný dokument mesta
[14] https://www.obechaniska.sk/download_file_f.php?id=1174493
[15] https://www.obechaniska.sk/download_file_f.php?id=1174533
[16] https://www.obechaniska.sk/download_file_f.php?id=1496777
[17] https://lubotice.eu/node/232
[18] https://www.obeclubotice.sk/data/page/lubotice.eu/16378/phsr-2015-2023.pdf
[19] interný dokument obce
[20] interný dokument obce
[21] interný dokument obce
[22] MAS Naše TRI PRÚTY, https://mastripruty.sk

a Metodikou tvorby a implementácie PHRSR regiónov, programov rozvoja obcí a skupín obcí s uplatnením princípov udržateľného smart (inteligentného, rozumného) rozvoja je štruktúra strategického dokumentu PREŠOV 2030 nasledovná:

Úvod - impulzy pre spracovanie dokumentu, štruktúra dokumentu, proces tvorby dokumentu, vstupná správa k dokumentu.

1. **Analytické východiská** - trendy a odhad budúceho možného vývoja (zhodnotenie súčasnej situácie, identifikácia vnútorného potenciálu vymedzeného územia a jeho špecifiká, zhodnotenie strategických dokumentov, identifikácia výziev a problémov, SWOT analýza - vyhodnotenie súčasného stavu z rôznych hľadísk a možné alternatívy budúceho vývoja).
2. **Strategická časť a rozvojová stratégia** - vízia územia, priority, strategické a špecifické ciele, intervenčný rámec.
3. **Programová časť** - prioritné oblasti rozvoja územia, prehľad a zameranie konkrétnych cieľov, vrátane navrhovaných intervencií na dosiahnutie požadovaných výstupov.
4. **Realizačná časť** - nástroje implementácie, postup pri implementácii, nástroje na implementáciu stratégie, systém monitorovania a hodnotenia, organizačné zabezpečenie realizácie.
5. **Finančná časť** - návrh finančného plánu, finančná stratégia, plán využitia zdrojov postupne na obdobie n+2 a výhľad (rozdelenie zdrojov podľa priorít, identifikácia predpokladaných finančných zdrojov).
6. **Riziká implementácie a ich prevencia** - identifikácia a zhodnotenie rizík implementácie programu, plán riadenia rizík (opatrenia, zodpovednosti za ich realizáciu).
7. **Odporúčania a požiadavky** - vyplývajúce zo spracovania spoločného strategického dokumentu - vo vzťahu k nadradeným a nižším úrovniam strategického riadenia, pre spolupracujúce subjekty a strategické dokumenty nižšej strategickej úrovne.
8. **Prílohy**

1.3. PROCES TVORBY DOKUMENTU

Mesto Prešov a obce Haniska, Ľubotice a Záborské uzavreli dňa 28. 02. 2021 Memorandum o spolupráci na príprave Integrovanej územnej stratégie územia udržateľného mestského rozvoja Prešov, ktorým deklarovali svoj záujem spoločne postupovať pri riešení územného rozvoja. Súčasne stanovili princípy vzájomnej spolupráce na príprave IÚS UMR Prešov a zaviazali sa zriadiť Kooperačnú radu UMR Prešov, ako koordinačný nástroj funkčného mechanizmu partnerstva, komunikácie a rozhodovania.

V zmysle usmernenia Ministerstva investícií, regionálneho rozvoja a informatizácie SR boli prípustné tri variantné možnosti spracovania Integrovanej územnej stratégie:

1. Zúžená forma IÚS - čerpanie finančných prostriedkov z EŠIF na obdobie 2021 - 2027,
2. Rozšírená forma IÚS - okrem EŠIF aj iné aktivity a zdroje financovania,
3. Spracovanie IÚS ako PHRSR viacerých miest a obcí (potreba schvaľovania PHRSR na úrovni všetkých obecných/mestských zastupiteľstiev).

Partnerské obce UMR Prešov a mesto Prešov sa rozhodli **vypracovať Integrovanú územnú stratégiu ako Spoločný program hospodárskeho rozvoja a sociálneho rozvoja obcí na území udržateľného mestského rozvoja Prešov, ktorý nahrádza samostatné PHRSR obcí.**

1.3.1. RIADIACI TÍM

Spoločný program hospodárskeho rozvoja a sociálneho rozvoja UMR Prešov, vrátane Integrovanej územnej stratégie, vznikal v úzkej spolupráci zástupcov všetkých zúčastnených strán (mesta Prešov a obcí Haniska, Ľubotice a Záborské). V nasledujúcej schéme je uvedený prehľad kľúčových aktérov a rozsah ich zapojenia.

Tabuľka 1 Riadiaci tím

Zadávateľ tvorby PHRSR:	Mesto Prešov
Identifikácia územných samospráv, pre ktoré sa dokument spracováva:	Mesto Prešov Obec Haniska Obec Ľubotice Obec Záborské
Plánovacie obdobie:	2023 - 2030 s výhľadom do roku 2035
Gestor prípravných prác:	Ing. Andrea Turčanová (do 23. 11. 2022) Ing. František Oľha (od 23. 11. 2022)
Koordinátor prípravných prác:	Mgr. Martina Dubecká
Tím pre koordináciu tvorby a implementácie PHRSR:	Ing. Magdaléna Artimová Mgr. Daniela Olejárová, PhD. Ing. Marek Hrubčo Ing. Mária Mularčiková Ing. Janka Nemcová, PhD. JUDr. Veronika Vozárová Mgr. Ján Vysocký PhDr. Andrea Hagovská
Členovia Kooperačnej rady UMR Prešov	**Komora regionálnej samosprávy** RNDr. Zuzana Bednárová, PhD. - PSK RNDr. Bibiána Matľák, PhD./Mgr. Štefan Pavlík - PSK Ing. Ján Pecuch - PSK **Komora miestnej samosprávy** Ing. Andrea Turčanová/Ing. František Oľha - Mesto Prešov Kristína Maliňáková - Obec Záborské Ladislav Šimkovič - Obec Haniska JUDr. Miroslav Makara/Mgr. Nicole Rubisová - Obec Ľubotice **Komora ostatných sociálno-ekonomických partnerov** Ing. Soňa Hatoková - GREEN CUBATOR, n.o. Ing. Ján Ilkovič - Eneco, s.r.o. Viera Štupáková - CYKLOPO PhDr. Peter Valiček - Gréckokatolícka Charita Prešov Ing. Helena Virčíková - Prešovská regionálna komora SOPK Dr. h. c. mult. prof. Ing. Jozef Zajac, CSc.- FVT TUKE

1.3.2. PRACOVNÉ SKUPINY

Príprava a implementácia PHRSR Prešov je založená na **partnerstve aktérov lokálneho a regionálneho rozvoja** s ohľadom na princíp partnerstva podľa §2 písm. g) zákona č. 539/2008 Z. z o podpore regionálneho rozvoja v znení neskorších predpisov a čl. 8 Nariadenia Európskeho parlamentu a Rady Európskej únie 2021/1060.

Participácia socioekonomických partnerov na procese tvorby PHRSR Prešov je predpokladom širokej akceptácie stratégie, nástrojom dosiahnutia konsenzu a podmienkou účasti socioekonomických partnerov na implementácii PHRSR.

V procese tvorby strategického dokumentu bola zabezpečená účasť socioekonomických partnerov v tematických pracovných skupinách, kde boli prerokované rôzne verzie jeho návrhu. Odborníci, aktéri z územia, ako aj zástupcovia rôznych organizácií boli oslovení prostredníctvom verejných vyzvaní na sériu stretnutí organizovaných Mestom Prešov:

- **Prvá fáza** (24. - 26. 11. 2021 - 76 účastníkov, 5 online stretnutí) - návrh analytickej a strategickej časti strategického dokumentu.
- **Druhá fáza** (12/2021 - 10/2022 - 2 celodenné workshopy, séria online konzultácií) - pripomienkovanie analytickej a strategickej časti, definovanie programovej časti, tvorba zásobníka projektov.
- **Tretia fáza** (26. 10. 2022, 14. 12. 2022 – okrúhle stoly) - revízia vízie expertnou skupinou zloženou zo zástupcov MVO, verejného, podnikateľského a akademického sektora.
- **Štvrtá fáza** (12/2022 - 01/2024, séria stretnutí a individuálnych konzultácií) - pripomienkovanie návrhu programovej časti, zostavenie Akčného plánu Prešov 2030 a jeho pripomienkovanie.
- **Záverečná fáza** (marec 2024) - verejné prerokovanie Správy k strategickému dokumentu, vrátane verejného pripomienkovania strategického dokumentu.

Na príprave strategického dokumentu sa podieľali okrem zamestnancov MsÚ aj členovia tematických pracovných skupín (zástupcovia MVO, verejného, podnikateľského a akademického sektora), zadefinovaných vo Vstupnej správe k strategickému dokumentu, konkrétne:

- **Tematická skupina 1 (18 členov)** - výskum, vývoj, MSP a verejná správa
- **Tematická skupina 2 (17 členov)** - sociálne a zdravotné služby, trh práce a školstvo
- **Tematická skupina 3 (20 členov)** - životné prostredie (odpady, energetika, zeleň, klimatické zmeny)
- **Tematická skupina 4 (29 členov)** - technická a dopravná infraštruktúra
- **Tematická skupina 5 (20 členov)** - kultúra, voľný čas, šport a cestovný ruch

Zámerom spracovateľa pri tvorbe strategického dokumentu bolo v čo najväčšej miere aplikovať **princíp participácie**, zároveň však bolo nevyhnutné zohľadniť obmedzené možnosti priamej interakcie v dôsledku pandémie ochorenia COVID - 19, preto bola časť stretnutí realizovaná prostredníctvom online nástrojov.

1.3.3. HARMONOGRAM

Obrázok 3 Časová os procesu tvorby PHRSR [23]

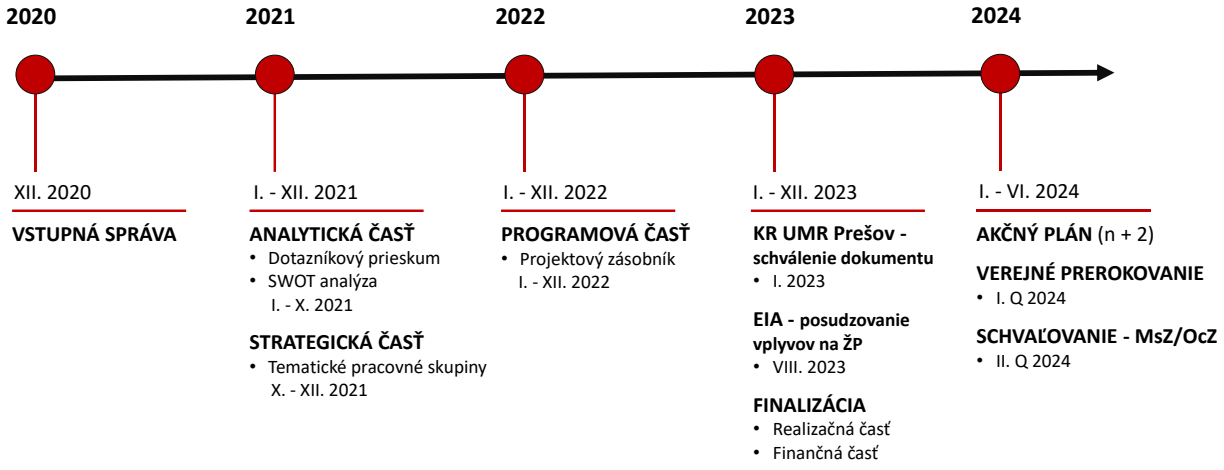

1.4 VSTUPNÁ SPRÁVA

Základným východiskovým materiálom pre rozhodnutie o spracovaní strategického dokumentu PREŠOV 2030 a zároveň zadávacím dokumentom a plánom pre jeho participatívnu tvorbu je **Vstupná správa pre spracovanie strategického dokumentu** s názvom Spoločný program hospodárskeho rozvoja a sociálneho rozvoja obcí na území udržateľného mestského rozvoja Prešov na obdobie rokov 2023 - 2030 s výhľadom do roku 2035.[24] Potreba spracovania Vstupnej správy vyplynula z metodických usmernení Ministerstva investícií, regionálneho rozvoja a informatizácie SR pre tvorbu programových dokumentov pre programové obdobie 2021 - 2027 na regionálnej a miestnej úrovni.[25]

Rámcové vymedzenie obsahového zamerania vstupnej správy:

A. **Základné údaje o PHRSR** (Hlavné ciele, výzvy, problémy a impulzy, na ktoré PHRSR bude reagovať; Predpokladaný obsah dokumentu; Charakter dokumentu; Obsahu dokumentu; Vymedzenie územia; Vecný a časový harmonogram prípravy a schvaľovania dokumentu; Vzťah dokumentu k iným strategickým dokumentom; Orgán kompetentný na prijatie strategického dokumentu)

B. **Základné údaje o predpokladaných vplyvoch implementácie PHRSR** (Predpokladané požiadavky na vstupy/zdroje; Údaje o predpokladaných výstupoch/efektoch; Možné riziká súvisiace s tvorbou a implementáciou PHRSR)

C. **Dotknuté subjekty** (Vymedzenie kľúčových partnerov)

Návrh Vstupnej správy k IÚS UMR Prešov na roky 2021 - 2027 s výhľadom do roku 2030 prijala Kooperačná rada UMR Prešov na svojom 2. zasadnutí dňa 20. 04. 2021 uznesením č. 7/2021.

---

[23] Vlastné spracovanie

[24] https://www.presov.sk/download_file_f.php?id=2013552

[25] https://mirri.gov.sk/wp-content/uploads/2020/01/Metodika_PHRSR2020.pdf , https://mirri.gov.sk/wp-content/uploads/2020/01/Jednotn%C3%BD-metodick%C3%BD_ramec_pre_pr%C3%ADpravu_I%C3%9AS_I%C3%9AI_finalna-verzia_28072022_pdf-1.pdf

1. ANALYTICKÁ ČASŤ

2.1. ÚVODNÉ ZHRNUTIE

Počas uplynulých desiatich rokov klesla populácia v rámci UMR Prešov, primárne v jadrovom meste Prešov o 6 %. Kľúčovým problémom, identifikovaným v území, je dlhodobý odliv ľudí v produktívnom veku. Z Prešova za uplynulých desať rokov odišiel takmer každý tretí občan mesta vo veku 20 - 34 rokov. Zároveň sa výrazne urýchlil proces suburbanizácie - sťahovanie sa ľudí z mesta do vidieckych sídiel v jeho zázemí, spojený primárne so zvýšením kvality bývania. Z kvantitatívneho hľadiska je najvýraznejším príkladom obec Záborské, ktorá v okrese Prešov z hľadiska počtu obyvateľov patrí medzi najrýchlejšie rastúce obce (počet obyvateľov v obci od roku 2014 vzrástol o cca 35%). Proces suburbanizácie prináša množstvo spoločenských, sociálno-priestorových a ekologických dopadov, predovšetkým vo väzbe na dopravu.

Dopravný systém mesta Prešov je poznamenaný nedostatočnou kapacitou cestnej siete, ktorá nevyhovuje rozsahom ani usporiadaním dopytu po doprave. Kapacitné radiálne cesty sú výrazne zaťažené tranzitnou dopravou, najmä nákladnou. Riešené územie je ako jediné na Slovensku obsluhované veľmi intenzívnou mestskou hromadnou dopravou, ktorá zabezpečuje dopravnú obsluhu pre 12 obcí. Hlavným problémom je, že ani cestná sieť, ani infraštruktúra verejnej dopravy sa nerozvíjajú podľa aktuálnych potrieb. S uvedenými faktormi súvisí potreba efektívnych a ekologicky priaznivých riešení v oblasti dopravy tak, aby došlo k optimálnemu prepojeniu vysoko koncentrovaných obytných zón a obcí zázemia mesta s identifikovanými kľúčovými destináciami, vrátane priemyselných parkov.

Na rozdiel od porovnateľných krajských miest vo verejnej sfére pracuje v meste Prešov aj okrese Prešov viac ľudí než v priemysle (bez sektora dopravy). Jednotliví aktéri v území (verejná sféra, súkromný a akademický sektor, mimovládne organizácie) nie sú dostatočne prepojení a systematické úsilie budovať inovačný ekosystém absentuje, čoho dôsledkom je orientácia na produkty s nízkou pridanou hodnotou. Ani po doznení vplyvov pandémie sa miera nezamestnanosti v regióne nevrátila na predpandemickú úroveň a naďalej pretrváva zaostávanie za celoslovenským priemerom o 2 percentá.

Kľúčom k odomknutiu potenciálu územia môže byť kvalitné vzdelávanie (od predprimárneho až po univerzity), či zmysluplné interakcie mimovládneho a súkromného sektora s verejnou sférou, ale aj zmena myslenia v oblasti deinštitucionalizácie a podpora komunitného zmýšľania v sociálnej oblasti, ale aj intervencie do zvyšovania kvality verejných politík a odolnosti demokracie.

Rozvojové územie má z hľadiska životného prostredia vynikajúce predpoklady pre zvýšenie atraktivity. Dobre rozbehnuté budovanie cykloinfraštruktúry, spolu s rozvojom ekologicky priaznivej infraštruktúry verejnej osobnej dopravy, v kombinácii s vynikajúcou dostupnosťou lesoparkov a oddychových zón, môže predstavovať významný faktor rozvoja. Až 90 % osôb, ktoré majú v Prešove a okolí automobil vždy k dispozícii, s ním vykonáva všetky cesty,[26] pričom

[26] Analytická časť Stratégie udržateľného rozvoja dopravy mesta Prešov, 2019 (Masterplan), kapitola 10.4.1 Hlavné problémové body automobilovej dopravy v meste Prešov, str. 355

iba 2 % ľudí v produktívnom veku používa na denné dochádzanie do práce v Prešove bicykel alebo kolobežku.

Ďalšími potenciálnymi zdrojmi rastu rozvojového územia, ktoré boli identifikované, sú kultúra, kreatívny priemysel a cestovný ruch - vzhľadom na potenciál územia priťahovať návštevníkov (a tiež ľudí, ktorí zvažujú návrat), transformovať myslenie a spolu s ním aj životný priestor obyvateľov územia.

2.2. ZÁKLADNÁ CHARAKTERISTIKA ÚZEMIA UMR PREŠOV

Územie udržateľného mestského rozvoja Prešov (ďalej len „UMR Prešov“ alebo „rozvojové územie“) **tvorí mesto Prešov** (katastrálne územie Prešov, Solivar, Šalgovík a Nižná Šebastová) **spoločne s obcami Ľubotice, Haniska a Záborské.** Celkový počet obyvateľov UMR Prešov podľa Sčítania obyvateľov domov a bytov k 01. 01. 2021 je 90 281 obyvateľov.

Obrázok 4 Územie UMR Prešov s vyznačením jadrového územia mesta Prešov[27]

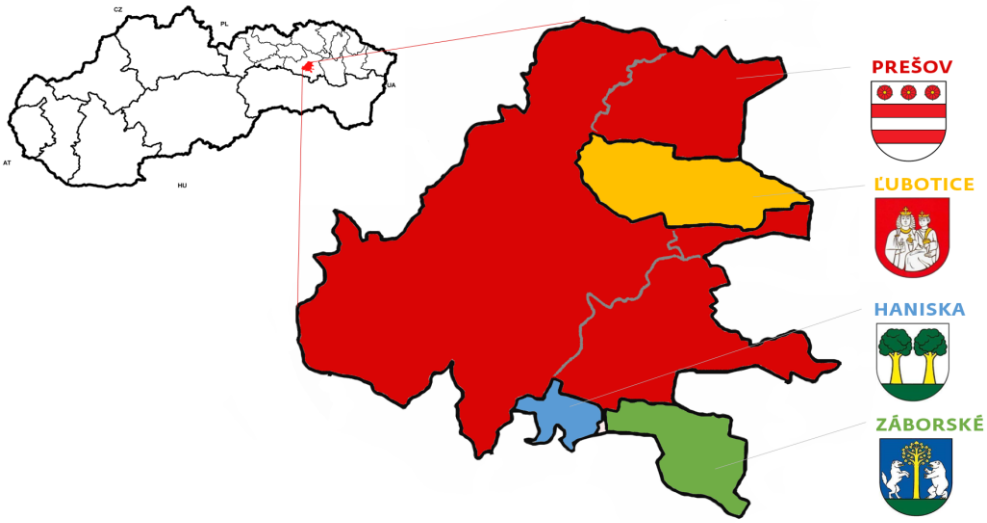

Mesto Prešov s 84 824 obyvateľmi je tretím najväčším mestom Slovenska a spolu s Košicami tvorí na Slovensku druhú najvýznamnejšiu mestskú aglomeráciu s vysokou koncentráciou podnikateľských aktivít, priemyslu, školských a zdravotníckych zariadení aj kultúrnej infraštruktúry. Je administratívnym, kultúrnym a hospodárskym centrom najľudnatejšieho kraja v SR, sídlom Úradu Prešovského samosprávneho kraja a okresným mestom. Leží na sútoku riek Torysa a Sekčov v Košickej kotline, obklopujú ho Slanské vrchy z východu a Šarišská vrchovina zo západu.

Obec Ľubotice s počtom obyvateľov 3 638 je kompaktnou súčasťou UMR Prešov. Kataster obce zo severnej, západnej a južnej časti susedí s katastrálnymi územiami mesta Prešov (k. ú. Nižná Šebastová, k. ú. Prešov, k. ú. Šalgovík). Z východu susedí s katastrálnym územím obce Vyšná Šebastová. Súčasťou obce je taktiež časť Šarišské Lúky, ktorá sa nachádza v západnej časti katastra. V rokoch 1971 až 1990 bola obec Ľubotice súčasťou mesta Prešov, v roku 1991 sa obec

[27] Vlastné spracovanie, mapový podklad https://zbgis.skgeodesy.sk/mkzbgis/sk

osamostatnila. Obec Ľubotice má rozsiahlu priemyselnú zónu, kde pôsobí viac než 100 podnikateľských subjektov.

Južnú časť UMR Prešov dotvárajú obce Haniska so 739 obyvateľmi a Záborské s 1 080 obyvateľmi. Haniska sa nachádza na rozhraní Košickej kotliny a Šarišskej vrchoviny, zväčša na ľavom brehu Torysy. Stredom obce prechádza cesta I/20 na Košice, ako aj železničná trať Kysak - Prešov. Centrum Prešova je od obce vzdialené 5 km a Košice 32 km. Obec Záborské leží v Košickej kotline, v údolí východného prítoku Torysy, v nadmorskej výške okolo 320 m n. m. Vzdialenosť obce od centra Prešova je 7 km a mesta Košice 32 km.

Obce Ľubotice, Záborské a Haniska boli integrované do spoločného rozvojového územia z viacerých dôvodov. Obec Ľubotice (4 % obyvateľov UMR) bola začlenená do UMR nielen vzhľadom na jej geografickú polohu (bezprostredne susedí s uvedenými katastrálnymi oblasťami mesta Prešov zo severu, juhu aj zo západu), ale aj vzhľadom na významné ekonomické, kultúrne a sociálne prepojenia (napríklad tretinu žiakov v Základnej škole v Ľuboticiach tvoria deti občanov s trvalým pobytom na území Prešov[28]). Ľubotice sú obcou s relatívne vysokým nárastom počtu obyvateľstva v rámci UMR za uplynulých 10 rokov,[29] z čoho vyplýva potreba strategických riešení v oblasti nízkouhlíkovej mobility. Spoločným záujmom v rámci UMR je napríklad aj sanácia aktívnych zosuvných území, ktoré sú lokalizované v relatívne husto osídlenej časti územia tvoriacej hranicu mesta Prešov a obce Ľubotice.

Na území obcí Záborské a Haniska (ktoré tvoria spolu 2 % obyvateľov UMR) sa nachádza významná ekonomická báza v podobe dvoch priemyselných parkov. V katastri obce Záborské je situovaný Priemyselný park Záborské (s potenciálom rozšírenia územia priemyselného parku), kde v súčasnosti dochádza za prácou viac ako 1 300 osôb, prevažne z Prešova alebo z blízkeho okolia. Taktiež v obci Haniska sa nachádza Priemyselný Park Haniska - Prešov, ktorý v súčasnosti poskytuje pracovné príležitosti pre približne 1 600 zamestnancov s perspektívou ďalšieho rozvoja v blízkej budúcnosti. Potenciál týchto dvoch oblastí spočíva aj v ich strategickej polohe v smere na Košice - vzdialenosť priemyselného parku Haniska - Prešov od okrajových častí sídliska Ťahanovce v Košiciach predstavuje menej než 30 km (zvyčajne 16 -22 minút po diaľnici D1). Z tohto hľadiska je potrebné preskúmať strategické integrované riešenia v oblasti nízkouhlíkovej mobility nielen v rámci UMR Prešov, ale aj širšie prepojenia na dynamicky sa rozvíjajúci región Košíc. Obec Haniska je zároveň zaujímavým východiskovým bodom do rozsiahleho rekreačného územia lesoparku (Borkút, Malkovská hôrka, Kvašná voda, Cemjata). Na druhej strane obec Záborské s prepojením cez sídlisko Šváby má potenciál pre výstavbu cyklotrás v rámci integrovaných projektov.

Územie UMR Prešov predstavuje špecifický strategicko-plánovací región, kde vzájomné interakcie, spolupráca na tvorbe rozvojovej stratégie a jej následnej implementácii sú predpokladom pre efektívne využitie rozvojového potenciálu a riešenie problémov územia.

[28] Na základe údajov poskytnutých obcou Ľubotice Základnú školu v Ľuboticiach v školskom roku 2022/2023 navštevuje celkom 630 žiakov, z nich 211 má trvalý pobyt na území mesta Prešov.

[29] Nárast počtu obyvateľov v obci Ľubotice za uplynulých 10 rokov dosiahol 18 %, detailné demografické štatistiky sú uvedené v samostatnej prílohe .

2.3. ZHODNOTENIE STRATEGICKÝCH DOKUMENTOV NA ÚZEMÍ UMR PREŠOV

Zahájeniu prípravy nového strategického dokumentu na obdobie rokov 2023 - 2030, ako aj stratégie na nové programové obdobie 2021 - 2027, predchádzalo vyhodnotenie implementácie strategických rozvojových dokumentov mesta Prešov a obcí územia UMR Prešov, spracovaných v súlade so Zákonom NR SR č. 539/2008 Z. z. o podpore regionálneho rozvoja, konkrétne:

- Programu rozvoja mesta Prešov na roky 2015 - 2020 s výhľadom do roku 2025
- Program hospodárskeho a sociálneho rozvoja obce Haniska
- Program hospodárskeho a sociálneho rozvoja obce Ľubotice na obdobie 2015 - 2023
- Program hospodárskeho a sociálneho rozvoja obce Záborské na roky 2015 - 2025

Vyhodnotenie implementácie citovaných stratégií tvorí Prílohu 9.1 tohto dokumentu.

2.4. IDENTIFIKÁCIA VÝZIEV A PROBLÉMOV

Mesto Prešov okrem Programu rozvoja mesta Prešov na roky 2015 - 2020 s výhľadom do roku 2025 spracovalo v posledných rokoch mnohé sektorové strategické a koncepčné dokumenty, ktoré, o. i. vygenerovali relevantné dáta, definovali konkrétne problémy a pomenovali potreby, ktoré je nevyhnutné riešiť. Tieto spoločne s problémami a potrebami obcí Haniska, Ľubotice a Záborské tvorili základné východisko pri definovaní kľúčových problémov UMR Prešov. Rámcovo sú rozčlenené do troch tematických okruhov problémov, na riešenie ktorých sa strategický dokument prioritne zameriava, viď. nižšie uvedený obrázok 5.

Obrázok 5 Okruhy problémov UMR Prešov[30]

[30] Vlastné spracovanie

Okrem vyššie uvedených problémov bolo potrebné pri nastavovaní cieľov rozvoja územia reagovať aj na špecifické problémy, potreby a výzvy územia udržateľného mestského rozvoja:

- nepriaznivý demografický vývoj v jadrovom meste Prešov a súvisiace zmeny v poskytovaní verejných služieb,
- odliv kvalifikovanej pracovnej sily z územia,
- nástup nových technológií a ich využívanie v mestskom prostredí a na úrovni obcí tvoriacich územie udržateľného mestského rozvoja,
- využívanie, obnova a dobudovanie technickej a environmentálnej infraštruktúry,
- udržateľnosť mestského a prímestského prostredia,
- posilnenie odolnosti a reakcie na neočakávané situácie a zmeny prostredia,
- spoločenská zodpovednosť, angažované komunity a participácia.

Hlavné výzvy územia udržateľného mestského rozvoja

- demografické, sociálne a spoločenské výzvy,
- výzvy v oblasti fyzickej infraštruktúry, dopravy a životného prostredia,
- výzvy v hospodárskej oblasti,
- výzvy v oblasti dobrého spravovania územia a využitia medziobecnej a medzisektorovej spolupráce.

Demografické, sociálne a spoločenské výzvy

Jednou z hlavných výziev je starnutie obyvateľstva - narastajúci trend zvyšovania podielu starších osôb na celkovej populácii. Dochádza k poklesu podielu osôb v produktívnom veku a pretrváva odliv kvalifikovanej pracovnej sily. Podľa dostupných štatistických údajov stúpa ekonomické zaťaženie obyvateľstva (cca 19 % - ný podiel obyvateľov v seniorskom veku), je vytváraný tlak na uspokojovanie rastúcej potreby po sociálnych službách a ich ďalšom rozvoji. Bude potrebné klásť dôraz na služby, prostredníctvom ktorých zraniteľné skupiny obyvateľov (seniori, zdravotne znevýhodnení pod.) zotrvajú čo najdlhšie vo svojom prirodzenom prostredí, uspokojiť rastúci dopyt po integrovaných službách zdravotnej a sociálnej starostlivosti, rozširovať a poskytovať vhodné služby pre rozvoj rodinnej politiky i služby, ktoré napomáhajú pri riešení už vzniknutých krízových situácií jednotlivcov, rodín či komunít. Výzvou pre územie je aj riešenie otázky marginalizovaných skupín obyvateľstva.

Vážnou výzvou je negatívna migračná bilancia (za posledné desaťročie 6 % úbytok obyvateľstva v riešenom území UMR Prešov), viditeľný je odliv vzdelanej pracovnej sily. Nevyhnutnosťou sa stáva potreba zatraktívniť územie pre mladých ľudí, ale aj ostatných obyvateľov, zvýšiť nielen kvalitu prostredia územia udržateľného mestského rozvoja, ale aj verejných politík, zmeniť spôsob komunikácie s verejnosťou, podporiť aktivity občianskych iniciatív a spoločensky zodpovedných komunít, miestnu ekonomiku, nové formy celoživotného vzdelávania a nadobúdania nových zručností.

Územie dnes disponuje vzdelávacou infraštruktúrou, výzvou je jej stavebno-technický stav, potrebná modernizácia, rozširovanie kapacít vo väzbe na legislatívne zmeny, ako aj zatraktívnenie vzdelávacieho procesu a posilnenie zastúpenia pomáhajúcich profesií.

Výzvy v oblasti fyzickej infraštruktúry, dopravy a životného prostredia

Kľúčovým problémom územia je dlhodobo doprava. Dopravný systém riešeného územia, primárne mesta Prešov, je poznamenaný nedostatočnou kapacitou cestnej siete, ktorá nevyhovuje rozsahom ani usporiadaním dopytu po doprave. Kapacitné radiálne cesty sú veľmi silne zaťažené tranzitnou dopravou, najmä nákladnou (9 % ciest osobnými automobilmi a až 35 % ciest nákladnými automobilmi - tranzit mestom Prešov). Veľmi vysoký podiel majú vonkajšie cesty do Prešova a z Prešova (35 % ciest osobnými automobilmi a 43 % ciest nákladnými automobilmi). Cestná sieť, infraštruktúra verejnej dopravy, ani komunikácie pre peších a cyklistov sa nerozvíjajú podľa aktuálnych potrieb. Najväčšou výzvou je nevyhnutnosť zmeny prístupu plánovania mobility s dôrazom na aktívne a udržateľné formy prepravy (pešia doprava, cyklodoprava a verejná osobná doprava) prostredníctvom zapájania obyvateľov, zainteresovaných strán a koordinácie medzi dotknutými sektormi. Nevyhnutnosťou je zvýšenie bezpečnosti účastníkov a zvýšenie podielu ekologickej mobility. Cieľom je zlepšenie dostupnosti verejnej osobnej dopravy a zabezpečenie udržateľnej mobility vysokej kvality pre celé mesto Prešov, vrátane zázemia UMR Prešov, vybudovanie moderného, zákaznícky atraktívneho systému verejnej dopravy (integrovaný dopravný systém). Veľkou výzvou, najmä pre Prešov, je potreba riešenia statickej dopravy a s tým súvisiace postupné zavádzanie regulácie parkovania. Systém zvýhodňuje obyvateľov mesta Prešov, sekundárne prispieva k zvýšeniu udržateľnosti trvalo žijúceho obyvateľstva v meste Prešov a zároveň zabezpečeniu komfortu pre návštevníkov mesta a jeho okolia.

Zásadnou výzvou územia udržateľného mestského rozvoja je ochrana prírody a krajiny v záujme dosiahnutia udržateľnej kvality životného prostredia, o.i. aj v súlade so zákonom č. 543/2002 Z. z. o ochrane prírody a krajiny. Územný systém ekologickej stability (ďalej len ÚSES) je v zmysle citovaného zákona dokumentáciou ochrany prírody a krajiny. ÚSES, ako celopriestorová štruktúra navzájom prepojených ekosystémov, ich zložiek a prvkov, je významnou súčasťou zelenej infraštruktúry. Základ tohto systému predstavujú biocentrá, biokoridory a interakčné prvky nadregionálneho, regionálneho alebo miestneho významu. Zámerom stratégie je realizovať v dotknutom území také opatrenia a aktivity, aby ÚSES nebol dotknutý. Zároveň je potrebné zdôrazniť, že v riešenom území sa nachádzajú aj územia európskeho významu, konkrétne: Solivarsko-švábske dúbravy (SKUEV4005), Dolný tok Torysy (SKUEV4007), Lúky pod Hradiskom (SKUEV4097), Lúky pod Dubníkom (SKUEV4101). Z toho do vymedzeného priestoru zasahujú územia európskeho významu Solivarsko-švábske dúbravy (SKUEV4005) a Dolný tok Torysy (SKUEV4007). Dôležitou výzvou stratégie je uchovanie a zabezpečenie vývoja prirodzeného genofondu v riešenom území v rámci jeho prirodzeného priestorového členenia. V záujme ochrany životného prostredia je v riešenom území potrebné venovať primeranú pozornosť výskytu inváznych druhov rastlín v súlade s Vyhláškou Ministerstva životného prostredia SR č. 450/2019 Z. z., ktorá o.i. ustanovuje podmienky a spôsoby odstraňovania inváznych nepôvodných druhov. Je potrebné upriamiť pozornosť aj na nepôvodné druhy, ktoré sa správajú invázne a nie sú uvedené vo vyhláške (turanec kanadský, ježatec laločnatý, slnečnica hľúznatá, netýkavka malokvetá, lupina mnoholistá a agát biely).

Cieľom mesta Prešov, ale aj dotknutých obcí, je v oblasti životného prostredia realizovať účinné a udržateľné opatrenia, zamerané na elimináciu zásahov ohrozujúcich a poškodzujúcich životné prostredie a krajinu, optimalizáciu spotreby energie, koncepčný prístup k adaptácii na nepriaznivé dopady zmeny klímy (vrátane prevencie rizík a ochrany prírody a krajiny), budovanie modrej a zelenej infraštruktúry, revitalizáciu verejných priestranstiev, ich estetizáciu, bezpečnosť a bezbariérovosť.
Odpadové hospodárstvo, primárne spôsob nakladania s odpadmi, má zásadný vplyv na kvalitu životného prostredia. Výraznú pozornosť bude potrebné venovať systémovému nastaveniu nakladania s odpadom, jeho likvidácii a zhodnocovaniu, vrátane zavádzania konceptu cirkulárnej ekonomiky do praxe.
Dobudovanie technickej a environmentálnej infraštruktúry je nevyhnutné aj vo vzťahu k zvýšeniu atraktivity územia pre priame zahraničné investície a investície do územia, využívanie tzv. zanedbaných plôch (green fields) a objektov (brown fields) v území a zároveň zvýšenie podnikateľskej aktivity.

Výzvy v hospodárskej oblasti
Kľúčové výzvy v hospodárskej oblasti súvisia predovšetkým s digitalizáciou, zelenou a obehovou ekonomikou, s technologickými i netechnologickými inováciami, s prepojením výskumu a praxe, so sieťovaním malých podnikov a zavádzaním nových obchodných modelov a marketingu s dôrazom na zelenú a digitálnu transformáciu mestskej ekonomiky.
Na hospodársky rast územia má zásadný vplyv strojárstvo a automobilový priemysel. Cieľom je rozvoj miestnej ekonomiky, založený o. i. aj na podpore mikropodnikov, malého a stredného podnikania so zameraním primárne na vybrané formy cestovného ruchu založené predovšetkým na kultúrnom a kreatívnom priemysle. Výzvou v oblasti vedy a informačných technológii je hlavne sektor vzdelávania, zdravotníctva, kreatívneho priemyslu, ale aj obehového hospodárstva, digitalizácia verejnej správy s využitím potenciálu akademického sektora.

Výzvy v oblasti dobrého spravovania územia
Pretrvávajúcim problémom územného rozvoja je nedostatočné plnenie funkcie koordinačného a integračného nástroja jednotlivých sektorových politík (t. j. lokálne, regionálne, celoštátne úrovne) a rôznych aktérov územného rozvoja (t. j. od občanov, cez podnikateľský sektor, tretí sektor až po verejnú správu). To vedie k nízkej efektívnosti rozhodovacích a implementačných procesov, nízkej flexibilite, neadresnosti opatrení a k formálnosti použitia nástrojov strategického manažmentu a územného rozvoja. Významným problémom sú kapacitné limity (kvalitatívne aj kvantitatívne) personálneho, technického a finančného zabezpečenia tvorby a implementácie politiky územného rozvoja na kľúčových úrovniach. Politika územného rozvoja je neraz implementovaná bez aktívnej účasti kľúčových aktérov lokálnej ekonomiky, obyvateľov, tretieho sektora, vzdelávacích a vedeckých inštitúcií.
Hlavnou výzvou je skvalitnenie verejných politík, a to prostredníctvom využitia skúseností z uplatňovania princípov dobrého spravovania a aktívnej účasti verejnosti na správe vecí verejných - zapájaním verejnosti do rozhodovania, podporou partnerstva a spolupráce,

zdieľaním odborných kapacít, kladením dôrazu na spoločenskú zodpovednosť a aktívne občianstvo. Výsledkom by mali byť verejné služby zamerané na riešenie potrieb obyvateľov a komunít, vytvorený priestor pre vzájomnú diskusiu, spoluúčasť obyvateľov na tvorbe verejných priestorov a verejných politík s cieľom celkového zvýšenia kvality života obyvateľov.

Problémy územia udržateľného mestského rozvoja vo väzbe na spravované územie:

- nevyhovujúci stav verejných budov,
- nedostatočne využívaný inovačný potenciál a prítomnosť akademického sektora,
- nedostatočná integrácia verejných služieb,
- odliv kvalifikovanej pracovnej sily v produktívnom veku,
- nedostatočné odborné kapacity samosprávy,
- nezáujem občanov o veci verejné,
- systematická podpora komunít,
- komplexná starostlivosť o znevýhodnené skupiny obyvateľstva,
- prepojenie strategických dokumentov na mestskej, medziobecnej a subregionálnej úrovni.

2.5. VÝSTUPY ZO SWOT ANALÝZY

SWOT analýza je základným nástrojom na vyhodnotenie súčasného stavu z rôznych hľadísk - analýza vnútorných silných a slabých stránok územia v súvislosti s vonkajšími príležitosťami a hrozbami. **Je východiskom pre formulovanie rozvojovej stratégie územia UMR Prešov, ktorá vznikne ako súlad medzi internými schopnosťami územia a jeho vonkajším prostredím.**

Tabuľka 2 Výstupy zo SWOT analýzy

SILNÉ STRÁNKY Strengths - interné / vnútorné atribúty, ktoré môžu napomôcť k dosiahnutiu cieľa	SLABÉ STRÁNKY Weaknesses - interné / vnútorné atribúty, ktoré sťažujú dosiahnutie cieľa
• **Výhodná geografická poloha územia** (blízkosť Košíc, hôr aj dobrá dostupnosť sever-juh aj východ-západ) • **Relatívna blízkosť a široká dostupnosť rozsiahleho územia mestských lesov** s možnosťami ich rekreačného využitia • **Strategicky významná poloha** z hľadiska dopravného napojenia na hlavné trasy a trate (diaľničné, cestné, železničné, autobusové) • **Existujúca infraštruktúra** pre ďalší rozvoj mestskej, prímestskej a regionálnej dopravy • **Záujem o spoluprácu v území** a o integrovaný rozvoj územia, dobrá dostupnosť mesta a okolitých obcí • **Existujúca rozsiahla sieť cyklotrás** lokálneho, regionálneho aj medzinárodného významu (Eurovelo 11), plánovaná integrácia a vzájomne napojenie (v príprave) • **Diverzifikovaná štruktúra priemyselných podnikov** s vysokým zastúpením malých a stredných podnikov, ako aj väčších firiem, potenciál ďalšieho rozvoja priemyselných parkov (Záborské, Haniska a nových) • **Silné zastúpenie inovačných partnerov z rôznych sektorov** (verejný, súkromný, akademický aj neziskový), výskumnej a inovačnej infraštruktúry a vybudovaný základ pre rozvoj inovačných partnerstiev • **Reálne skúsenosti s generovaním a spracovaním otvorených dát** a pilotné testovanie inteligentných riešení (napr. Šarišský hackathon) • **Široká dostupnosť rôznorodých služieb** pre obyvateľov územia • **Vybudovaná funkčná základná sociálna infraštruktúra**, vrátane siete sociálnych služieb poskytovaných v spolupráci s aktérmi z rôznych sektorov • **Rôznorodosť a atraktivita územia**, existujúca sieť aktérov, potenciál pre rozvoj miestneho cestovného ruchu • **Mesto Prešov ako prirodzené kultúrne, spoločenské a historické centrum Šariša** (pamiatková rezervácia, existujúca kultúrna infraštruktúra, podujatia, aktéri pôsobiaci v kultúrnych a kreatívnych odvetviach - kultúrne dedičstvo, hudba, scénické umenie a architektúra) • **Dlhoročné skúsenosti s realizáciou projektov**, záujem vedenia relevantných samospráv o spoluprácu s miestnymi aktérmi	• **Nevyhovujúca kvalita dopravnej infraštruktúry** (nedostatočná kvalita cestnej siete, chýbajúce parkovacie miesta, zastaraný vozový park, nízka prepojenosť jednotlivých druhov verejnej osobnej dopravy) • **Vysoká miera individuálnej osobnej dopravy**, časté dopravné zápchy a kolízne situácie • **Nevyužitý potenciál cyklodopravy**, chýbajúca integrácia cyklotrás, doplnková infraštruktúra vrátane služieb pre cyklistov • **Nevyhovujúci stav verejných budov, nízka energetická efektívnosť**, nedostatočné využívanie moderných IKT nástrojov a inteligentných riešení pre zefektívnenie ich fungovania • **Vysoké zaťaženie životného prostredia stresovými faktormi** (doprava, znečistenie ovzdušia), zvýšenie rizík spojených s klimatickou zmenou (napr. záplavy, zosuny pôdy) • **Nedobudovaná environmentálna infraštruktúra** pre efektívnu separáciu a spracovanie odpadu • **Nedostatočne podporovaný a využívaný inovačný a kreatívny potenciál** územia a aktérov v ňom • **Nedostatočné využívanie inovatívnych a inteligentných riešení** vo fungovaní samospráv, a organizáciách v ich zriaďovateľskej pôsobnosti • **Nižšia konkurencieschopnosť miestnych podnikateľských subjektov** v rámci širšieho kontextu a nedostatočne využívaný inovačný potenciál • **Štrukturálne problémy s nezamestnanosťou** (nízke vzdelanie špecifických skupín, chýbajúce zručnosti, nedostatok pracovných príležitostí, problematické zamestnávanie zdravotne znevýhodnených), slabé využívanie možností sociálnej ekonomiky pre inklúziu znevýhodnených a zraniteľných skupín obyvateľov • **Zmeny v demografickej štruktúre obyvateľstva** (starnutie populácie, pokles natality, nárast počtu obyvateľov v postproduktívnom veku) • **Odliv pracovnej sily z regiónu** do iných častí Slovenska alebo zahraničia, nedostatok kvalifikovanej a špecializovanej pracovnej sily na lokálnej úrovni • **Nedostatočná kapacita a kvalita infraštruktúry v oblasti vzdelávania** (hlavne MŠ/ZŠ) • **Nedostatočná kapacita sociálnych služieb**, podporných služieb, služieb krízovej intervencie (napr. zariadenia pre seniorov, útulky, krízové bývanie, nízkoprahové centrá, resocializačné zariadenia) • **Nedostatočné možnosti a kapacity pre dostupné nájomné bývanie** pre všetky skupiny obyvateľov,

	vrátane znevýhodnených a zraniteľných skupín • **Nedostatočné využívanie potenciálu územia v oblasti cestovného ruchu** (zastaraná infraštruktúra, nízka kvalita a atraktivita služieb, slabá úroveň marketingovej prezentácie) • **Chýbajúca systematická podpora miestnych aktérov pôsobiacich v kultúrnych a kreatívnych odvetviach** (dáta o KKP, zdieľanie informácií, infraštruktúry, podporné služby, sieťovanie, medzinárodná spolupráca, lokálne financovanie) • **Chýbajúce analytické aj strategické kapacity pre koncepčný rozvoj územia** s využitím moderných analytických nástrojov, chýbajúce projektové a administratívne kapacity pre efektívnu prípravu a realizáciu projektov
PRÍLEŽITOSTI **O**pportunities - externé podmienky, ktoré môžu dopomôcť k dosiahnutiu cieľa	**OHROZENIA** **T**hreats - externé podmienky, ktoré môžu sťažiť dosiahnutie cieľa
• **Potenciál efektívnejšieho využitia geografickej polohy**, blízkosti dvoch riek a biokoridorov vodných tokov • Nové programové obdobie a **možnosť čerpania EÚ zdrojov na rozvojové projekty** v území z Plánu obnovy SR, EŠIF aj ostatných programov EÚ • Blízkosť Košíc fungujúcimi s Prešovom ako "twin cities" poskytuje **príležitosť na integráciu verejných dopravných systémov a výraznejšie využívanie inteligentných riešení** • Príležitosť pre **rozšírenie dopravnej obslužnosti územia** okolitých obcí, vrátane doriešia územia ohrozeného zosuvmi pôdy (vo väzbe na dopravné napojenie) • Politická priorita na úrovni EÚ aj SR súvisiaca so "Zelenou dohodou" vytvára nové možnosti a prináša signifikantné zdroje na **zavádzanie konkrétnych environmentálnych opatrení** do praxe (napr. vďaka podpore alternatívnych pohonov, cykloturistiky, energetickej efektívnosti, či dekarbonizácie) • Legislatíva v oblasti ekosystémovej politiky a **podpora komplexných integrovaných riešení v oblasti ochrany, obnovy a efektívneho využívania prírodných zdrojov, vrátane obnoviteľných zdrojov energie** • Existujúce **zdroje v území z hľadiska inovačného potenciálu** niektorých odvetví (hlavne služieb a cestovného ruchu) ako aj infraštruktúry (napr. brownfields) • Politická **podpora decentralizovaných a integrovaných modelov poskytovania sociálnych a zdravotných služieb** • Možnosť získať dodatočné finančné zdroje na **posilnenie odborných personálnych kapacít** (hlavne administratívnych, projektových a analytických) • **Systémovejšia a aktívnejšia práca s verejnosťou** vo všetkých oblastiach vrátane občianskej participácie • Výraznejšie využitie kultúrneho a kreatívneho potenciálu mesta na **prepájanie kultúry s ostatnými oblasťami spoločenského života,** ako aj pre jeho ekonomické zhodnotenie • **Možnosť využívania nástrojov sociálnej ekonomiky** ako príležitosť na vytvorenie pracovných miest pre znevýhodnené a zraniteľné osoby • **Dopravná a tarifná integrácia** verejnej dopravy	• **Absencia systémových nástrojov** podpory cestovného ruchu na všetkých úrovniach (národnej, regionálnej aj miestnej) • **Nevyužitie potenciálu** v oblastiach kultúrneho a kreatívneho priemyslu, odliv nositeľov kreativity a inovácií do iných lokalít • **Častá migrácia kvalifikovanej pracovnej sily** a následné negatívne demografické zmeny • **Vysoká miera prenesených kompetencií štátu** na samosprávy, nestabilný a nedostatočný model financovania • **Nedostatočné kapacity** v oblasti strategického riadenia, analýz a projektového riadenia • **Vysoká finančná náročnosť, nedostatočná efektívna koordinácia a kooperácia** s ďalšími aktérmi v území (napr. zosuvné územia, krízové situácie, dopravné systémy) • **Zvyšovanie rizika sociálnej izolácie jednotlivcov** a skupín v dôsledku nedostatočnej siete, resp. chýbajúcich sociálnych služieb z dôvodu nedostatočného financovania

2. STRATEGICKÁ ČASŤ

Strategická časť spoločného dokumentu PREŠOV 2030 tvorí strategický rámec aj pre Integrovanú územnú stratégiu územia UMR Prešov. Zameraná je na plánovanie a realizáciu rozvoja UMR Prešov pri zohľadnení nových trendov, výziev a podmienok rozvoja. Zahŕňa:

- **Víziu rozvoja a hlavný cieľ** - predstavu o budúcnosti riešeného územia a pohľad na očakávaný stav v strednodobom horizonte.
- **Priority, strategické ciele, špecifické ciele** - kľúčové oblasti rozvoja, výsledky a výstupy nasmerované na dosiahnutie definovaných priorít a vízie. Sú orientované na strednodobý horizont.

Vízia a hlavný cieľ spoločne s prioritami a strategickými cieľmi predstavujú strategickú časť rozvojovej stratégie. Strategické ciele sú detailnejšie rozpracované formou špecifických cieľov a intervencií (konkrétnych opatrení / rozvojových aktivít / projektov), vrátane ukazovateľov výstupov, výsledkov a dopadu.

3.1. VÍZIA ROZVOJA A HLAVNÝ CIEĽ

Strategický dokument PREŠOV 2030 je spracovaný na obdobie rokov 2023 - 2030, vízia želaného stavu je koncipovaná do roku 2035 a vychádza z predpokladu, že budú využité príležitosti a potenciál rozvoja územia. Definovaná je ako očakávaný stav.

Vízia 2030 predstavuje obraz premeny rozvojového územia v najbližšom desaťročí na ideálne miesto pre život miestnych obyvateľov, kde dochádza k eliminácii odlivu mozgov s opätovnému priťahovaniu nadaných ľudí a súčasne s nimi aj nových nápadov pre rozvoj.

VÍZIA PREŠOV 2030 - SPRÁVNA VOĽBA PRE DÔSTOJNÝ ŽIVOT, SPOLUPRÁCU, PODNIKANIE A POZNÁVANIE.

HLAVNÝ CIEĽ STRATÉGIE PREŠOV 2030

Vytvoriť podmienky pre všestranný rozvoj územia,
využitie dostupných vnútorných a vonkajších potenciálov a zdrojov
na zlepšenie kvality života v území
a napĺňanie potrieb jeho obyvateľov a návštevníkov.

Prešov 2030 spoločne so zázemím okolitých obcí je ideálnym miestom pre život,

- ktorého **motorom sú vzdelaní ľudia**, čo predpokladá vznik a formovanie kvalitných vzdelávacích inštitúcií a ich prepojenie na podnikateľské prostredie a trh práce v rozvojom území;
- ktoré **ponúka vysokokvalitné a konkurencieschopné stredné školy a fakulty** technického a humanitného zamerania, previazané na súkromný sektor a vo väzbe na súkromný sektor pôsobia ako lokálne motory ekonomického rastu v intenciách priemyslu 4.0.;

- ktorého **konkurenčná výhoda vychádza z dostupnosti kvalifikovanej pracovnej sily a z inovácií,** čo pomáha eliminovať odliv ekonomicky aktívneho obyvateľstva s vyšším vzdelaním;
- ktorého **atraktivita je v sile funkčných lokálnych komunít**, ktoré spolu s dostupným bývaním, kvalitnými službami a jedinečným kultúrnym zázemím vytvárajú celistvý ekosystém pre dobrý život so solídnym ekonomickým základom a ľahko dostupným kultúrno-spoločenským a športovým vyžitím jednotlivcov či rodín;
- ktoré systematicky prijíma a **realizuje opatrenia pre zdravšie a kvalitnejšie životné prostredie, chránené pred negatívnymi vplyvmi zmeny klímy;**
- ktoré **vychováva občanov k ochrane životného prostredia**;
- ktoré **ponúka odlišné tempo života**, malé vzdialenosti, inteligentne riadenú dopravu, príjemné prostredie pre život, kultúrne príležitosti pre mladých mestských profesionálov a rádovo vyššiu kvalitu života;
- ktoré tvorí spolu s Košicami úzko prepojené súmestie a **je konkurencieschopnou alternatívou** k životu v excentricky umiestnenej Bratislave;
- kde ľudia v mestskom prostredí a obciach spolu tvoria spoločné rozvojové územie, prijímajú spoluzodpovednosť za susedstvá, v ktorých žijú **s pozitívnym dopadom na medzigeneračnú solidaritu, participáciu a demokratické zmýšľanie;**
- kde **marginalizované a znevýhodnené skupiny obyvateľov sú vnímané ako dosiaľ neobjavený ľudský kapitál** pre ďalší rozvoj;
- ktoré **je uznávaným lídrom v regióne východného Slovenska**, prístupné pre investorov a firmy, s excelentným vzdelávaním, ktoré reflektuje potreby mestskej ekonomiky;
- ktoré vytvára **potenciál pre rozvoj kultúrneho a kreatívneho priemyslu** a podporujú silné kultúrne zázemie rozvojového územia;
- kde univerzity, firmy, mestá a obce rozvojového územia v spolupráci s mimovládnym sektorom **systematicky vytvárajú inovačný ekosystém**;
- ktoré **strategicky a efektívne využíva prínosy digitalizácie a nových technológii** na zvyšovanie dostupnosti infraštruktúry a služieb;
- ktoré **uplatňuje inovatívny prístup k filozofii spravovania územia -** samospráva sa stáva koordinátorom, resp. katalyzátorom rozvoja územia podporou aktívnych komunít;
- ktoré **sieťuje aktívnych obyvateľov, ktorí tu žijú, ale aj tých, ktorí sa rozhodli odísť**, ale majú k svojmu mestu alebo obci vzťah;
- ktoré **vďaka inováciám a zapojeniu nových technológií plní potreby svojich občanov** všetkých generácií v celej šírke ľudskej skúsenosti.

Vízia rozvojového územia vychádza z vízie mesta Prešov a obcí tvoriacich územie udržateľného mestského rozvoja. Bola spracovaná s dôrazom na integráciu a súdržnosť spoločne vytvoreného územia. Vytvorená bola participatívne za účasti zástupcov mesta Prešov a zástupcov obcí Haniska, Ľubotice a Záborské v spolupráci s členmi tematických pracovných skupín. Pre dosiahnutie vízie rozvojového územia - UMR Prešov boli definované 3 prioritné oblasti rozvoja, ktoré reprezentujú želané zmeny v kvalite života v rozvojovom území.

PRIORITA 1 - UDRŽATEĽNÉ A ODOLNÉ PROSTREDIE

PRIORITA 2 - SLUŽBY PRE DÔSTOJNÝ ŽIVOT

PRIORITA 3 - STRATEGICKÝ ROZVOJ A DOBRÉ SPRAVOVANIE

Prioritné oblasti rozvoja UMR Prešov sú rozpracované na úroveň strategických a špecifických cieľov. Každému špecifickému cieľu je priradený zoznam hlavných smerov intervencií na ich naplnenie.

3.2. PRIORITY, STRATEGICKÉ CIELE, ŠPECIFICKÉ CIELE

Strategický plán rozvoja územia korešponduje s prioritnými oblasťami rozvoja územia - rozdelený je do troch tematických častí. Pre naplnenie dlhodobej vízie rozvoja územia UMR Prešov bola stanovená štruktúra cieľov zahŕňajúca:

- **3 hlavné ciele** zodpovedajúce prioritným oblastiam rozvoja
- **6 strategických cieľov**
- **15 špecifických cieľov**

Schematický pohľad na štruktúru cieľov z kvantitatívneho hľadiska vo väzbe na prioritné oblasti rozvoja poskytuje obrázok 6. Špecifické ciele zodpovedajú tematickým / sektorovým sekciám, ktoré sú rozpracované na úroveň navrhovaných intervencií (rozvojových aktivít a projektov).

Obrázok 6 Prioritné oblasti rozvoja a stanovené ciele[31]

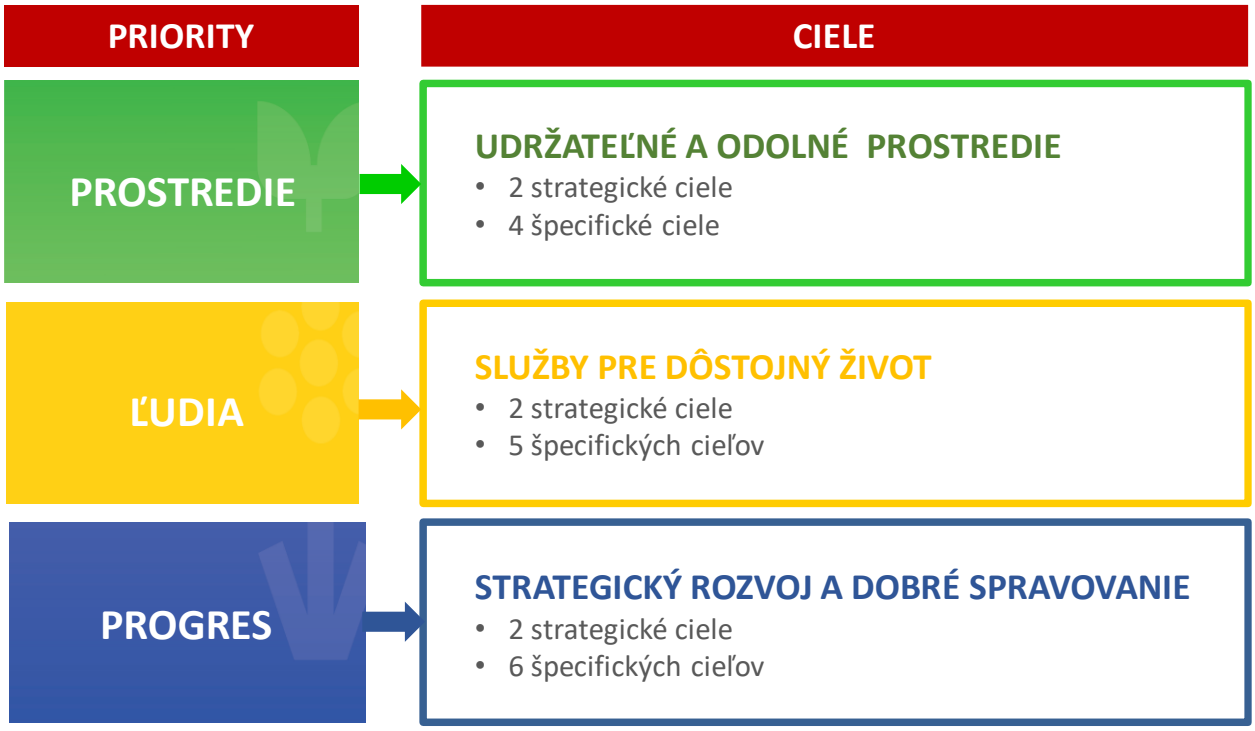

Súbor cieľov vytvára rámec pre rozvoj územia, pre vytváranie funkčných väzieb medzi jadrovým mestom Prešov a jeho okolím, pre posilnenie jednotlivých funkcií a vzťahov s okolitými mestskými oblasťami (primárne Košice) a susediacimi územiami (strategicko-plánovací región Šariš). **Dosiahnutie hlavného cieľa bude vyžadovať cielené a v mnohých prípadoch dlhodobé intervencie (opatrenia/aktivity/projekty), vedúce k využitiu rastového potenciálu územia UMR Prešov.**

[31] Vlastné spracovanie

Prioritné rozvojové oblasti stratégie PREŠOV 2030, strategické ciele a špecifické ciele, ich štruktúru a vzájomné prepojenie schematicky popisuje nižšie uvedený obrázok 7.

Obrázok 7 *Hierarchická štruktúra priorít a cieľov stratégie PREŠOV 2030*[32]

PREVIAZANOSŤ PRIORÍT A CIEĽOV NA SEKTOROVÉ POLITIKY

PRIORITA 1 UDRŽATEĽNÉ A ODOLNÉ PROSTREDIE				PRIORITA 2 SLUŽBY PRE DÔSTOJNÝ ŽIVOT					PRIORITA 3 STRATEGICKÝ ROZVOJ A DOBRÉ SPRAVOVANIE					
PRIORITA 1 UDRŽATEĽNÉ A ODOLNÉ PROSTREDIE				PRIORITA 2 SLUŽBY PRE DÔSTOJNÝ ŽIVOT					PRIORITA 3 STRATEGICKÝ ROZVOJ A DOBRÉ SPRAVOVANIE					
STRATEGICKÝ CIEĽ 1.1		STRATEGICKÝ CIEĽ 1.2		STRATEGICKÝ CIEĽ 2.1		STRATEGICKÝ CIEĽ 2.2			STRATEGICKÝ CIEĽ 3.1			STRATEGICKÝ CIEĽ 3.2		
Podporiť dekarbonizáciu, udržateľnosť dopravnej infraštruktúry a energetiky		Zlepšiť stav životného prostredia		Zabezpečiť kvalitné vzdelávanie pre potreby trhu práce		Zabezpečiť dostupnú infraštruktúru, kvalitu služieb a podmienky pre vyššiu kvalitu života			Zlepšiť systém strategického plánovania, riadenia a spolupráce			Využiť potenciál územia pre ekonomický rozvoj		
Špecifický cieľ 1.1.1	Špecifický cieľ 1.1.2	Špecifický cieľ 1.2.1	Špecifický cieľ 1.2.2	Špecifický cieľ 2.1.1	Špecifický cieľ 2.1.2	Špecifický cieľ 2.2.1	Špecifický cieľ 2.2.2	Špecifický cieľ 2.2.3	Špecifický cieľ 3.1.1	Špecifický cieľ 3.1.2	Špecifický cieľ 3.1.3	Špecifický cieľ 3.2.1	Špecifický cieľ 3.2.2	Špecifický cieľ 3.2.3
Vybudovať udržateľný model multimodálnej a ekologickej mobility	Nastaviť systém energeticky efektívneho rozvoja	Nastaviť koncepčný prístup k ochrane prírody a krajiny, prevencii rizík a adaptácii na nepriaznivé zmeny klímy	Skvalitniť a zefektívniť systém nakladania s odpadom	Zlepšiť kvalitu a podmienky pre predprimárne a primárne vzdelávanie	Uľahčiť prístup na trh práce všetkým skupinám obyvateľov	Zabezpečiť dostupnosť kvalitných a integrovaných sociálnych a zdravotných služieb pre všetkých	Vytvoriť podmienky pre zdravý životný štýl	Zvýšiť bezpečnosť obyvateľov	Vybudovať analytické, strategické, projektové a administrat. kapacity	Podporovať digitálnu transformáciu vo všetkých oblastiach	Podporovať medzisektorové partnerstvá	Rozvíjať inovačný potenciál, podporovať vedu, výskum a všetky typy inovácií	Rozvíjať potenciál pre kultúrny a kreatívny priemysel	Rozvíjať potenciál územia vďaka komplexnej podpore podnikania
DOPRAVA	ENERGETIKA	KLÍMA	ODPAD	VZDELÁVANIE	PRÁCA	SOCIÁLNE A ZDRAV. SLUŽBY	ŠPORT	BEZPEČNOSŤ	KAPCITY	DIGITALIZÁCIA	SPOLUPRÁCA	INOVÁCIE	KULT. A KREAT. PRIEMYSEL	PODNIKANIE - CESTOV. RUCH

[32] Vlastné spracovanie

3.3. INTERVENČNÝ RÁMEC

Pre dosiahnutie vízie boli stanovené tri prioritné oblasti rozvoja, zamerané na zlepšenie kvality života obyvateľov v území, za predpokladu využitia zdrojov štátneho rozpočtu a iných verejných zdrojov vrátane EÚ fondov. **Dôraz bol kladený na súlad strategických cieľov spoločného PHRSR s prioritami a cieľmi strategických a programových dokumentov Slovenskej republiky pre využívanie Európskych štrukturálnych a investičných fondov (EŠIF) na obdobie 2021 - 2027**, konkrétne s Partnerskou dohodou SR na roky 2021 - 2027 a Programom Slovensko.

Základný rámec pre rozvoj územia UMR Prešov tvorí 6 strategických cieľov a 15 špecifických cieľov. Za kritické ciele je možné považovať tie, ktoré majú priamy vplyv na plnenie ostatných cieľov, ale tiež tie, ktoré sú významne ovplyvnené externými faktormi (napríklad investície na regionálnej úrovni, investície štátu alebo iných aktérov, investície, pre ktoré nie sú k dispozícii dostatočné externé zdroje financovania). V navrhovanej stratégii ide najmä o nasledovné ciele:

- ŠC 1.1.1 - Vybudovať udržateľný model multimodálnej a ekologickej mobility
- ŠC 1.1.2 - Nastaviť systém energeticky efektívneho rozvoja
- ŠC 1.2.2 - Skvalitniť a zefektívniť systém nakladania s odpadom
- ŠC 2.2.1 - Zabezpečiť dostupnosť kvalitných a integrovaných sociálnych a zdravotných služieb pre všetkých
- ŠC 2.2.3 - Zvýšiť bezpečnosť obyvateľov

Navrhované intervencie na dosiahnutie stanovených cieľov sú rozpracované na úroveň konkrétnych rozvojových aktivít a projektov. Vzhľadom na nedostatok finančných zdrojov na realizáciu všetkých navrhovaných intervencií bola nevyhnutná priorizácia - výber tzv. strategických intervencií. **Zostavený bol Akčný plán PREŠOV 2030 na obdobie rokov n+2** (2023 - 2025), ktorý je súborom Akčného plánu mesta Prešov a Akčných plánov obcí Haniska, Ľubotice a Záborské. **Pri výbere intervencií boli zohľadňované primárne nasledovné skutočnosti - potreba územia, stav pripravenosti projektov, dopad na rozvoj územia.** Akčný plán PREŠOV 2030 tvorí samostatnú prílohu strategického dokumentu.
Strategický dokument **PREŠOV 2030 je v súlade s existujúcou územnoplánovacou dokumentáciou mesta Prešov a obcí v rámci UMR Prešov**, s prioritami a cieľmi rozvoja územia a so **strategickými a programovými dokumentmi Slovenskej republiky,** viď. tabuľka 3.

Tabuľka 3 Súlad priorít stratégie PREŠOV 2030 s prioritami Programu Slovensko [33]

PRIORITY PREŠOV 2030	PRIORITY PROGRAM SLOVENSKO (P_SK)				
	1	2	3	4	5
	Konkurencieschopnejšie a inteligentnejšie SK	Zelenšie SK	Prepojenejšie SK	Sociálnejšie a inkluzívnejšie SK	Európa bližšie k občanom
1 - PROSTREDIE	×	✓	✓	×	✓
2 - ĽUDIA	✓	×	×	✓	×
3 - ROZVOJ	✓	×	×	✓	✓

[33] Vlastné spracovanie

4. PROGRAMOVÁ ČASŤ

Programová časť strategického dokumentu PREŠOV 2030 nadväzuje na strategickú časť. V programovej časti sú popísané prioritné oblasti rozvoja územia UMR Prešov z hľadiska výziev a problémov na ktoré reagujú, prehľad a zameranie konkrétnych cieľov, vrátane navrhovaných intervencií **na dosiahnutie kľúčových ukazovateľov výstupov a udržateľných zmien.**

4.1 PRIORITA 1 - UDRŽATEĽNÉ A ODOLNÉ PROSTREDIE

Spoločným záujmom UMR Prešov je chrániť životné prostredie a podporovať trvalo udržateľný rozvoj. Zámerom samospráv UMR Prešov je využívať moderné a efektívne riešenia, s čo najmenšou mierou negatívnych environmentálnych dopadov.

Prešov, ako jadrové mesto UMR Prešov, je súčasťou dôležitého dopravného prepojenia, preto **v oblasti dopravy bude kladený dôraz na budovanie, modernizáciu a dekarbonizáciu miestnej dopravnej infraštruktúry a dopravného systému, integráciu jednotlivých typov dopravy, podporu ekologických foriem dopravy, vrátane podpory zdieľanej dopravy a využívanie inteligentných systémov v doprave** v čo najväčšej miere tak, aby sa zvýšil užívateľský komfort obyvateľov a návštevníkov pri preprave a došlo k významnej eliminácii negatívnych dopadov na životné prostredie.

Energia je stále vzácnejšou a drahšou komoditou, preto samosprávy UMR Prešov budú vyvíjať **maximálne úsilie v oblasti dosahovania energetickej efektívnosti,** znižovania spotreby energie a zvyšovania podielu využívania obnoviteľných zdrojov energie.

Podporované budú **systémové opatrenia zamerané na ochranu aj obnovu celkového environmentálneho ekosystému,** redukciu emisií skleníkových plynov a zmierňovanie negatívnych dopadov zmeny klímy v území s cieľom vytvoriť koordinačný mechanizmus na **zabezpečenie účinnej implementácie adaptačných opatrení**, vrátane zvýšenia celkovej informovanosti o tejto problematike.

Významná pozornosť bude venovaná **nastaveniu efektívneho systému nakladania s odpadom, znižovaniu množstva produkovaného odpadu, šetreniu prírodných zdrojov a zvýšeniu miery triedenia a recyklácie, vrátane aplikácie princípov cirkulárnej ekonomiky.**

Pri ochrane životného prostredia je úloha každého občana nezastupiteľná, preto významné úsilie bude zamerané na **budovanie a kultiváciu vzťahov občanov k prírode a verejnému priestoru,** aj prostredníctvom osvety a vzdelávania so zámerom žiť v zdravšom a čistejšom prostredí.

Väzby na iné dokumenty:

- Agenda 2030
- Zelená dohoda EÚ
- Nový európsky rámec v oblasti mobility
- Európske partnerstvo Horizont Európa „Podpora mestskej transformácie“

- Dohovor primátorov a starostov o klíme a energetike
- Akčný plán EÚ pre nulové znečistenie
- Stratégia EÚ pre biodiverzitu
- Stratégia EÚ pre adaptáciu na zmenu klímy
- Stratégia EÚ pre zelenú infraštruktúru
- Dohoda o zelených mestách
- Zelenšie Slovensko - Stratégia environmentálnej politiky Slovenskej republiky do roku 2030, MŽP SR
- Integrovaný národný energetický a klimatický plán do roku 2030, MH SR
- Stratégia adaptácie SR na nepriaznivé dôsledky zmeny klímy, MŽP SR, rok aktualizácie 2018

Tabuľka 4 PRIORITA 1 UDRŽATEĽNÉ A ODOLNÉ PROSTREDIE

PRIORITA 1	**UDRŽATEĽNÉ A ODOLNÉ PROSTREDIE**
Parametre	2 strategické ciele 4 špecifické ciele
Výzvy a problémy	- vysoký podiel individuálnej dopravy - nedostatočná, resp. zastaralá infraštruktúra vo väzbe na ekologické formy verejnej osobnej dopravy - neuspokojivý stav miestnych komunikácií a mostných objektov - regulácia statickej dopravy - nedostatočná infraštruktúra pre elektromobilitu - absencia integrovaného dopravného systému - chýbajúca cyklistická infraštruktúra - nízka energetická účinnosť a efektívnosť verejných budov - klimatické zmeny - množstvo odpadu a nakladanie s odpadom - úroveň znečistenia ovzdušia - zavádzanie inteligentných riešení

Strategický cieľ 1.1	**Podporiť dekarbonizáciu, udržateľnosť dopravnej infraštruktúry a energetiky**
Očakávaná zmena	Inteligentne riadený, bezemisný, integrovaný dopravný systém územia UMR Prešov, zahŕňajúci kvalitnú, bezpečnú a udržateľnú dopravnú infraštruktúru, funkčný a účinný systém energetického manažérstva, moderné služby prispievajúce k atraktivite územia UMR Prešov a kvalite života obyvateľov.
Kľúčové ukazovatele	- **Výstup:** podporená infraštruktúra (nová, zrekonštruovaná, modernizovaná, transformovaná) - **Výsledok:** odhadované emisie skleníkových plynov, ročný počet užívateľov infraštruktúry modernizovanej/ rekonštruovanej - **Dopad:** index kvality a udržateľnosti infraštruktúry

Špecifický cieľ 1.1.1	**Vybudovať udržateľný model multimodálnej a ekologickej mobility**
Intervencie (rámcové okruhy)	- Koordinácia výstavby siete TEN-T a medzinárodného spojenia s Poľskom (R4), vrátane obchvatov mesta a obcí, v spolupráci so všetkými relevantnými partnermi; - Implementácia integrovaného dopravného systému (IDS Východ) v území, vrátane rekonštrukcie, modernizácie a výstavby infraštruktúry slúžiacej pre verejnú dopravu (napr. zastávky, informačný systém pre cestujúcich); - Modernizácia cestnej infraštruktúry (miestne komunikácie, cesty II. a III. triedy, infraštruktúra pre peších) a obnova mostov v zlom až havarijnom stave; - Rekonštrukcia a výstavba prestupných bodov a záchytných parkovísk v najvyťaženejších dopravných uzloch s prepojením na integrovaný dopravný systém; - Zavedenie nízkoemisných zón a miestnej parkovacej politiky (zonácia, rezidenčné parkovanie); - Dobudovanie, modernizácia a dekarbonizácia miestnej dopravnej infraštruktúry a dopravného systému, vrátane nových trolejbusových tratí, mobilných prostriedkov MHD, rekonštrukcie údržbovej základne (depa) a podpory zdieľanej dopravy; - Dobudovanie cyklistickej infraštruktúry v jadrovom meste a prímestských oblastiach; - Podpora využívania inteligentných riešení v doprave (smart parking, regulácia dopravy a pod.).
Zoznam projektov	- Viď. samostatná príloha: Akčný plán PREŠOV 2030
Indikátory	- podporená infraštruktúra (vybudovaná, zrekonštruovaná, modernizovaná...) - užívatelia infraštruktúry - zavedené prvky internetu vecí na podporu prioritných oblastí
Gestor	príslušný odbor/útvar/úsek MsÚ Prešov, poverený pracovník OcÚ
Kľúčoví aktéri v území	PSK, SUC PSK, DPMP, a.s., poskytovatelia dopravných služieb, SSC, NDS
Väzba na sektorové strategické dokumenty územia:	- Plán udržateľnej mobility PSK - Stratégia udržateľného rozvoja dopravy mesta Prešov - Územný plán mesta Prešov a územné plány obcí
Špecifický cieľ 1.1.2	**Nastaviť systém energeticky efektívneho rozvoja**
Intervencie (rámcové okruhy)	- Realizácia efektívneho plánovania, poskytovanie systematickej podpory v oblasti energetických úspor a zvyšovanie podielu obnoviteľných zdrojov energie v spolupráci s lokálnymi partnermi; - Implementácia riešení zvyšujúcich energetickú efektívnosť budov a znižujúcich emisie skleníkových plynov; - Budovanie a modernizácia mestskej/obecnej infraštruktúry na výrobu a distribúciu energie z obnoviteľných zdrojov energie a aktivít zameraných na znižovanie emisií prachových častíc z vykurovania domácností; - Realizácia aktivít zameraných na znižovanie emisií prachových častíc z vykurovania domácností; - Podpora využívania inteligentných energetických systémov a sietí v čo najväčšej miere.
Zoznam projektov	- Viď. samostatná príloha: Akčný plán PREŠOV 2030

Indikátory	- podporená infraštruktúra (nová, zrekonštruovaná, modernizovaná...) - zníženie emisií skleníkových plynov - verejné budovy na úrovni nízkoenergetickej, ultranízkoenergetickej alebo s takmer nulovou spotrebou energie - elektrická energia vyrobená v zariadení OZE - zavedené prvky internetu vecí na podporu prioritných oblastí
Gestor	príslušný odbor/útvar/úsek MsÚ Prešov, poverený pracovník OcÚ
Kľúčoví aktéri v území	RIA, n.o., poskytovatelia energetických služieb, vlastníci a správcovia budov
Väzba na sektorové strategické dokumenty územia:	- Akčný plán udržateľného energetického rozvoja mesta Prešov, rok spracovania 2018 (Záväzok Dohovoru primátorov a starostov) - Systém energetického manažérstva mesta Prešov, rok spracovania 2020

Strategický cieľ 1.2	**Zlepšiť stav životného prostredia**
Očakávaná zmena	Odolné mestské prostredie s dostatočným podielom zelenej a modrej infraštruktúry, pripravené čeliť možným krízam a udržiavať potrebnú infraštruktúru pre zabezpečenie kvality životného prostredia v rozvojovom území vo všetkých zložkách.
Kľúčové ukazovatele	**Výstup:** počet projektov adaptačných opatrení **Výsledok:** pokles znečistenia CO_2; vytvorené alebo obnovené otvorené priestranstvá v mestských oblastiach **Dopad:** index kvality životného prostredia
Špecifický cieľ 1.2.1	**Nastaviť koncepčný prístup k ochrane prírody a krajiny, prevencii rizík a adaptácii na nepriaznivé zmeny klímy**
Intervencie (rámcové okruhy)	- Vypracovanie, priebežné vyhodnocovanie a aktualizácia koncepčných dokumentov pre oblasť adaptácie na nepriaznivé zmeny klímy (stratégia a akčný plán), aktualizácia plánov manažmentu povodňového rizika a vypracovanie adaptačných stratégií; - Realizácia aktivít zameraných na ochranu prírody, krajiny a biotopov a podporujúcich biodiverzitu a ekosystémové služby; - Realizácia preventívnych opatrení v krajine a na vodných tokoch ako ochranu pred povodňami; vodozádržných opatrení v urbanizovanej krajine; hydrogeologických prieskumov; sanácie zosuvov pôdy; - Zlepšenie systému monitorovania a riadenia kvality ovzdušia (aj s efektívnejším využívaním dát a inteligentných systémov), ako aj prevencie a manažmentu s tým spojených rizík; - Budovanie a modernizácia systémov vyhodnocovania rizík, ako aj systémov včasného varovania a vyrozumenia obyvateľov pred prírodnými katastrofami; - Budovanie environmentálneho povedomia obyvateľov o zmenách klímy, podpora osvety zameranej na ochranu životného prostredia v širokom kontexte.
Zoznam projektov	- Viď. samostatná príloha: Akčný plán PREŠOV 2030
Indikátory	- cielené opatrenia k zníženiu zraniteľnosti územia na dopady zmeny klímy, - podporená zelená infraštruktúra (vybudovaná, zrevitalizovaná), - vybudované prvky zelenej infraštruktúry - vytvorené alebo obnovené otvorené priestranstvá v mestských oblastiach - užívatelia infraštruktúry

Gestor	príslušný odbor/útvar/úsek MsÚ Prešov, poverený pracovník OcÚ
Kľúčoví aktéri v území	TSmP a.s., MESTSKÝ PODNIK SLUŽIEB PREŠOV s.r.o, MVO, miestne komunity
Väzba na sektorové strategické dokumenty územia:	- Základná stratégia adaptácie na nepriaznivé zmeny klímy na území mesta Prešov, rok spracovania 2018 (Záväzok Dohovoru primátorov a starostov)
Špecifický cieľ 1.2.2	**Skvalitniť a zefektívniť systém nakladania s odpadom**
Intervencie (rámcové okruhy)	- Vypracovanie, priebežné vyhodnocovanie a aktualizácia koncepčných dokumentov pre oblasť odpadového hospodárstva (stratégia a akčný plán); - Zavádzanie integrovaných a inteligentných riešení v oblasti nakladania odpadmi, ako aj systémov pre zhodnocovanie rôznych druhov odpadov; - Zavádzanie motivačných systémov pre obyvateľov pre zber a triedenie komunálneho odpadu s cieľom zvyšovať podiel vytriedených zložiek a znižovať množstvo vyprodukovaného zmesového odpadu (napr. prostredníctvom množstvového zberu, žetónového systému, lístkového systému); - Budovanie povedomia obyvateľov o prínose obehového hospodárstva pre zvýšenie kvality a udržateľnosti životného prostredia najmä prostredníctvom predchádzania vzniku odpadu, jeho znižovania, efektívneho využívania zdrojov, či opätovného použitia, opráv a recyklácie produktov (aj v spolupráci s Ekocentrum Prešov a ďalšími partnermi).
Zoznam projektov	- Viď. samostatná príloha: Akčný plán PREŠOV 2030
Indikátory	- podporená infraštruktúra (nová, zrekonštruovaná, modernizovaná, transformovaná) - produkcia komunálnych odpadov, - pomer objemu (váhy) materiálovo zhodnoteného odpadu k celkovému separovanému odpadu, - pomer energeticky zhodnoteného odpadu (spaľovňa, bioplyn) k celkovej produkcii odpadu
Gestor	príslušný odbor/útvar/úsek MsÚ Prešov, poverený pracovník OcÚ
Kľúčoví aktéri v území	TSmP a.s., Ekocentrum Prešov, MVO, miestne komunity
Väzba na sektorové strategické dokumenty územia:	- Program odpadového hospodárstva mesta Prešov, 2015 - 2020

4.2 PRIORITA 2 - SLUŽBY PRE DÔSTOJNÝ ŽIVOT

Kvalita života obyvateľov UMR Prešov zahŕňa veľa kľúčových oblastí - od kvality vzdelávania, cez uplatnenie sa na trhu práce až po dostupnosť zdravotnej a sociálnej starostlivosti, cenovo prijateľné bývanie, vhodné podmienky pre kultúrne vyžitie, šport a relax.

Výrazný potenciál územia je v ľuďoch, je potrebné ho nielen podporovať, ale aj rozvíjať. Prešov je prirodzeným kultúrnym, hospodárskym, dopravným a administratívnym centrom, miestom stretávania obyvateľov, veľkého množstva študentov, ale aj návštevníkov. Prešov je a chce byť ľuďmi podkutým mestom. Preto UMR Prešov bude investovať do budovania podnetného, zdravého a inkluzívneho prostredia pre všetkých.

UMR Prešov bude realizovať aktivity, ktoré pomôžu zvýšiť kvalitu vzdelávania detí a mladých ľudí - aby zažívali úspech v škole, živote aj pri uplatnení sa v spoločnosti. V spolupráci so zamestnávateľmi, univerzitami a ďalšími partnermi **bude aktívne podporovať vytváranie pracovných príležitostí**, aby obyvatelia územia mohli kontinuálne a počas produktívneho života nájsť uplatnenie na miestnom trhu práce.

Kvalita života je neodmysliteľne spojená so zdravotným stavom jednotlivca, ale aj populácie. Snahou UMR Prešov bude **zabezpečiť pre všetkých obyvateľov, vrátane znevýhodnených a zraniteľných skupín, dostupné kvalitné zdravotné a sociálne služby.** Zlepšením zdravotného stavu obyvateľov dôjde nielen k zvýšeniu subjektívne pociťovanej kvality života, ale i k zlepšeniu ekonomických ukazovateľov (napr. nákladov na poskytovanú zdravotnú či sociálnu starostlivosť).

Ku kvalite života prispieva aj možnosť kultúrneho vyžitia - **rozširovanie možností v oblasti kultúrneho vyžitia, dostupnosť kultúry, čo najširšiemu spektru návštevníkov** UMR Prešov, blízkeho okolia, Slovenska, ale aj zo zahraničia, bude aktívne podporovaná**, vrátane podpory spolupráce medzi kultúrnymi aktérmi, vzdelávacími inštitúciami a rôznymi kultúrami.** Snahou bude **posilniť tvorivú atmosféru v území, vrátane kreatívnych odvetví.**

Šport a fyzická aktivita tvoria neoddeliteľnú súčasť zdravého životného štýlu, prispievajú k zlepšeniu fyzického a psychického zdravia a prinášajú radosť z pohybu, vrátane športových aktivít v prírodnom prostredí. Šport plní aj socializačnú úlohu, prispieva k lepšiemu zdravotnému stavu obyvateľov a zníženiu nákladov na zdravotnú starostlivosť, preto zámerom UMR Prešov je **vytvárať podmienky pre aktívne trávenie voľného času, pohyb v prírode a šport - amatérsky aj profesionálny**.

Bezpečnosť, pri súčasnom vývoji vo svete, je veľmi dôležitým ukazovateľom kvality života. Mesto Prešov dlhodobo realizuje opatrenia na zvýšenie bezpečnosti obyvateľov v rôznych oblastiach. **Bezpečnostný a krízový manažment v podmienkach UMR Prešov** predstavuje špecifickú výzvu, v rámci zákonných ustanovení. **UMR Prešov bude investovať do zvýšenia bezpečnosti obyvateľov v rôznych oblastiach** (krízové plánovanie, bezpečnostný manažment, ochrana majetku, ochrana osobných údajov, ekologické riziká, dopravná bezpečnosť a pod.) s cieľom kvalitného a bezpečného života v území.

Väzby na iné dokumenty:

- Agenda 2030 - Národné priority implementácie Agendy 2030 (ÚPVII SR)
- Ciele politiky EÚ v programovacom období 2021 - 2027
- Stratégia Rady Európy pre mládež do roku 2030
- Program hospodárskeho a sociálneho rozvoja Prešovského samosprávneho kraja na roky 2021-2030
- Program pre sociálnu zmenu a inovácie v oblasti zamestnanosti a sociálneho začleňovania
- Implementačná stratégia - systém integrovaného poskytovania zdravotnej starostlivosti:

Modernizácia zdravotníckej infraštruktúry a zlepšenie dostupnosti kvalitných služieb v primárnej a akútnej lôžkovej zdravotnej starostlivosti, Ministerstvo zdravotníctva SR, rok aktualizácie 2018

- Strategický rámec starostlivosti o zdravie pre roky 2014 - 2030, Ministerstvo zdravotníctva SR, obdobie 2014 - 2030
- Koncepcia rozvoja sociálnych služieb v Prešovskom samosprávnom kraji na roky 2020 - 2025, Prešovský samosprávny kraj
- Stratégia PSK pre mládež na roky 2015 - 2020 s výhľadom do roku 2025, Prešovský samosprávny kraj
- Quo vadis, Romale? Rómske komunity na území Prešovského samosprávneho kraja, Prešovský samosprávny kraj, rok spracovania 2021

Tabuľka 5 PRIORITA 2 SLUŽBY PRE DÔSTOJNÝ ŽIVOT

PRIORITA 2	**SLUŽBY PRE DÔSTOJNÝ ŽIVOT**
Parametre	- 2 strategické ciele - 5 špecifických cieľov
Výzvy a problémy	- kvalita a dostupnosť vzdelávania - prepojenie vzdelávania s dopytom na trhu práce - adaptácia na potreby trhu práce - rodová segregácia - pracovné príležitosti pre znevýhodnené skupiny - kvalita a dostupnosť sociálnych služieb (komunitných aj pobytových) - miera podpory sociálno - ekonomickej integrácie - možnosti na aktívne trávenie voľného času pre všetky skupiny obyvateľov - využitie potenciálnu kultúrnych a prírodných aktív - podpora kultúry a kreatívnych odvetví - bezpečnostné a preventívne opatrenia

Strategický cieľ 2.1	**Zabezpečiť kvalitné vzdelávanie pre potreby trhu práce**
Očakávaná zmena	Kvalitná a moderná infraštruktúra pre vzdelávanie dostupná všetkým vekovým skupinám a využívajúca benefity moderných technológií a inovácií.
Kľúčové ukazovatele	- **Výstup:** podporená infraštruktúra (nová, zrekonštruovaná, modernizovaná, transformovaná) - **Výsledok:** nové služby - **Dopad:** index kvality a udržateľnosti infraštruktúry
Špecifický cieľ 2.1.1	**Zlepšiť kvalitu a podmienky pre predprimárne a primárne vzdelávanie**
Intervencie (rámcové okruhy)	- Zabezpečiť prístup k predprimárnemu a primárnemu vzdelávaniu pre všetky skupiny obyvateľov a podporovať inkluzívne vzdelávanie na všetkých úrovniach; - Zvýšiť kvalitu vzdelávania a budovania zručností detí a mladých ľudí, vrátane rozvoja ich odbornej prípravy, podpory digitálnych zručností, zabezpečenia materiálno-technického vybavenia široko-dostupnej siete škôl v území; - Zvýšiť kompetencie a zručnosti pedagogických pracovníkov, vrátane

	manažérskych zručností u riadiacich pracovníkov na školách; - Zvýšiť zapojenie podporných profesií v školstve do procesu formálneho vzdelávania ako včasná intervencia pridružených sociálnych, psychologických a ďalších problémov detí a mládeže - predovšetkým školských psychológov, špeciálnych pedagógov, asistentov učiteľov a logopédov (v predprimárnom vzdelávaní).
Zoznam projektov	- Viď. samostatná príloha: Akčný plán PREŠOV 2030
Indikátory	- podporená infraštruktúra MŠ, ZŠ (nová, zrekonštruovaná, modernizovaná...) - počet užívateľov infraštruktúry - % hrubej zaškolenosti detí v MŠ - počet podporených prvkov debarierizácie - počet nových a zavedených výchovno-vzdelávacích programov v základných školách pre deti so špeciálnymi výchovno-vzdelávacími potrebami
Gestor	príslušný odbor/útvar/úsek MsÚ Prešov, poverený pracovník OcÚ
Kľúčoví aktéri v území	poskytovatelia vzdelávania, MVO
Väzba na sektorové strategické dokumenty územia:	nie sú k dispozícii
Špecifický cieľ 2.1.2	**Uľahčiť prístup na trh práce všetkým skupinám obyvateľov a rozšíriť možnosti uplatnenia**
Intervencie (rámcové okruhy)	- Poskytovať súčinnosť hospodárskym subjektom pôsobiacim v regióne pri tvorbe pracovných príležitostí (napr. obnova verejnej infraštruktúry, dopravná dostupnosť); - Podporovať partnerov a poskytovať súčinnosť pri realizácii aktivít zameraných na prilákanie investorov do lokality so záujmom o realizáciu rozvojových a/alebo inovatívnych projektov; - Realizovať aktivity v spolupráci s partnermi zamerané na podporu férového, flexibilného, rodovo vyváženého a inkluzívneho zamestnávania a odmeňovania lokálnymi zamestnávateľmi; - Implementovať udržateľný model subjektu sociálnej ekonomiky manažovaný mestom, resp. obcami (napr. sociálny podnik); - Zabezpečiť podporu plynulého prechodu obyvateľov medzi jednotlivými fázami životného cyklu (vzdelávanie, trh práce, poproduktívny vek), s osobitným dôrazom na špecifiká ľudí so zdravotným či iným znevýhodnením; - Podporovať komplexný systém celoživotného vzdelávania založeného na participácii všetkých aktérov (zamestnanec, zamestnávateľ, štát), s dôrazom na špecifické potreby znevýhodnených a zraniteľných skupín obyvateľov.
Zoznam projektov	- Viď. samostatná príloha: Akčný plán PREŠOV 2030
Indikátory	- podporená infraštruktúra (nová, zrekonštruovaná, modernizovaná...) - spoločné projekty aktérov, - pilotné aktivity, - model služieb/nové služby

Gestor	príslušný odbor/útvar/úsek MsÚ Prešov, poverený pracovník OcÚ
Kľúčoví aktéri v území	MVO, MESTSKÝ PODNIK SLUŽIEB PREŠOV s.r.o, zamestnávatelia, Úrad práce, sociálnych vecí a rodiny Prešov
Väzba na sektorové strategické dokumenty územia:	- Komunitný plán sociálnych služieb mesta Prešov na roky 2018 - 2025 - Obec Haniska - Komunitný plán sociálnych 2018 - 2023 - Komunitný plán sociálnych služieb obce Ľubotice na roky 2018 - 2027 - Obec Záborské - Komunitný plán sociálnych služieb (2016 - 2025)

Strategický cieľ 2.2	**Zabezpečiť dostupnú infraštruktúru, kvalitu služieb a podmienky pre vyššiu kvalitu života**
Očakávaná zmena	Kvalitná a moderná infraštruktúra verejných služieb dostupná všetkým vekovým skupinám obyvateľov a využívajúca benefity moderných technológií a inovácií.
Kľúčové ukazovatele	- **Výstup:** podporená infraštruktúra (nová, zrekonštruovaná, modernizovaná, transformovaná) - **Výsledok:** nové služby - **Dopad:** index kvality a udržateľnosti infraštruktúry
Špecifický cieľ 2.2.1	**Zabezpečiť dostupnosť kvalitných a integrovaných sociálnych a zdravotných služieb pre všetkých**
Intervencie (rámcové okruhy)	- Implementovať systémové riešenia v dostupnosti, kvalite a integrácii poskytovaných aj nových sociálnych a zdravotných služieb a podporovať rovnocennosť pri financovaní verejných a neverejných poskytovateľov sociálnych služieb; - Modernizovať priestory a rozšíriť kapacitu zariadení, v ktorých sú poskytované sociálne/integrované služby vo všetkých formách (rezidenčné, individualizované aj komunitne organizované); - Zlepšiť prístup k dostupnému a primeranému bývaniu - a špecificky nájomnému bývaniu - pre rôzne skupiny obyvateľov, vrátane nízkopríjmových domácností; - Podporiť sociálnu inklúziu príslušníkov znevýhodnených a zraniteľných skupín obyvateľov, vrátane marginalizovaných rómskych komunít.
Zoznam projektov	- Viď. samostatná príloha: Akčný plán PREŠOV 2030
Indikátory	- podporená infraštruktúra pre znevýhodnené skupiny (nová, zrekonštruovaná, modernizovaná, transformovaná), - kapacita infraštruktúry pre znevýhodnené skupiny
Gestor	príslušný odbor/útvar/úsek MsÚ Prešov, poverený pracovník OcÚ
Kľúčoví aktéri v území	poskytovatelia sociálnych služieb, poskytovatelia ZS, MVO, miestne komunity
Väzba na sektorové strategické dokumenty územia:	- Komunitný plán rozvoja sociálnych služieb, mesto Prešov, 2018 - 2025, - Potenciál mesta Prešov v oblasti Smart City, mesto Prešov, rok spracovania 2018, - Program rozvoja bývania mesta Prešov do roku 2030, mesto Prešov, 2023 - 2030, - Komunitný plán sociálnych služieb 2018 - 2023, obec Haniska, - Komunitný plán sociálnych služieb obce Ľubotice na roky 2018 - 2027, obec Ľubotice,

	- Komunitný plán Záborské (2016 - 2025), obec Záborské
Špecifický cieľ 2.2.2	**Vytvoriť podmienky pre zdravý životný štýl**
Intervencie (rámcové okruhy)	- Investovať do budovania a modernizácie infraštruktúry a do aktivít na podporu zdravého životného štýlu, ako aj aktívneho trávenia voľného času všetkými skupinami obyvateľov; - Budovať a skvalitňovať športovú infraštruktúru využívanú aj pre profesionálny šport, vrátane potrebného materiálno-technického vybavenia; - Zrealizovať výstavbu a modernizáciu prvkov športovej infraštruktúry v školách a školských areáloch s hľadaním možností jej využitia pre širšiu verejnosť ako súčasť komplexnej revitalizácie existujúcich areálov škôl.
Zoznam projektov	- Viď. samostatná príloha: Akčný plán PREŠOV 2030
Indikátory	- podporená infraštruktúra (nová, zrekonštruovaná, modernizovaná...)
Gestor	príslušný odbor/útvar/úsek MsÚ Prešov, poverený pracovník OcÚ
Kľúčoví aktéri v území	Prešov REAL, s.r.o., MVO, športové kluby, školy, miestne komunity
Väzba na sektorové strategické dokumenty územia:	- nie sú k dispozícii
Špecifický cieľ 2.2.3	**Zvýšiť bezpečnosť obyvateľov**
Intervencie (rámcové okruhy)	- Budovať prvky a prijímať opatrenia zamerané na zvýšenie bezpečnosti v doprave; - Zavádzať riešenia zvyšujúce kvalitu bezpečnosti obyvateľov vo verejných priestoroch; - Realizovať osvetové aktivity zamerané na podporu a zvýšenie bezpečnosti obyvateľov; - Skvalitniť činnosť a materiálno-technické zázemie záchranných zložiek pôsobiacich v území s prepojením na ostatné zložky integrovaného záchranného systému (mestskej a obecnej polície, dobrovoľných hasičov); - Zvýšiť kapacitu efektívne reagovať na mimoriadne udalosti formou včasnej a efektívnej intervencie, manažovať ich, ako aj kontinuálne riadiť riziká spojené s ich výskytom.
Zoznam projektov	- Viď. samostatná príloha: Akčný plán PREŠOV 2030
Indikátory	- podporená infraštruktúra (nová, zrekonštruovaná, modernizovaná...) - počet informačných systémov verejnej správy na rozpoznávanie, monitorovanie a riadenie bezpečnostných incidentov
Gestor	príslušný odbor/útvar/úsek MsÚ Prešov, poverený pracovník OcÚ
Kľúčoví aktéri v území	MsP, MVO, miestne komunity
Väzba na sektorové strategické dokumenty územia:	- Bezpečnostná stratégia kybernetickej bezpečnosti, Prešov 2021

4.3 PRIORITA 3 - STRATEGICKÝ ROZVOJ A DOBRÉ SPRAVOVANIE

Strategické a územné plánovanie je základným predpokladom pre systematický, vyvážený a udržateľný rozvoj územia. Prešov, ako jadrové mesto **UMR Prešov je miestom potenciálu - v inováciách, kreativite aj cestovnom ruchu, je ho potrebné efektívne premieňať na reálne možnosti pre všetkých.**

Kľúčovou snahou UMR Prešov bude, aby sa Prešov stal živým mestom nápadov a kreativity. Bude podporovaná **veda, výskum a všetky formy inovácií**, aby bolo možné pretaviť inovačný potenciál do nových projektov, produktov či riešení. Bude **potrebné investovať do rozvoja kultúrnych a kreatívnych odvetví**, aby bol podporovaný kreatívny potenciál, ktorý v regióne je a ktorý bude potrebné cielene kultivovať.

Významná podpora bude venovaná **cestovnému ruchu, ako nástroju pre rozvoj potenciálu územia**, aby Prešov ako pulzujúce srdce Šariša objavili a zamilovali si návštevníci z rôznych kútov Slovenska aj sveta. Je nevyhnutné, aby pri týchto snahách nové iniciatívy vychádzali zo strategického prístupu a rešpektovali potrebu dlhodobej udržateľnosti.

UMR Prešov združuje samosprávy, ktoré cítia **zodpovednosť za svojich občanov a zdroje, ktoré majú k dispozícii**. Bude nevyhnutné **vybudovať dostatočné kapacity - analytické, strategické, projektové a administratívne**, aby bolo možné všetky procesy, výzvy a riziká v území UMR sledovať, analyzovať a efektívne riadiť.

Samosprávy UMR Prešov majú ambície ísť príkladom a aktívne skúšať nové prístupy a riešenia, kde to len bude možné. Budú **podporovať digitálnu transformáciu** a snažiť sa **využívať moderné technológie, inteligentné riešenia či dátové nástroje** v čo najväčšom možnom rozsahu. Zámerom UMR Prešov je aktívne budovať a rozvíjať partnerskú komunikáciu, aktívne zapájať a konštruktívne spolupracovať s externými odborníkmi, ale aj občanmi. UMR Prešov bude **realizovať cielené aktivity zamerané na rozvoj miestneho inovačného ekosystému**, komunitnej spolupráce v záujme rozvoja a dlhodobej prosperity založenej na dôvere a spolupráci.

Elektronizácia a automatizácia procesov, vrátane zabezpečenia možnosti realizovať úkony nutné zo strany občanov z mobilného zariadenia, prinesú pozitívne efekty. UMR Prešov bude **pokračovať v poskytovaní otvorených dát, rozvíjať bude ich rozsah a kvalitu a aktívne bude podporovať ich využívanie**. Vďaka jednotnému informačnému portálu, kde budú prehľadne, zrozumiteľne a **štruktúrovane prezentované pripravované a realizované zámery UMR Prešov**, bude zabezpečená informovanosť obyvateľov, ako aj priestor pre zapojenie do participačných aktivít. **Vytvorením priestoru pre dialóg bude zabezpečená väčšia spokojnosť obyvateľov**.

Väzby na iné dokumenty:

- Agenda 2030 - Národné priority implementácie Agendy 2030 (ÚPVII SR)
- Ciele politiky EÚ v programovacom období 2021 - 2027
- Stratégia Rady Európy pre mládež do roku 2030
- Koncepcia územného rozvoja Slovenska (KURS)
- Územný plán Prešovského samosprávneho kraja
- Koncepcia mestského rozvoja Slovenskej republiky do roku 2030
- Program hospodárskeho a sociálneho rozvoja Prešovského samosprávneho kraja na roky 2021 - 2030
- Akčný plán SMART regióny a mestá

- Stratégia PSK pre mládež na roky 2015 - 2020 s výhľadom do roku 2025, Prešovský samosprávny kraj
- Quo vadis, Romale? Rómske komunity na území Prešovského samosprávneho kraja, Prešovský samosprávny kraj, Prešovský samosprávny kraj, rok spracovania 2021
- Územné plány mesta Prešov a obcí Haniska, Ľubotice, Záborské

Tabuľka 6 PRIORITA 3 STRATEGICKÝ ROZVOJ A DOBRÉ SPRAVOVANIE

PRIORITA 3	**STRATEGICKÝ ROZVOJ A DOBRÉ SPRAVOVANIE**
Parametre	- 2 strategické ciele - 5 špecifických cieľov
Výzvy a problémy	- absencia personálnych kapacít v oblasti analytického vyhodnocovania a strategického plánovania - absencia strategického riadenia a smerovania rozvoja - segregovaný prístup pri spracovaní strategických dokumentov - absencia sektorových strategických dokumentov - nevyužitý potenciál v oblasti smart riešení - nedostatočná úroveň elektoronizácie podaní - nevyužitý potenciál participácie a spolupráce s občanmi - nevyužitý potenciál územia v oblasti cestovného ruchu, kultúrneho a kreatívneho priemyslu

Strategický cieľ 3.1	**Zlepšiť systém strategického plánovania, riadenia a spolupráce**
Očakávaná zmena	Harmonizovať obsah a procesy v oblasti strategického plánovania v rozvojovom území Prešov, vybudovať profesionálne odborné kapacity a využívať všetky výhody nových technológií vrátane digitalizácie.
Kľúčové ukazovatele	- **Výstup:** podporená infraštruktúra a zavedené inovácie - **Výsledok**: model strategického plánovania a územnej spolupráce - **Dopad:** efektívnosť verejnej správy
Špecifický cieľ 3.1.1	**Vybudovať analytické, strategické, projektové a administratívne kapacity**
Intervencie (rámcové okruhy)	- Vytvoriť koncept budovania kapacít mesta Prešov pre strategické plánovanie a riadenie rozvoja mesta Prešov; pre prípravu, implementáciu a riadenie integrovaných územných investícií (IÚI) v rámci UMR - vrátane nastavenia ukazovateľov pre hodnotenie ich efektívnosti; ako aj pre integráciu a spoluprácu zástupcov rôznych úsekov mesta, obcí či partnerov na príprave, monitorovaní, hodnotení a implementácii plánovaných či realizovaných intervencií; - Systematicky budovať a posilňovať analytické a strategické kapacity na úseku strategického rozvoja, zabezpečiť ich kontinuálne vzdelávanie a nevyhnutnú materiálno-technickú podporu; - Podporovať iniciatívy zlepšujúce strategické riadenie v území v spolupráci s partnermi z UMR, Prešovského samosprávneho kraja, štátu ako

	aj s ostatnými partnermi zo súkromného a verejného sektora; - Systematicky podporovať záujem a participáciu občanov na strategickom plánovaní, ako aj efektívnej komunikácie s nimi.
Zoznam projektov	- Viď. samostatná príloha: Akčný plán PREŠOV 2030
Indikátory	- podporená infraštruktúra (nová, zrekonštruovaná, modernizovaná, transformovaná) - počet odborných kapacít - počet zrealizovaných aktivít - zavedený systém strategického riadenia
Gestor	príslušný odbor/útvar/úsek MsÚ Prešov, poverený pracovník OcÚ
Kľúčoví aktéri v území	PSK, MVO, Univerzity, RIA, n.o.
Väzba na sektorové strategické dokumenty územia:	- nie sú vypracované
Špecifický cieľ 3.1.2	**Podporovať digitálnu transformáciu vo všetkých oblastiach**
Intervencie (rámcové okruhy)	- Podporovať digitalizáciu služieb verejnej správy poskytovaných samosprávou; - Implementovať riešenia podporujúce rozširovanie či skvalitňovanie digitálnej infraštruktúry, digitalizáciu verejného priestoru, zabezpečenie požadovanej úrovne kybernetickej bezpečnosti, ako aj využitie digitálnych dát (big data); - Modernizovať vybavenie v oblasti digitálnych technológií v materských školách a základných školách; - Podporovať poskytovanie digitálnych služieb vo všetkých oblastiach hospodárstva - a hlavne v oblastiach cestovného ruchu a kultúrneho a kreatívneho priemyslu.
Zoznam projektov	- Viď. samostatná príloha: Akčný plán PREŠOV 2030
Indikátory	- podporené inštitúcie pri vývoji / implementácii inovatívnych riešení - podporené pilotné a inovatívne riešenia - podporené aktivity na rozvoj GIS platforiem a využívanie priestorových informácií v praxi - vidiecka a mestská populácia so zlepšenou infraštruktúrou a prístupom k verejným službám
Gestor	príslušný odbor/útvar/úsek MsÚ Prešov, poverený pracovník OcÚ
Kľúčoví aktéri v území	MVO, poskytovatelia digitálnych služieb, PSK, Univerzity, organizácie v zriaďovateľskej pôsobnosti samospráv
Väzba na sektorové strategické dokumenty územia:	- Potenciál mesta Prešov v oblasti Smart City
Špecifický cieľ 3.1.3	**Podporovať medzisektorové partnerstvá**
Intervencie (rámcové okruhy)	- Vypracovať inovačnú stratégiu mesta Prešov v širokej spolupráci s miestnymi partnermi; - Vybudovať kapacity pre budovanie partnerstiev, sieťovanie a koordináciu partnerov z rôznych sektorov v rámci podpory rozvoja miestneho inovačného ekosystému;

	- Realizovať aktivity zamerané na sieťovanie lokálnych aktérov zo všetkých sektorov (verejného, súkromného, akademického ako aj neziskového) v rôznych oblastiach, na podporu komunikácie, spolupráce a budovania spoločných platforiem či organizácií, napr. klastrov v rámci inovačného ekosystému.
Zoznam projektov	- Viď. samostatná príloha: Akčný plán PREŠOV 2030
Indikátory	- vypracovaná inovačná stratégia rozvojového územia, - spoločné vo vybraných projekty aktérov územia, - pilotné aktivity doménach MIS
Gestor	príslušný odbor/útvar/úsek MsÚ Prešov, poverený pracovník OcÚ
Kľúčoví aktéri v území	MVO, PSK, organizácie v zriaďovateľskej pôsobnosti samospráv, aktéri verejného a súkromného sektora
Väzba na sektorové strategické dokumenty územia:	- Potenciál mesta Prešov v oblasti Smart City

Strategický cieľ 3.2	**Využiť potenciál územia pre ekonomický rozvoj**
Očakávaná zmena	Prosperujúce územie udržateľného mestského rozvoja využívajúce inovácie predovšetkým na posilnenie konkurenčnej výhody rozvojového územia v prepojení na vedu a výskum verejného a súkromného sektora.
Kľúčové ukazovatele	- **Výstup:** podporená infraštruktúra (nová, zrekonštruovaná, modernizovaná, transformovaná) - **Výsledok:** ekonomická aktivita územia - **Dopad:** index konkurencieschopnosti
Špecifický cieľ 3.2.1	**Rozvíjať inovačný potenciál územia, podporovať vedu, výskum a všetky typy inovácií**
Intervencie (rámcové okruhy)	- Podporovať prípravu a realizáciu spoločných projektov vedy, výskumu a inovácií v spolupráci partnerov z rôznych oblastí a sektorov s využitím inovačného potenciálu existujúcich priemyselných parkov, výskumných a akademických inštitúcií, ako aj jednotlivých inovátorov; - Podporovať rozvoj medzinárodnej spolupráce v oblasti vedy, výskumu a všetkých druhov inovácií (technologických aj netechnologických); - Podporovať špecifické aktivity na podporu rozvoja inovačného potenciálu na všetkých úrovniach (napr. inovatívne spolupráce, špecifické podujatia, súťaže), ako aj rozvoja infraštruktúry pre inovatívne projekty, start-ups, scale-ups či spin-offs (napr. inovačné huby, laby, coworkingy a pod.).
Zoznam projektov	- Viď. samostatná príloha: Akčný plán PREŠOV 2030
Indikátory	- podporená infraštruktúra (nová, zrekonštruovaná, modernizovaná...) - zavedené inovatívne riešenia v samospráve
Gestor	príslušný odbor/útvar/úsek MsÚ Prešov, poverený pracovník OcÚ
Kľúčoví aktéri v území	MVO, miestne komunity, súkromný sektor, vzdelávacie inštitúcie

Väzba na sektorové strategické dokumenty územia:	- Potenciál mesta Prešov v oblasti Smart City
Špecifický cieľ 3.2.2	**Rozvíjať potenciál pre kultúrny a kreatívny priemysel**
Intervencie (rámcové okruhy)	- Podporovať rozvoj kultúrnych a kreatívnych odvetví, ako aj subjektov pôsobiacich v nich, prostredníctvom systémového vytvárania podmienok pre ich pôsobenie v meste Prešov - v oblasti infraštruktúry aj podporných služieb; - Podporovať obnovu a inovatívne využitie hmotného kultúrneho dedičstva v území s prepojením na kultúrny a kreatívny priemysel, s cieľom rozvíjať a prezentovať lokálne nehmotné kultúrne dedičstvo, ako aj generačný prenos kultúrneho dedičstva; - Podporovať aktivity rozvíjajúce existujúci potenciál v oblasti hudby a scénického umenia v meste Prešov; - Podporovať vytváranie estetického a živého verejného priestoru, vrátane podpory public art, a využiť potenciál biokoridoru vodných tokov na území mesta a obcí v spolupráci s miestnou architektonickou komunitou; - Podporovať strategické využitie potenciálu marketingu na prezentáciu, predaj či propagáciu lokálnych aktérov, produktov, ako aj celého spektra kultúrnych a kreatívnych odvetví na Slovensku aj v zahraničí.
Zoznam projektov	- Viď. samostatná príloha: Akčný plán PREŠOV 2030
Indikátory	- podporená infraštruktúra (nová, zrekonštruovaná, modernizovaná...)
Gestor	príslušný odbor/útvar/úsek MsÚ Prešov, poverený pracovník OcÚ
Kľúčoví aktéri v území	MVO, miestne komunity, poskytovatelia služieb v oblasti kultúry a kreatívneho priemyslu, vzdelávacie inštitúcie, záujmové spolky, OOCR
Väzba na sektorové strategické dokumenty územia:	- Zelený okruh - mesto Prešov ako EHMK (koncept) - Kostrová sieť cyklotrás v PSK - Stratégia rozvoja kultúry mesta Prešov 2021 – 2026 (2031) - Koncepcia rozvoja cestovného ruchu v regióne Dolný Šariš v kontexte širších vzťahov medzi prirodzenými destináciami a vzájomného prepojenia aktivít Prešovského samosprávneho kraja
Špecifický cieľ 3.2.3	**Rozvíjať potenciál územia vďaka komplexnej podpore podnikania**
Intervencie (rámcové okruhy)	- Podporovať budovanie, obnovu a inovatívne využitie všetkých typov infraštruktúry a územia pre rozvoj udržateľného cestovného ruchu, vrátane kultúrneho a prírodného dedičstva, za podmienky zabezpečenia ich nevyhnutnej ochrany; - Skvalitňovať služby v oblasti cestovného ruchu (napr. spoločná certifikácia a značka kvality, vzdelávanie pracovníkov v odvetví CR) a rozširovať ponuku doplnkových služieb; - Prepájať historické pamiatky, kultúrne inštitúcie a ďalšie významné objekty formou chodníkov a cyklotrás, vrátane revitalizácie a dobudovania zelenej infraštruktúry v okolí, s cieľom vybudovať tzv. "zelené okruhy" ako priestor pre zdravé, zmysluplné a kultúrne hodnotné trávenie voľného času obyvateľmi – v úzkej koordinácii a synergii s partnermi (Prešovský samosprávny kraj, obce a iné subjekty); - Podporovať využívanie nástrojov efektívneho a strategického marketingu

	v cestovnom ruchu pre prezentáciu lokality na národnej aj medzinárodnej úrovni a vytváranie optimálnych podmienok pre udržateľný destinačný manažment zohľadňujúci špecifické potreby územia; - Podporovať rozvoj a manažment kultúrneho turizmu v území, vrátane budovania brandingu; - Podporovať strategické využitie potenciálu marketingu na prezentáciu, predaj a propagáciu lokálnych aktérov, produktov, ako aj celého spektra služieb cestovného ruchu na Slovensku aj v zahraničí.
Zoznam projektov	- Viď. samostatná príloha: Akčný plán PREŠOV 2030
Indikátory	- podporená infraštruktúra (nová, zrekonštruovaná, modernizovaná...) - nové služby - systém podpory miestnych produktov
Gestor	príslušný odbor/útvar/úsek MsÚ Prešov, poverený pracovník OcÚ
Kľúčoví aktéri v území	MVO, miestne komunity, aktéri súkromného sektora, Regionálna komora SOPK Prešov
Väzba na sektorové strategické dokumenty územia:	- Zelený okruh - mesto Prešov ako EHMK (koncept) - Kostrová sieť cyklotrás v PSK - Stratégia rozvoja kultúry mesta Prešov 2021-2026 (2031) - Koncepcia rozvoja cestovného ruchu v regióne Dolný Šariš v kontexte širších vzťahov medzi prirodzenými destináciami a vzájomného prepojenia aktivít Prešovského samosprávneho kraja - Potenciál mesta Prešov v oblasti Smart City

5. REALIZAČNÁ ČASŤ

Realizačná časť dokumentu nadväzuje na strategickú a programovú časť stratégie PREŠOV 2030, popisuje implementačný mechanizmus a **vytvára rámec pre postupné napĺňanie všetkých strategických cieľov, vedúcich k trvalo udržateľnému rozvoju územia.**
Implementácia stratégie PREŠOV 2030 vychádza z nasledujúcich zásad:

- PREŠOV 2030 je spoločným programom hospodárskeho rozvoja a sociálneho rozvoja na obdobie rokov 2023 - 2027 pre jadrové mesto Prešov a obce Haniska, Ľubotice a Záborské, ktoré spoločne tvoria územie UMR Prešov;
- PREŠOV 2030 je spoločným rozvojovým dokumentom na území UMR Prešov, na ktorý sa musí prihliadať pri realizovaní všetkých rozvojových a rozvoj podporujúcich aktivít územia UMR;
- PREŠOV 2030 je otvorený, verejne dostupný dokument, priebežne monitorovaný, vyhodnocovaný a aktualizovaný vo väzbe na podnety, príležitosti a zmeny vonkajšieho prostredia.

5.1. NÁSTROJE NA IMPLEMENTÁCIU

V záujme napĺňania vízie a cieľov stratégie PREŠOV 2030 bude potrebné uplatňovať kombináciu viacerých nástrojov - finančných aj nefinančných, vrátane aplikácie integrovaného prístupu. Bude nevyhnutné, aby samosprávy územia UMR Prešov vyčlenili potrebné zdroje, konkrétne:

- **ľudské zdroje,**
- **materiálne zdroje,**
- **finančné zdroje,**
- **informačné a komunikačné zdroje**.

Počas implementácie stratégie PREŠOV 2030 bude výber konkrétnych postupov, či nástrojov pre naplnenie stratégie podliehať posudzovaniu v zmysle nižšie uvedených kritérií:

- **efektívnosť a účinnosť** (ekonomické, ako aj mimoekonomické aspekty, miera relevantnosti voči cieľovým skupinám a pod.),
- **dostupnosť zdrojov** (ľudských, finančných, materiálnych a pod.),
- **udržateľnosť** (po ukončení implementácie),
- **rizikovosť** (riziká spojené s implementáciou),
- **synergie** (medzi nástrojmi naprieč stratégiou).

5.2. POSTUP PRI IMPLEMENTÁCII

Implementácia stratégie bude pozostávať z realizácie navrhovaných intervencií (konkrétnych rozvojových aktivít a projektov), ktoré budú realizované na území udržateľného mestského rozvoja s cieľom naplnenia cieľov, vízie a dosiahnutia udržateľného rozvoja v zadefinovaných prioritných oblastiach.
Počas prípravy strategického dokumentu bol zostavený zásobník rozvojových aktivít a projektov, ktorý obsahoval 293 rozvojových aktivít a projektov mesta Prešov a obcí na území

UMR Prešov. Zo zásobníka boli identifikované prioritné strategické aktivity a projekty, ktoré tvoria **Akčný plán PREŠOV 2030** (samostatná príloha k strategickému dokumentu).

Akčný plán PREŠOV 2030 predstavuje vykonávaciu časť strategického dokumentu - Spoločného programu hospodárskeho rozvoja a sociálneho rozvoja na území udržateľného mestského rozvoja Prešov na obdobie rokov 2023 - 2030 s výhľadom do roku 2035. Je spracovaný podľa prioritných rozvojových oblastí, strategických a špecifických cieľov. Zostavený je na obdobie troch rokov (n+2) a zahŕňa návrh konkrétnych rozvojových aktivít a projektov na uvedené obdobie. Pridanou hodnotou je ich vzájomná previazanosť a integrovanosť (tzv. integrované územné investície). **Základnou myšlienkou je integrácia aktivít a projektov v rôznych oblastiach tak, aby sa vzájomne podporili v ich príspevku k naplneniu cieľov stratégie a samotného investovania.**

Akčný plán PREŠOV 2030 reflektuje na aktuálnu situáciu v pripravenosti rozvojových aktivít a projektov, ktoré majú v akčnom pláne uvedeného nositeľa, indikatívny rozpočet, stav pripravenosti, merateľné ukazovatele a predpokladané zdroje financovania (vrátane financovania z Programu Slovensko). Stručný prehľad o počte navrhovaných intervencií v členení podľa prioritných oblastí poskytuje nižšie uvedená tabuľka 7.

Tabuľka 7 Počet intervencií UMR Prešov podľa priorít a tematických oblastí [34]

PRIORITA	ŠPECIFICKÝ CIEĽ	POČET INTERVENCIÍ*			
		Mesto Prešov	Obec Haniska	Obec Ľubotice	Obec Záborské
UDRŽATEĽNÉ A ODOLNÉ PROSTREDIE	ŠC 1.1.1 - Doprava	21	4	8	11
	ŠC 1.1.2 - Energetika	8	1	3	1
	ŠC 1.2.1 - Klíma	12	5	2	7
	ŠC 1.2.2 - Odpad	7	1	2	1
	SPOLU	**48**	**11**	**15**	**20**
SLUŽBY PRE DÔSTOJNÝ ŽIVOT	ŠC 2.1.1 - Vzdelávanie	7	1	2	1
	ŠC 2.1.2 - Práca	3	2	0	3
	ŠC 2.2.1 - Sociálne a zdravotnícke služby	6	0	4	1
	ŠC 2.2.2 - Šport	9	1	3	3
	ŠC 2.2.3 - Bezpečnosť	3	1	2	2
	SPOLU	**28**	**5**	**11**	**10**
STRATEGICKÝ ROZVOJ A DOBRÉ SPRAVOVANIE	ŠC 3.1.1 - Kapacity	4	0	0	0
	ŠC 3.1.2 - Digitalizácia	4	0	0	0
	ŠC 3.1.3 - Spolupráca	2	0	0	0
	ŠC 3.2.1 - Inovácie	1	0	0	0
	ŠC 3.2.2 - Kultúrny a kreatívny priem.	1	2	0	0
	ŠC 3.2.3 - Podnikanie	4	0	0	0
	SPOLU	**16**	**2**	**0**	**0**
CELKOVÝ POČET PROJEKTOV		**92**	**18**	**26**	**30**

** Intervencia = konkrétna rozvojová aktivita / projekt*

Implementácia stratégie bude zabezpečovaná jednotlivými samosprávami územia UMR Prešov v spolupráci so socio-ekonomickými partnermi. Kompetencie samosprávnych orgánov a iných stálych orgánov sú dané legislatívou, resp. štatútom Kooperačnej rady UMR Prešov. Hlavné úlohy samospráv vo vzťahu ku strategickému dokumentu:

[34] Vlastné spracovanie

- **Mestské a obecné zastupiteľstvá**
  - navrhujú spracovanie/aktualizáciu strategického dokumentu,
  - schvaľujú strategický dokument,
  - berú na vedomie správu o plnení strategického dokumentu,
  - schvaľujú finančné plány miest a obcí ako podklad pre spracovanie akčného a finančného plánu strategického dokumentu.

- **Mestské a obecné úrady**
  - zabezpečujú spracovanie/aktualizáciu strategického dokumentu,
  - vypracúvajú hodnotiacu správu o plnení strategického dokumentu,
  - vypracúvajú akčný a finančný plán k strategickému dokumentu,
  - aktualizujú akčný a finančný plán k strategickému dokumentu,
  - hľadajú finančné zdroje a zodpovedajú za prípravu a implementáciu projektov,
  - komunikujú s partnermi projektov, zástupcami Strategicko-plánovacieho regiónu (SPR) Šariš, Úradom Prešovského samosprávneho kraja, Ministerstva investícií, regionálneho rozvoja a informatizácie SR a ďalšími inštitúciami.

5.3. SYSTÉM MONITOROVANIA A HODNOTENIA

Monitorovanie a hodnotenie stratégie PREŠOV 2030 bude realizované podľa plánu monitorovania a hodnotenia, raz ročne. Mimoriadne hodnotenie bude možné realizovať na základe rozhodnutia Kooperačnej rady UMR Prešov, predovšetkým v prípade identifikovaného rizika alebo odklonu od stanovených cieľov.
Monitorovanie a hodnotenie sa bude realizovať **prostredníctvom súboru merateľných ukazovateľov**. Nosnými zdrojmi údajov pre ukazovatele budú samosprávy územia UMR Prešov, Centrálny register zmlúv, monitorovací systém ITMS a Štatistický úrad SR. Väčšina ukazovateľov bude sledovaná na ročnej báze. Merateľné ukazovatele majú definovaný počiatočný, resp. východiskový stav. V prípadoch, kde v súčasnosti nie je východisková hodnota merateľných ukazovateľov k dispozícii, (nakoľko sa jedná o indikátory, pre ktorých vyhodnocovanie nie sú aktuálne dostupné dáta - sú z kategórie zložitých dátových ukazovateľov), bude určená po prvom roku zberu, resp. po prvom období zberu podľa stanovenej frekvencie zberu dát. Následne bude nastavená aj cieľová hodnota. Merateľné ukazovatele plnia dve hlavné funkcie:

- **vyhodnocovanie úspešnosti stratégie** (v roku 2030, kedy majú byť ciele naplnené),
- **sledovanie priebehu realizácie v čase** (priebežný stav plnenia cieľa alebo realizácie jednotlivých aktivít smerujúcich k cieľu).

Samosprávy územia UMR Prešov budú realizovať monitorovanie a hodnotenie plnenia priorít a cieľov stratégie PREŠOV 2030 za svoje územie. Následne bude realizované aj spoločné monitorovanie a hodnotenie plnenia priorít a cieľov za celé územie UMR Prešov. Prehľad vybraných merateľných ukazovateľov vo vzťahu k plneniu cieľov stratégie PREŠOV 2030 tvorí súčasť Akčného plánu PREŠOV 2030.

Systém monitorovania a hodnotenia bude previazaný s programovými rozpočtami mesta Prešov a obcí. Bude využívať nástroje programového rozpočtovania najmä záverečný účet, ktorý je každoročne pripravovaný a schvaľovaný samosprávou.

V rámci procesu monitorovania bude prebiehať **zber a spracovanie dát** (hodnoty merateľných ukazovateľov, ako aj míľnikov), proces hodnotenia bude zameraný na **vyhodnocovanie získaných údajov.** Monitorovanie a hodnotenie strategického dokumentu PREŠOV 2030 bude previazané aj s monitorovaním a hodnotením nadradených strategických a programových dokumentov. Zodpovednosť za zber údajov a **spracovanie hodnotiacej správy** budú mať Administratívne kapacity UMR Prešov. Hodnotiaca správa bude mať písomnú formu (text, tabuľky, grafické prvky) a bude obsahovať zoznam informovaných subjektov.

Zameranie hodnotiacej správy bude primárne na nasledovné oblasti:

- úspešnosť plnenia priorít a cieľov pri implementácii stratégie,
- správnosť voľby nástrojov pre plnenie stratégie,
- faktory ovplyvňujúce napĺňanie cieľov, proces implementácie, alebo výsledky implementácie stratégie,
- odporúčania pre zlepšenie implementácie stratégie.

Hodnotiaca správa môže navrhnúť prípadnú aktualizáciu alebo spracovanie nového strategického dokumentu. Funkciu monitorovacieho a hodnotiaceho výboru bude plniť Kooperačná rada UMR Prešov. **Hodnotiaca správa bude predložená na prerokovanie Kooperačnej rade UMR Prešov, mestským a obecným zastupiteľstvám. Následne bude zverejnená.** Rámcový plán monitorovania, hodnotenia a aktualizácie stratégie PREŠOV 2030 je uvedený v tabuľke 8.

Tabuľka 8 Plán monitorovania, hodnotenia a aktualizácie stratégie PREŠOV 2030 [35]

Proces	Postup	Termín	Zodpovednosť	Schvaľovanie
Monitorovanie	**Zber údajov** - zber vybraných ukazovateľov vo väzbe k plneniu cieľov stratégie	**Raz ročne** (do 31.03. daného roku)	**AK UMR Prešov** (v súčinnosti s vecne príslušnými odb. útvarmi a inými relev. subjektmi)	
Hodnotenie	**Vyhodnotenie získaných údajov** **Spracovanie hodnotiacej správy**	**Raz ročne** (do 31.05. daného roku)	**AK UMR Prešov** (v súčinnosti s vecne príslušnými odb. útvarmi a inými relev. subjektmi)	**KR UMR Prešov** (schvaľovanie hodnotiacej správy)
Aktualizácia akčného plánu (vykonávacej časti stratégie)	**Aktualizácia** - na základe odporúčaní v hodnotiacej správe - na základe objektívnych skutočností	**Raz ročne** (do 31.07. daného roku)	**AK UMR Prešov** (v súčinnosti s vecne príslušnými odb. útvarmi, tematickými prac. skupinami a inými relev. subjektmi)	**KR UMR Prešov** (schvaľovanie aktualizácie akčného plánu)
Aktualizácia stratégie (strategickej a programovej časti stratégie)	**Aktualizácia** - na základe odporúčaní v hodnotiacej správe - na základe významných zmien (zmena UPN, legislatívne zmeny a iné)	**Najskôr po uplynutí obdobia n+2** (n = 2023)	**AK UMR Prešov** (v súčinnosti s Riadiacim tímom, tematickými prac. skupinami a inými relev. subjektmi)	**KR UMR Prešov** **MsZ mesta Prešov** **OcZ obcí UMR Prešov** (schvaľovanie aktualizácie stratégie)

Poznámka: Mimoriadne (v inom termíne) - na základe rozhodnutia Kooperačnej rady UMR Prešov v prípade novej spoločenskej situácie, rizika alebo odklonu od stanovených cieľov

[35] Vlastné spracovanie

Aktualizácia stratégie Prešov 2030 - ide o cyklický proces, ktorého cieľom je zachovať aktuálnosť strategického dokumentu, ako jeho flexibilitu vo vzťahu k dosahovaniu stanovených cieľov. Proces aktualizácie je založený na systematickom zbere podnetov verejnej správy, subjektov pôsobiacich na území mesta, občanov mesta a pod. Neoddeliteľnou súčasťou je aj sledovanie príležitostí, či ohrození pre rozvoj mesta, ako aj reagovanie na nové skutočnosti, ktoré neboli známe pri zostavovaní stratégie Prešov 2030. Zodpovednosť za proces aktualizácie nesie Útvar analýz a stratégií (ÚAaS) / Administratívne kapacity UMR Prešov. V súčinnosti s riadiacim tímom, tematickými pracovnými skupinami a inými relevantnými subjektmi pripraví odborné podklady pre aktualizáciu a zmenu rozvojového dokumentu.

5.4. ORGANIZAČNÉ ZABEZPEČENIE REALIZÁCIE STRATÉGIE

Organizačné zabezpečenie realizácie stratégie PREŠOV 2030 je základným predpokladom úspešnej realizácie aktivít, projektov a napĺňania cieľov vyšpecifikovaných v jednotlivých prioritných oblastiach rozvoja. **Nevyhnutná bude zainteresovanosť všetkých relevantných organizačných zložiek územných samospráv združených v UMR Prešov**, či organizácií s ich zriaďovateľskou pôsobnosťou a **prevzatie zodpovednosti** konkrétnych organizačných jednotiek/subjektov samosprávy na jej príslušných stupňoch riadenia a rozhodovania za napĺňanie aktivít, projektov a cieľov.

Základným koordinačným, metodickým a kontrolným centrom pre realizáciu stratégie PREŠOV 2030 **budú Administratívne kapacity UMR Prešov. Samosprávy, združené v rámci UMR Prešov, určia koordinátorov za jednotlivé rozvojové oblasti.** Povinnosti koordinátorov je možné rámcovo zhrnúť nasledovne:

- zodpovednosť za prípravu a realizáciu aktivít a projektov tematicky príslušnej časti stratégie,
- priebežný monitoring a vyhodnocovanie realizácie aktivít a projektov, výstupových ukazovateľov stratégie,
- navrhovanie aktualizácie akčného plánu, prípadne aktualizácie stratégie.

Výkonnou zložkou pre napĺňanie stratégie PREŠOV 2030 bude Realizačný tím, ktorý bude zostavený z nasledovných členov:

- vedúci pracovník AK UMR,
- vedúci Odboru rozvojových aktivít,
- koordinátori jednotlivých rozvojových oblastí.

6. FINANČNÁ ČASŤ

Jedným z kľúčových faktorov pre naplnenie stratégie PREŠOV 2030 je zabezpečenie finančného krytia na realizáciu rozvojových aktivít a projektov. Stratégia je vypracovaná v súlade so Zákonom č. 539/2008 Z.z. o podpore regionálneho rozvoja, ktorý možnosti financovania regionálneho rozvoja špecifikuje nasledovne:

- štátny rozpočet,
- štátne účelové fondy,
- rozpočty príslušných VÚC,
- rozpočty obcí,
- finančné prostriedky fyzických osôb,
- finančné prostriedky právnických osôb,
- finančné prostriedky vyplývajúce z medzinárodných zmlúv so SR,
- iné zdroje podľa osobitných predpisov,
- finančné prostriedky z fondov EÚ (doplnkový zdroj finančného zabezpečenia podpory regionálneho rozvoja).

Stratégia PREŠOV 2030 vychádza z predpokladu viaczdrojového financovania rozvojových aktivít a projektov, zameraných na plnenie cieľov stratégie. Okrem interných zdrojov - rozpočtov samospráv územia UMR Prešov, budú aktivity a projekty realizované aj z externých zdrojov (súkromných, verejných, návratných, nenávratných...) s možnosťou využitia rôznych finančných nástrojov. Stratégia PREŠOV 2030 sa špecificky orientuje na efektívne využitie možností financovania z prostriedkov EÚ v súlade s Partnerskou dohodou, Programom Slovensko a Plánom obnovy a odolnosti SR, no zahŕňa aj projekty financované z iných EÚ fondov (ESF+, ERASMUS+, PROGRAM INTERREG POĽSKO – SLOVENSKO, atď.) a finančných nástrojov EÚ.

Program Slovensko je významným zdrojom financovania rozvojových aktivít a projektov z fondov EÚ. Vytvára predpoklady pre kombináciu investícií z rôznych fondov a cieľov politiky súdržnosti **prostredníctvom integrovaných územných investícií** a takisto prostredníctvom ďalších samostatných **dopytovo orientovaných výziev**. Špecifikom citovaného programu je, že jednotlivé územia udržateľného mestského rozvoja, ako aj strategické plánovacie regióny budú mať vyčlenené vlastné alokácie zdrojov EFRR na realizáciu integrovaných územných investícií. Pre UMR Prešov je na zabezpečenie rozvoja územia v Programovom období 2021 - 2027 prostredníctvom integrovaných územných investícií v rámci vybraných opatrení navrhovaná suma cca 50 mil. €. O využití uvedených zdrojov v území, v súlade so stratégiou PREŠOV 2030, bude rozhodovať Kooperačná rada UMR Prešov, ktorej prislúcha kompetencia schvaľovania projektových zámerov. Zoznam intervencií (aktivít a projektov) na naplnenie cieľov a vízie stratégie PREŠOV 2030 s využitím zdrojov v rámci Programu Slovensko tvorí Prílohu č. 9.2 tohto dokumentu.

Špecifickým zdrojom na financovanie aktivít a projektov stratégie zo zdrojov EÚ je aj **Plán obnovy a odolnosti SR.** Príslušné ministerstvá budú presne stanoveným spôsobom vyhlasovať

výzvy s rôznym zameraním - pre UMR Prešov sú v súvislosti s napĺňaním stratégie relevantné výzvy zamerané na infraštruktúru vzdelávania (materské a základné školy), mestskú mobilitu (cyklodoprava), obnoviteľné zdroje energie (obnova verejných zdrojov a podpora zeleného verejného obstarávania) a reformy verejnej správy (digitalizácia verejných služieb a kybernetická bezpečnosť).

Programové obdobie EÚ 2021 - 2027 poskytuje viaceré príležitosti pre získanie finančných prostriedkov na rozvoj regiónov, miest a obcí i špecificky definovaných území akými sú územia UMR. V záujme efektívneho využitia uvedených **príležitostí bude nevyhnutné venovať zvýšenú pozornosť systematickej a efektívnej predprojektovej príprave a koordinácii prípravy a realizácie rozvojových projektov a integrovaných investícií.** Vysoká náročnosť bude kladená na procesy manažovania rozvoja územia, pre ktoré sú nevyhnutné kvalifikované ľudské zdroje a odborné kapacity.

Zjednodušený pohľad na indikatívny finančný plán UMR Prešov vo vzťahu k plneniu cieľov stratégie PREŠOV 2030, zostavený podľa prioritných oblastí rozvoja, poskytuje tabuľka 9. Je potrebné zdôrazniť, že mnohé projekty, ktoré tvoria súčasť uvedeného indikatívneho plánu sú nielen finančne, ale aj časovo veľmi náročné - ich realizácia, spolu s predprojektovou prípravou potrvá viac ako tri roky a je závislá na zabezpečení dostatočného finančného krytia. Finančne najnáročnejšiu skupinu projektov tvoria projekty zamerané na dopravnú infraštruktúru. V uvedenej oblasti sú nevyhnutné výrazné finančné intervencie nielen na regionálnej, ale aj na národnej úrovni.

Tabuľka 9 Indikatívny finančný plán stratégie PREŠOV 2030[36]

PRIORITA	ŠPECIFICKÝ CIEĽ	FINANČNÁ NÁROČNOSŤ PROJEKTOV				
		Mesto Prešov	Obec Haniska	Obec Ľubotice	Obec Záborské	SPOLU
UDRŽATEĽNÉ A ODOLNÉ PROSTREDIE	ŠC 1.1.1 - Doprava	110 285 288,17 €	3 160 000,00 €	5 737 898,88 €	10 047 000,00 €	**129 230 187,05 €**
	ŠC 1.1.2 - Energetika	12 108 163,61 €	80 000,00 €	1 700 000,00 €	1 200 000,00 €	**15 088 163,61 €**
	ŠC 1.2.1 - Klíma	14 007 799,48 €	2 220 000,00 €	250 000,00 €	3 640 000,00 €	**20 117 799,48 €**
	ŠC 1.2.2 - Odpad	6 512 086,84 €	100 000,00 €	350 000,00 €	50 000,00 €	**7 012 086,84 €**
	SPOLU	**142 913 338,10 €**	**5 560 000,00 €**	**8 037 898,88 €**	**14 937 000,00 €**	**171 448 236,98 €**
SLUŽBY PRE DÔSTOJNÝ ŽIVOT	ŠC 2.1.1 - Vzdelávanie	6 389 593,75 €	300 000,00 €	500 000,00 €	563 980,00 €	**7 753 573,75 €**
	ŠC 2.1.2 - Práca	1 183 489,31 €	250 000,00 €	0,00€	600 000,00 €	**2 033 489,31 €**
	ŠC 2.2.1 - Sociálne a zdravotnícke služby	7 015 610,00 €	0,00€	2 160 000,00 €	1 000 000,00 €	**10 175 610,00 €**
	ŠC 2.2.2 - Šport	30 001 813,34 €	500 000,00 €	1 056 000,00 €	812 000,00 €	**32 369 813,34 €**
	ŠC 2.2.3 - Bezpečnosť	1 435 037,72 €	60 000,00 €	450 000,00 €	270 000,00 €	**2 215 037,72 €**
	SPOLU	**46 025 544,12 €**	**1 110 000,00 €**	**4 166 000,00 €**	**3 245 980,00 €**	**54 547 524,12 €**
STRATEGICKÝ ROZVOJ A DOBRÉ SPRAVOVANIE	ŠC 3.1.1 - Kapacity	2 632 000,00 €	0,00€	0,00€	0,00€	**2 632 000,00 €**
	ŠC 3.1.2 - Digitalizácia	4 750 000,00 €	0,00€	0,00€	0,00€	**4 750 000,00 €**
	ŠC 3.1.3 - Spolupráca	1 800 000,00 €	0,00€	0,00€	0,00€	**1 800 000,00 €**
	ŠC 3.2.1 - Inovácie	0,00€	0,00€	0,00€	0,00€	**0,00€**
	ŠC 3.2.2 - Kultúrny a kreatívny priemysel	500 000,00 €	80 000,00 €	0,00€	0,00€	**580 000,00 €**
	ŠC 3.2.3 - Podnikanie	3 642 254,46 €	0,00€	0,00€	0,00€	**3 642 254,46 €**
	SPOLU	**13 324 254,46 €**	**80 000,00 €**	**0,00€**	**0,00€**	**13 404 254,46 €**
CELKOVÁ FINANČNÁ NÁROČNOŤ PROJEKTOV		**202 263 136,68 €**	**6 750 000,00 €**	**12 203 898,88 €**	**18 182 980,00 €**	**239 400 015,56 €**

[36] Vlastné spracovanie

Mesto Prešov a obce územia UMR Prešov budú zostavovať vlastný akčný aj finančný plán na daný rozpočtový rok s výhľadom na dva roky, priebežne bude monitorovaný, vyhodnocovaný a aktualizovaný. Zámerom je dosiahnuť kompatibilitu s programovými rozpočtami mesta Prešov a samospráv územia UMR Prešov. **Finančný plán stratégie PREŠOV 2030 schvaľuje mestské/obecné zastupiteľstvo v rámci schvaľovania rozpočtu mesta/obce.**
Finančný plán stratégie PREŠOV 2030 tvoria vzájomne koordinované finančné plány mesta a obcí územia UMR Prešov. Finančný plán implementácie stratégie identifikuje finančné objemy, charakter (grantové, revolvingové, investičné, neinvestičné aspekty), zdroje a spôsoby financovania projektov (vlastné zdroje, úverové zdroje, verejné financie, súkromné zdroje, grantové schémy, a pod.).

Stratégia PREŠOV 2030 ma aktuálne definovaných celkom **164 aktivít a projektov.** Viac ako polovica z nich (94 = 57,3%) je zadefinovaných v rámci Priority 1 - Udržateľné a odolné prostredie, pričom až 44 projektov je zameraných na dopravnú infraštruktúru. **Finančné požiadavky** - finančné zdroje, potrebné na realizáciu rozvojových aktivít a projektov, uvedených v Akčné pláne PREŠOV 2030, **predstavujú sumu 238,5 mil. €.** Z uvedenej čiastky viac ako polovicu tvoria dopravné projekty (128 mil. €), kde sú nevyhnutné aj výrazné intervencie na regionálnej úrovni (cesty II. a III. triedy) a aj na národnej úrovni (rýchlostné cesty, obchvaty a pod.). Z vlastných zdrojov samospráv združených v UMR Prešov bude na realizáciu rozvojových aktivít a projektov každoročne využívaná suma zodpovedajúca daným aktuálnym možnostiam a rozhodnutiam zastupiteľstiev v súlade s Akčným plánom Prešov 2030 a Programovými rozpočtami samospráv.

7. RIZIKÁ IMPLEMENTÁCIE A ICH PREVENCIA

Implementáciu stratégie PREŠOV 2030 môžu ovplyvniť viaceré riziká a nepredvídané udalosti:

- nedostatočná koordinácia na národnej a regionálnej úrovni;
- nízka efektívnosť strategického riadenia regionálneho rozvoja;
- nedostatočný legislatívny a metodický rámec;
- nedostatočná efektívnosť a adresnosť verejných politík vrátane politiky regionálneho rozvoja (NSRR, PHRSR VÚC, miest a obcí),
- nízka súčinnosť s aktérmi regionálneho rozvoja pri tvorbe a implementácii stratégií regionálneho rozvoja,
- nedostatočná spolupráca a informačné toky medzi riadiacimi úrovňami (štátna - krajská - subregionálna - miestna) a sektormi (ministerstvá - rezortné inštitúcie - odborné útvary samospráv,
- nedostatok údajov, finančných a personálnych kapacít pre spracovanie a implementáciu stratégie a pod.).

Pri tvorbe strategického dokumentu bol spracovaný **Plán riadenia rizík** - viď tabuľka 10. V uvedenom pláne boli identifikované kľúčové problémy, ktoré môžu negatívne ovplyvniť napĺňanie cieľov a vízie stratégie PREŠOV 2030. Plán obsahuje navrhované opatrenia na eliminácia rizík, vrátane zodpovednosti a termínov na plnenia navrhovaných opatrení. Proces riadenia rizík (identifikáciu a hodnotenie rizík, prerokovanie a aktualizácia plánu rizík) budú zabezpečovať Administratívne kapacity UMR Prešov v úzkej súčinnosti s pracovníkmi mestských a obecných úradov. Plán rizík minimálne raz ročne prerokuje Riadiaci výbor UMR a následne s ním bude oboznámená Koordinačná rada UMR.

Tabuľka 10 Plán riadenia rizík PHRSR UMR Prešov[37]

Popis rizika	Opatrenia na zníženie rizík	Zodpovednosť	Termín
Absencia / nedostatok odborných kapacít na implementáciu PREŠOV 2030	**Dobudovať administratívne kapacity UMR Prešov** (AK UMR), t.j. zabezpečiť pracovné pozície (vedúci pracovník AK UMR - manažér; odborný referent AK UMR - koordinátor a metodik UMR; odborný referent AK UMR - analytik UMR) materiálno-technické podmienky a priebežné vzdelávanie.	Vedenie jadrového mesta Prešov	31.12.2023
Nedostatok finančných zdrojov na implementáciu PREŠOV 2030	**Pripraviť viacročný investičný plán** - Akčný plán s priorizáciou investícií. Aktívne vyhľadávať a priorizovať využitie externých finančných prostriedkov. Identifikovať významné projekty, ktoré je možné realizovať na princípe verejno-súkromného partnerstva, iniciovať rokovania s potenciálnymi partnermi.	Vedenie jadrového mesta Prešov	30.04.2024
Nedostatok informácií spojených s efektívnou implementáciou PREŠOV 2030 (metodický rámec MIRRI SR, údaje o území a pod.)	**Aktívne komunikovať** s odbornými pracovníkmi MIRRI SR, PSK, SPR Šariš). **Vytvoriť informačný systém** a dátové súbory UMR Prešov, vrátane pravidelnej aktualizácie.	Administratívne kapacity UMR Prešov	Priebežne
Nízka súčinnosť s aktérmi regionálneho rozvoja pri implementácii PREŠOV 2030	**Realizovať stretnutia s kľúčovými aktérmi regionálneho rozvoja** v území s cieľom vzájomnej informovanosti a realizácie spoločných projektov.	Administratívne kapacity UMR Prešov	Priebežne

[37] Vlastné spracovanie

8. ODPORÚČANIA A POŽIADAVKY

Odporúčania a požiadavky pre nadradené a nižšie úrovne strategického riadenia a pre partnerské a spolupracujúce subjekty.

1. Vytvoriť Administratívne kapacity UMR Prešov na MsÚ v Prešove (Útvar analýz a stratégií, úsek Administratívne kapacity UMR).
2. Vytvoriť systém na zber, uchovávanie, hodnotenie a sprístupňovanie údajov pre rozhodovanie samosprávy. Systém nastaviť tak, aby prebiehal v maximálnej miere automaticky s väzbou na vlastný informačný systém samosprávy.
3. Vytvoriť databázu strategických a koncepčných dokumentov na úrovni UMR Prešov.
4. Koordinovať rozvojové aktivity a projekty územia UMR Prešov s SPR Šariš a PSK.
2. Podporovať spoločné projekty samosprávy a socio-ekonomických partnerov, spoločných projektov území UMR v SR.
3. Realizovať pravidelné stretnutia socio-ekonomických partnerov v rámci územia UMR Prešov s cieľom zlepšenia informovanosti a realizácie spoločných aktivít a projektov.
4. Zabezpečiť personálne kapacity pre zabezpečenie participácie a spolupráce pri realizácii integrovaných územných investícií.

9. PRÍLOHY

9.1. VYHODNOTENIE STRATEGICKÝCH DOKUMENTOV

Zahájeniu prípravy nového strategického dokumentu pre programové obdobie 2021 - 2027 predchádzalo vyhodnotenie implementácie existujúceho Programu rozvoja mesta Prešov (PRM) na roky 2015 - 2020 s výhľadom do roku 2025 a vyhodnotenie strategických dokumentov obcí územia udržateľného mestského rozvoja Prešov.

1.1.1. PHSR HANISKA - VYHODNOTENIE

Obec Haniska si v rámci Programu hospodárskeho a sociálneho rozvoja na roky 2015 - 2023 stanovila **3 prioritné oblasti** rozvoja obce: EKONOMICKO - HOSPODÁRSKA OBLASŤ, SOCIÁLNA OBLASŤ a ENVIRONMENTÁLNA OBLASŤ. Za účelom naplnenia vízie obce boli sformulované **3 strategické ciele** a **9 opatrení**. Na naplnenie stanovených cieľov a opatrení bolo zadefinovaných **14 aktivít**. Obec na ich realizáciu získala zo štátnych zdrojov 167 796 €, európske fondy zafinancovali projekty v objeme vyše 500-tisíc €. Viac informácií - viď. tabuľka 11.

Tabuľka 11 Vyhodnotenie PHSR obce Haniska 2015 - 2022 [38]

Program hospodárskeho a sociálneho rozvoja obce Haniska 2015 - 2022 VYHODNOTENIE PLNENIA								
Opatrenie	**Názov aktivity**	**Hlavný ukazovateľ**	**Termín ukončenia**	**Vlastné zdroje**	**EÚ zdroje**	**Štátne zdroje**	**Súkromné zdroje**	**Úver**
Opatrenie 1.1	Podpora rozvoja podnikateľských aktivít	Počet podporených akcií - 2	2015 - 2017	1 000 €				
Opatrenie 1.2	Rekonštrukcia a modernizácia VO	Nové body verejného osvetlenia - 11	2015 - 2022	11 390 €				
	Rekonštrukcia interiéru OcÚ	Zrekonštruovaný interiér	2015 - 2022	25 720 €		2 248 €		
	Rekonštrukcia miestnych komunikácií a chodníkov	Metre komunikácií 360 m	2015 - 2022	150 920 €				
	Rozšírenie obecného rozhlasu	Nové body napojenia		-	-	-	-	-
	Rozšírenie kanalizácie	Novo napojení 109	2015 - 2022	66 026 €	500 477 €	55 967 €		
Opatrenie 1.3	Rozvoj partnerskej spolupráce	Podporené partnerské projekty - 2	2015 - 2021	500 €				
Opatrenie 2.	Rekonštrukcia MŠ	Zrekonštruovaný exteriér a interiér	2015 - 2022	2 990 €			1 000 €	
Opatrenie 2.1.	Rozšírenie kamerového systému	Počet kamier - 11	2015 - 2022	3 591 €		10 000 €		
Opatrenie 2.2	Podpora kultúrnych a športových podujatí	Počet akcií 15/ 2 publikácie	2015 - 2022	8 300 €		7 200 €	2 500 €	
Opatrenie 2.3.	Podpora chránenej dielne	Počet pracovných miest - 2	2015 - 2022			27 565 €		

[38] Vyhodnotenie PHSR obce Haniska 2015 - 2022, Obec Haniska, k 07. 12. 2022

Opatrenie 2.3	Podpora nezamestnanosti cez projekty Úradu práce	Počet pracovných miest - 8	2015 - 2019			26 816 €		
Opatrenie 3.1.	Protipovodňové aktivity - výstavba HZ	Akcie - 5	2015 - 2022	27 450 €		30 000 €		
Opatrenie 3.2.	Rozšírenie zelených priestranstiev	40 m2	2015 - 2020	876 €		8 000 €		

1.1.2. PHSR OBCE ĽUBOTICE NA OBDOBIE 2015 - 2023 – VYHODNOTENIE

Program hospodárskeho a sociálneho rozvoja obce Ľubotice na obdobie 2015 - 2023 (ďalej len „PHSR“), strednodobý strategický dokument, bol vypracovaný v súlade so zákonom NR SR č. 309/2014, ktorým sa mení a dopĺňa zákon č. 539/2008 Z.z. o podpore regionálneho rozvoja. Obecné zastupiteľstvo schválilo PHSR obce Ľubotice na obdobie 2015 - 2023 na svojom riadnom zasadnutí dňa 13. 06. 2016 uznesením č. 6/5/2016.

PHSR obce Ľubotice na obdobie 2015 - 2023 predstavuje strednodobý strategický dokument. V dokumente boli zadefinované **tri prioritné oblasti**: HOSPODÁRSTVO, SOCIÁLNA OBLASŤ a ŽIVOTNÉ PROSTREDIE, v rámci ktorých boli vyšpecifikované **3 globálne ciele** a **3 špecifické ciele**. Na základe identifikovaných potrieb, východísk a možných riešení boli **4 opatrenia** rozpracované do **18 aktivít**, ktorých realizácia prispela k dosiahnutiu želaného stavu v obci. Z celkového počtu 18 aktivít bolo **splnených 9 aktivít**, **7 aktivít bolo čiastočne splnených** a **v procese prípravy sú 2 aktivity**. Rámcový prehľad plnenia stanovených aktivít poskytuje nižšie uvedená tabuľka 12 a graf 1.

Tabuľka 12 Sumárne vyhodnotenie PHSR obce Ľubotice na obdobie 2015 - 2023 [39]

P.č.	Prioritná oblasť	Rámcový počet aktivít	Splnené	Čiastočne splnené	V procese prípravy
1	HOSPODÁRSTVO	5	2	3	0
2	SOCIÁLNA OBLASŤ	9	3	4	2
3	ŽIVOTNÉ PROSTREDIE	4	4	0	0
SPOLU		**18**	**9**	**7**	**2**

Graf 1 Vyhodnotenie plnenia PHRSR obce Ľubotice podľa prioritných oblastí [40]

[39] Vyhodnotenie Programu hospodárskeho a sociálneho rozvoja obce Ľubotice na obdobie 2015 - 2023, obec Ľubotice, k 29.11.2022
[40] Vyhodnotenie Programu hospodárskeho a sociálneho rozvoja obce Ľubotice na obdobie 2015 - 2023, obec Ľubotice, k 29.11.2022

Detailnejší prehľad plnenia PHSR obce Ľubotice podľa prioritných oblastí poskytuje tabuľka 13.

Tabuľka 13 Hodnotenie plnenia prioritných oblastí obec Ľubotice [41]

Prioritná oblasť HOSPODÁRSTVO				
Opatrenie 1.1.1.: Investície do motorovej a nemotorovej dopravnej infraštruktúry a s tým súvisiacich služieb				
1.1.1.1: Vybudovanie cyklistického chodníka Ľubotice – Prešov, vrátane cyklostojanov a doplnkovej infraštruktúry	2016-2023	Čiastočne splnené	I. etapa ukončená	Rozpočet obce
1.1.1.2: Rekonštrukcia miestnych komunikácií a chodníkov	2016-2023	Splnené	Každoročná realizácia opráv miestnych komunikácií a chodníkov	Rozpočet obce
1.1.1.3: Výstavba novej komunikácie	2017-2022	Čiastočne splnené	MK4 a MK5 – stav realizácie - v procese územného konania	Rozpočet obce
1.1.1.4: Vybudovanie parkovacích miest	2016-2019	Splnené		Rozpočet obce
1.1.1.5: Rekonštrukcia a rozšírenie mostov a lávok	2016-2022	Čiastočne splnené	Zrealizované mosty na Šalgovíckej a Pod Hájom, v procese prípravy mosty na Makarenkovej, Roľníckej a Gagarinovej	Rozpočet obce
Prioritná oblasť SOCIÁLNA				
Opatrenie 2.1.1: Investície do infraštruktúry súvisiacej s bezpečnosťou				
2.1.1.1: Rozšírenie a rekonštrukcia miestneho rozhlasu	2017-2020	Čiastočne splnené		Rozpočet obce
2.1.1.2: Inštalácia kamerového systému	2016-2020	Čiastočne splnené	Realizované pri Športovom areáli a pri Obecnom úrade	Rozpočet obce
2.1.1.3: Rekonštrukcia a rozšírenie verejného osvetlenia	2016-2020	Splnené		Rozpočet obce
Opatrenie 2.1.2: Investície do sociálnej infraštruktúry a služieb				
2.1.2.1: Zriadenie denného stacionára	2016-2022	Splnené		Rozpočet obce
2.1.2.2: Zateplenie ZŠ a úprava areálu, vrátane oplotenia	2017-2021	Splnené		Rozpočet obce
2.1.2.3: Vybudovanie oddychovej zóny s prvkami drobnej infraštruktúry	2016-2019	Čiastočne splnené	Vybudovanie oddychovej zóny na Makarenkovej ulici pri dennom stacionári	Prostriedky EÚ + Rozpočet obce
2.1.2.4: Vybudovanie multifunkčného ihriska s outdorovými prvkami	2017-2021	Čiastočne splnené	Vybudovanie workoutového ihriska na Makarenkovej ulici pri dennom stacionári	Prostriedky EÚ + Rozpočet obce
2.1.2.5: Výstavba Domu nádeje	2017-2022	V procese prípravy	Výber vhodnej lokality	Rozpočet obce
2.1.2.6: Zriadenie vzdelávacieho zariadenia	2017-2022	V procese prípravy		Rozpočet obce

[41] Vyhodnotenie Programu hospodárskeho a sociálneho rozvoja obce Ľubotice na obdobie 2015 – 2023, obec Ľubotice, k 29.11.2022

Prioritná oblasť ŽIVOTNÉ PROSTREDIE				
Opatrenie 3.1.1: Investície do environmentálnej a zelenej infraštruktúry				
3.1.1.1: Výsadba miestnej zelene, sadové úpravy na verejných priestranstvách	2016-2019	Splnené		Rozpočet obce
3.1.1.2: Budovanie zelenej infraštruktúry	2016-2019	Splnené		Rozpočet obce
3.1.1.3: Rekonštrukcia a oprava studne	2016-2018	Splnené		Rozpočet obce
3.1.1.4: Zvýšenie úrovne separovania komunálneho odpadu v časti Pod Hájom	2016-2018	Splnené		Rozpočet obce

1.1.3. PROGRAM ROZVOJA MESTA PREŠOV – VYHODNOTENIE

Program rozvoja mesta Prešov na roky 2015 - 2020 s výhľadom do roku 2025 (PRM Prešov) vyšpecifikoval **8 nosných programových, resp. rozvojových oblastí** - ekonomický rozvoj; doprava; životné prostredie; bezpečnosť; sociálna starostlivosť; výchova a vzdelávanie detí a mládeže; kultúra, šport, cestovný ruch a efektívne spravovanie. Zadefinovaných bolo **11 strategických cieľov a 41 opatrení,** zameraných na plnenie stanovených cieľov.

Nad rámec zákona č. 539/2008 Z. z. o podpore regionálneho rozvoja bol spracovaný Akčný plán PRM Prešov, ktorý špecifikoval celkom **201 plánovaných aktivít/projektov**, z nich bolo **naplnených 131 aktivít/projektov**, **55 aktivít/projektov sa priebežne a kontinuálne plní a 15 aktivít/projektov nebolo naplnených k 30.06.2020.** Je potrebné konštatovať, že mnohé aktivity/projekty v rámci jednotlivých programových oblastí mali kontinuálne nastavenie plnenia (revitalizácia vnútroblokov sídlisk, revitalizácia verejných priestranstiev, eliminácia bariér, zapájanie dobrovoľníkov, skvalitňovanie e-Governmentu, spracovanie špecifických strategických dokumentov a koncepcií, revitalizácia detských ihrísk a športovísk a pod.), resp. plnenie niektorých aktivít/projektov bolo závislé od získania externých zdrojov a s tým súvisiacich procesov (projektová príprava, procesy spojené s verejným obstarávaním, procesy hodnotenia a zazmluvňovania projektov, procesy spojené s kontrolnou činnosťou a pod.). Rámcový prehľad plnenia stanovených aktivít/projektov poskytuje nižšie uvedená tabuľka 14, graf 2 a graf 3.

Tabuľka 14 Vyhodnotenie PRM mesta Prešov 2015 - 2020 s výhľadom do roku 2025[42]

P.č.	Programová oblasť	Rámcový počet aktivít/projektov	splnené	priebežné plnenie	nesplnené
1	EKONOMICKÝ ROZVOJ MESTA	9	5	2	2
2	DOPRAVA	38	21	17	0
3	ŽIVOTNÉ PROSTREDIE	35	18	15	2
4	BEZPEČNOSŤ	16	13	2	1
5	SOCIÁLNA STAROSTLIVOSŤ	27	21	4	2
6	VÝCHOVA A VZDELÁVANIE DETÍ A MLÁDEŽE	28	22	3	3
7	KULTÚRA, ŠPORT, CESTOVNÝ RUCH	37	26	8	3
8	EFEKTÍVNE SPRAVOVANIE	11	5	4	2
Spolu		**201**	**131**	**55**	**15**

[42] Vyhodnotenie PRM mesta Prešov 2015 – 2020 s výhľadom do roku 2025 k 30. 06. 2020, Mesto Prešov, vlastné spracovanie

Graf 2 Vyhodnotenie plnenia aktivít/projektov PRM Prešov podľa prioritných oblastí [43]

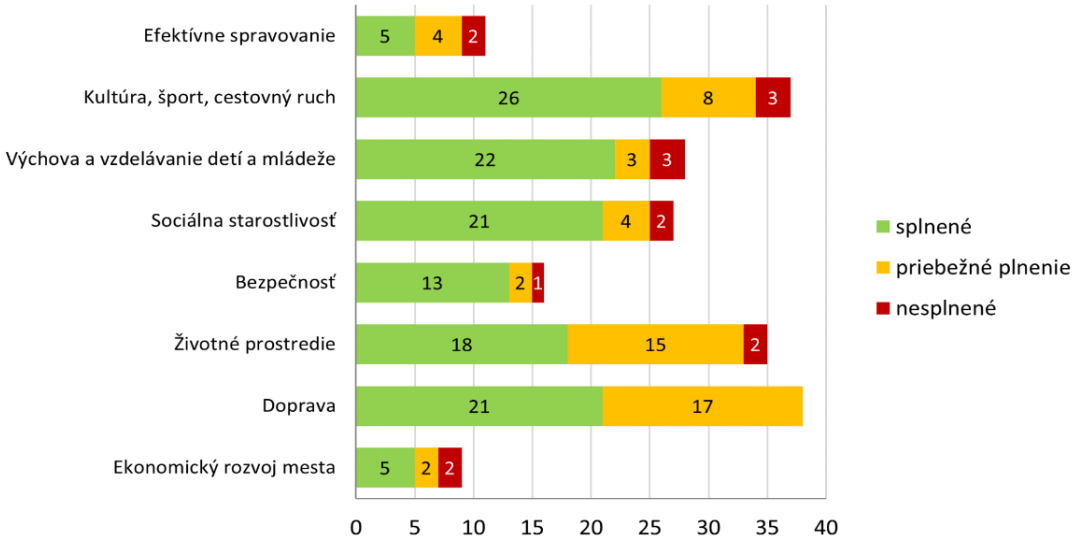

Graf 3 Vyhodnotenie plnenia aktivít/projektov PRM podľa stavu naplnenia [44]

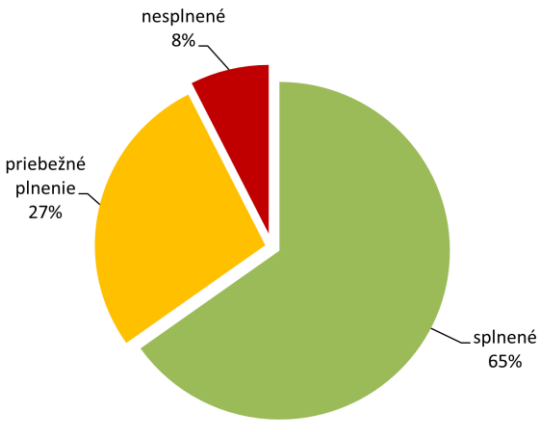

Proces vyhodnotenia PRM zabezpečoval Odbor riadenia projektov, ktorý z podkladov príslušných odborných útvarov Mestského úradu v Prešove zostavil vyhodnotenie k **30.06.2020** za každú programovú oblasť jednotlivo. Integrálnou súčasťou procesu vyhodnocovania strategického dokumentu bolo aj jeho **verejné prerokovanie** uskutočnené dňa 16.09.2020 a **oboznámenie Mestského zastupiteľstva mesta Prešov** s jeho výstupom dňa 23.09.2020 v rámci 16. zasadnutia mestského zastupiteľstva mesta Prešov.

Detailné vyhodnotenie Programu rozvoja mesta Prešov na roky 2015 - 2020 s výhľadom do roku 2025 (textová časť + prezentácia vybraných výstupov) je zverejnená na stránke mesta Prešov, link: https://www.presov.sk/prm-presov-2015-2020-0.html.

[43] Vyhodnotenie PRM mesta Prešov 2015 – 2020 s výhľadom do roku 2025 k 30. 06. 2020, Mesto Prešov, vlastné spracovanie

[44] Vyhodnotenie PRM mesta Prešov 2015 – 2020 s výhľadom do roku 2025 k 30. 06. 2020, mesto Prešov, vlastné spracovanie

9.1.4. PHRSR OBCE ZÁBORSKÉ NA ROKY 2015 - 2025 - VYHODNOTENIE

Program hospodárskeho a sociálneho rozvoja obce Záborské na roky 2015-2025 mal zadefinovanú víziu rozvoja nasledovne: „Obec Záborské - regionálne centrum vidieckeho cestovného ruchu so spokojným a aktívnym obyvateľstvom vo vysokokvalitnom životnom prostredí, obec zabezpečujúca kvalitné služby pre obyvateľov i návštevníkov obce.“

Obec mala zadefinovaných **5 strategických rozvojových oblastí** - Trvalo udržateľný ekonomický rozvoj obce; Investície do občianskej infraštruktúry obce; Investície do dopravnej a technickej infraštruktúry obce; Rozvoj bývania a rast počtu obyvateľstva obce; Ochrana životného prostredia.

Tabuľka 15 Vyhodnotenie Programu PHSR obce Záborské na roky 2015 - 2025[45]

P.č.	Prioritná oblasť	Rámcový počet aktivít	splnené	priebežné plnenie	nesplnené
1	TRVALO UDRŽATEĽNÝ EKONOMICKÝ ROZVOJ OBCE	9	4	4	1
2	INVESTÍCIE DO OBČIANSKEJ INFRAŠTRUKTÚRY OBCE	16	13	2	1
3	INVESTÍCIE DO DOPRAVNEJ A TECHNICKEJ INFRAŠTRUKTÚRY OBCE	12	8	3	1
4	ROZVOJ BÝVANIA A RAST POČTU OBYVATEĽSTVA OBCE	5	3	1	1
5	OCHRANA ŽIVOTNÉHO PROSTREDIA	7	4	2	1
Spolu		**49**	**32**	**12**	**5**

Graf 4 Vyhodnotenie plnenia PHRSR obce Záborské podľa prioritných oblastí[46]

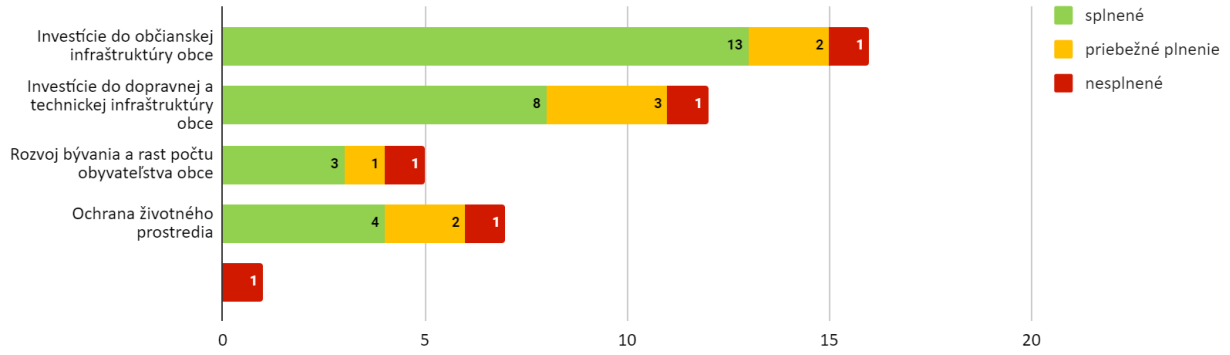

V čase vyhodnocovania strategického dokumentu sa obci Záborské podarilo z plánovaného počtu **49 aktivít/projektov zrealizovať 28 aktivít/projektov, 8 aktivít/projektov sa priebežne plní.** Zrealizované boli aktivity/projekty v hodnote viac ako 5 mil. €). Priebežné napĺňanie aktivít v rámci prioritných oblastí rozvoja je popísané v nižšie uvedenom texte.[47]

[45] Vyhodnotenie Programu hospodárskeho a sociálneho rozvoja obce Záborské na roky 2015 - 2025, obec Záborské, k 30.6.2020

[46] Vyhodnotenie plnenia PHRSR obce Záborské podľa prioritných oblastí, obec Záborské, k 30.6.2020

[47] Vyhodnotenie plnenia PHRSR obce Záborské podľa prioritných oblastí, obec Záborské, k 30.6.2020

1. TRVALO UDRŽATEĽNÝ EKONOMICKÝ ROZVOJ OBCE

plán: 2 ciele / 2 opatrenia / 9 aktivít

Graf 5 Trvalo udržateľný ekonomický rozvoja obce

- Informačný navigačný systém v obci
- Nová webová stránka
- Informačné brožúry
- Rozširovanie priemyselného parku
- Spolupráca s regionálnymi združeniami v oblasti cestovného ruchu
- Vytvorenie pracovných miest v rámci aktivačných prác
- Vzdelávacie programy pre zamestnancov

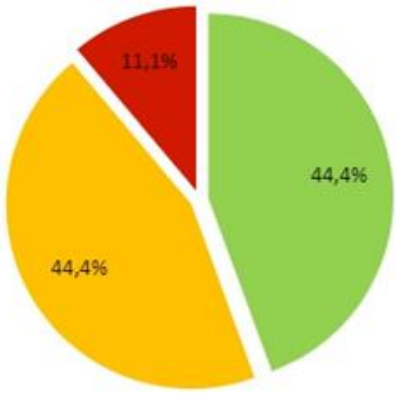

2. INVESTÍCIE DO OBČIANSKEJ INFRAŠTRUKTÚRY OBCE

plán: 4 ciele / 4 opatrenia / 16 aktivít

Graf 6 Investície do občianskej infraštruktúry obce

- Športové centrum Záborské
- Výstavba detského ihriska Rodinka
- Vybavenie detského ihriska v parku
- Kamerový systém Záborské
- Merače rýchlosti
- Poradenstvo v predškolskej, sociálnej a kultúrnej oblasti
- Koordinovanie poskytovania sociálnej pomoci v obci
- Zriadenie Denného stacionára Haršačanik
- Úprava hasičskej zbrojnice
- Organizovanie rôznych kultúrnych podujatí výročie obce, folklórne vystúpenia, deň detí, matiek, mesiac úcty k starším, čítanie v knižnici, Mikuláš, fašiangová zábava...)

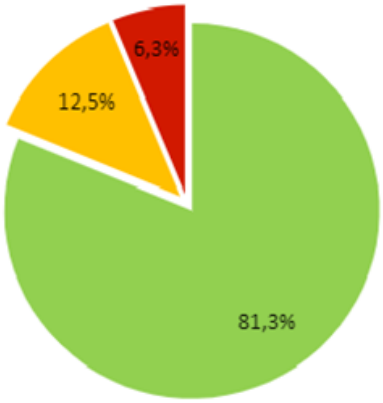

3. INVESTÍCIE DO DOPRAVNEJ A TECHNICKEJ INFRAŠTRUKTÚRY OBCE

plán: 4 ciele / 4 opatrenia / 12 aktivít

Graf 7 Investície do dopravnej a technickej infraštruktúry obce

- Rekonštrukcia miestnych komunikácií a chodníkov
- Výstavba chodníka okolo štátnej cesty
- Rekonštrukcia betónového priepustu
- Príprava projektovej dokumentácia na cyklistickú infraštruktúru
- Rekonštrukcia verejného osvetlenia
- Rekonštrukcia miestneho rozhlasu
- Kanalizácia a Rozšírenie vodovodu
- Rekonštrukcia MŠ Včielky

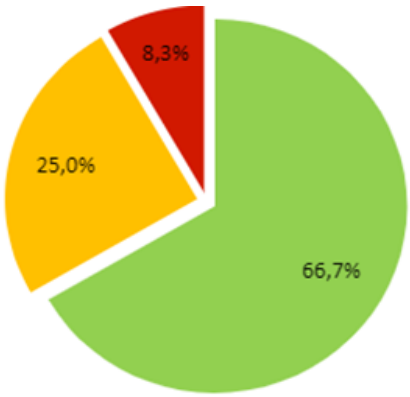

4. *ROZVOJ BÝVANIA A RAST POČTU OBYVATEĽSTVA OBCE*

plán: 2 ciele / 3 opatrenia / 5 aktivít

Graf 8 Rozvoj bývania a rast počtu obyv. obce

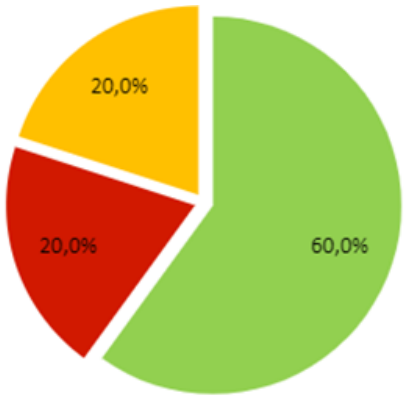

- Aktualizácia územného plánu a zón
- Pozemkové úpravy/spoločné zariadenia – projektová dokumentácia
- Orientačné tabule
- Úprava parku, drobná architektúra (preliezky pre deti, lavičky, stojan na bicykel, altánok...)
- Malé detské ihrisko

5. *OCHRANA ŽIVOTNÉHO PROSTREDIA*

plán: 1 cieľ / 3 opatrenia / 7 aktivít

Graf 9 Ochrana životného prostredia

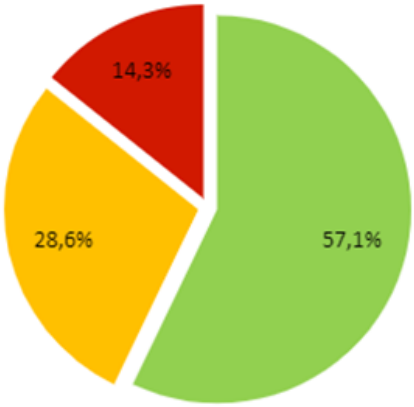

- Vybudovanie kanalizácie
- Separácia odpadu vrátane osvety
- Kompostáreň Záborské
- Likvidácia miestnych čiernych skládok vrátane prevencie - veľkoplošné kontajnery
- Revitalizácia parčíka a revitalizácia zelene - PD
- Ochrana pred povodňami - projektová dokumentácia
- Čiastočná sanácia svahu
- Úprava potoka a rigolu
- Adaptácia na zmenu klímy - spracovanie strategického dokumentu (Program rozvoja obce Záborské pred lokálnymi záplavami, zosuvmi, suchom a na ozdravovanie klímy katastra obce)

9.2. ZOZNAM INTERVENCIÍ (AKTIVÍT A PROJEKTOV) NA NAPLNENIE CIEĽOV A VÍZIE STRATÉGIE PREŠOV 2030 S VYUŽITÍM ZDROJOV V RÁMCI PROGRAMU SLOVENSKO

Tabuľka 16 Zoznam intervencií (aktivít a projektov) na naplnenie cieľov a vízie stratégie PREŠOV 2030 s využitím zdrojov v rámci Programu Slovensko

PROGRAM SLOVENSKO		zdroj EFRR	PROJEKTY UMR Prešov			
Kód opatrenia	Názov opatrenia		Názov projektu	Finančná náročnosť	Nositeľ projektu	Väzba na spoločný PHRSR UMR Prešov
1.1.1	Podpora medzisektorovej spolupráce v oblasti výskumu, vývoja a inovácií a zvyšovanie výskumných a inovačných kapacít v podnikoch	1 801 558,36	MIS - Mestská inovačná stratégia	200 000,00 €	Mesto Prešov	**P3**, SC - 3.1, ŠC - 3.1.1
			MIP Prešov	1 600 000,00 €	Mesto Prešov	**P3**, SC - 3.1, ŠC - 3.1.1
1.2.2	Podpora budovania inteligentných miest a regiónov	3 524 788,09	Zavádzanie IoT smart riešení v meste Prešov	4 000 000,00 €	Mesto Prešov	**P3**, SC - 3.1, ŠC - 3.1.2
			Informačný systém na komplexnú správu analytických dát	550 000,00 €	Mesto Prešov	**P3**, SC - 3.1, ŠC - 3.1.2
1.4.1	Zručnosti pre posilnenie konkurencieschopnosti a hospodárskeho rastu a budovanie kapacít pre SK RIS3	7 832,86	Teória v praxi - projekt študentských stáží na MsÚ	7 500,00 €	Mesto Prešov	**P3,** SC - 3.1, ŠC - 3.1.3
2.1.2	Znižovanie energetickej náročnosti budov	2 627 200,57	Rekonštrukcia objektu Kino Scala v Prešove	4 830 171,00 €	Mesto Prešov	**P1**, SC - 1.1, ŠC - 1.1.2
			ZUŠ Októbrová - znižovanie energetickej náročnosti	1 300 000,00 €	Mesto Prešov	**P1**, SC - 1.1, ŠC - 1.1.2
			ZŠ Čsl. Armády - elokované pracovisko ZŠ Odborárska - znižovanie energetickej náročnosti	800 000,00 €	Mesto Prešov	**P1**, SC - 1.1, ŠC - 1.1.2
			Hasičská zbrojnica DHZ Prešov	700 000,00 €	Mesto Prešov	**P1**, SC - 1.1, ŠC - 1.1.2
2.2.2	Podpora využívania OZE v systémoch zásobovania energiou	399 774,10	MŠ Bajkalská	199 227,00 €	Mesto Prešov	**P1**, SC - 1.1, ŠC - 1.1.2
			MŠ Važecká	179 590,00 €	Mesto Prešov	**P1**, SC - 1.1, ŠC - 1.1.2
			ZŠ Majové námestie	199 323,18 €	Mesto Prešov	**P1**, SC - 1.1, ŠC - 1.1.2
			ZŠ Mirka Nešpora	199 852,43 €	Mesto Prešov	**P1**, SC - 1.1, ŠC - 1.1.2
2.4.1	Vodozádržné opatrenia na adaptáciu na zmenu klímy v sídlach a krajine a /alebo ochranu pred povodňami	4 076 299,93	Výstavba suchých poldrov - mesto Prešov		Mesto Prešov	**P1**, SC - 1.2, ŠC - 1.2.1
			Polder - Zadržanie vody v obci s vytvorením odd. zóny	400 000,00 €	Obec Záborské	**P1**, SC - 1.2, ŠC - 1.2.1
2.5.3	Podpora infraštruktúry v oblasti nakladania s komunálnymi odpadovými vodami v aglomeráciách do 2 000 EO v dobiehajúcich regiónoch	718 451,61				**P1**, SC - 1.2, ŠC - 1.2.1
2.5.5	Zabezpečenie prístupu k pitnej vode a nakladania s komunálnymi odpadovými vodami v obciach do 2 000 EO v dobiehajúcich regiónoch	344 856,77	Rozšírenie vodovodu	200 000,00 €	Obec Haniska	**P1**, SC - 1.2, ŠC - 1.2.1
			Rozšírenie kanalizácie obce Haniska	1 200 000,00 €	Obec Haniska	**P1**, SC - 1.2, ŠC - 1.2.1
2.5.7	Obnova verejnej stokovej siete a čistiarní odpadových vôd v aglomeráciách nad 2 000 EO	405 742,27	Rekonštrukcia ČOV v ZpS Harmónia - ZpS Cemjata	390 000,00 €	Mesto Prešov	**P2**, SC - 2.2, ŠC - 2.2.1
2.6.1	Podpora vybraných aktivít v oblasti predchádzania vzniku odpadov	154 703,50				**P1**, SC - 1.2, ŠC - 1.2.2

PROGRAM SLOVENSKO		zdroj EFRR	PROJEKTY UMR Prešov			
Kód opatrenia	Názov opatrenia		Názov projektu	Finančná náročnosť	Nositeľ projektu	Väzba na spoločný PHRSR UMR Prešov
2.6.2	Podpora zberu a dobudovania, intenzifikácie a rozšírenia systémov triedeného zberu komunálnych odpadov	1 379 363,86	Transformačné centrum odpadov	4 000 000,00 €	Mesto Prešov, TSmP a.s.	**P1**, SC - 1.2, ŠC - 1.2.2
			Zvýšenie kapacity triedeného zberu, zavedením zberu biologicky rozložiteľného kuchynského odpadu na území mesta Prešov	572 086,84 €		
2.7.3	Podpora biologickej a krajinnej diverzity a kvality ekosystémových služieb prostredníctvom udržovania a budovania zelenej a modrej infraštruktúry a prevencie a manažmentu inváznych nepôvodných druhov	626 628,99	Park na Masarykovej ulici	100 000,00 €	Mesto Prešov	**P1, SC - 1.2, ŠC - 1.2.1**
			Koncept zelených okruhov mestom Prešov	170 000,00 €	Mesto Prešov	**P1, SC - 1.2, ŠC - 1.2.1**
2.7.4	Podpora budovania prvkov zelenej a modrej infraštruktúry v obciach a mestách	4 053 405,26	Záhrada umenia, Kmeťovo stromoradie Prešov	4 512 799,48 €	Mesto Prešov	**P1, SC - 1.2, ŠC - 1.2.1**
2.8.1	Rozvoj verejnej dopravy	14 882 438,60	Nové trolejové vedenie Rusínska - Kuzmányho	5 228 925,66 €	Mesto Prešov	**P1, SC - 1.1, ŠC - 1.1.1**
			Nové trolejové vedenie Obratisko Lev.-Clementisova	1 212 579,85 €	Mesto Prešov	**P1, SC - 1.1, ŠC - 1.1.1**
			Nové trolejové vedenie Obratisko pod Šalgovíkom	1 886 806,04 €	Mesto Prešov	**P1, SC - 1.1, ŠC - 1.1.1**
			Nová meniareň Solivarská	5 353 823,30 €	Mesto Prešov	**P1, SC - 1.1, ŠC - 1.1.1**
			Nová meniareň Čapajevova	4 991 115,70 €	Mesto Prešov	**P1, SC - 1.1, ŠC - 1.1.1**
			Nová meniareň Mukačevská	5 032 916,92 €	Mesto Prešov	**P1, SC - 1.1, ŠC - 1.1.1**
			Modernizácia CDS so zameraním na preferenciu VOD	4 000 000,00 €	Mesto Prešov	**P1, SC - 1.1, ŠC - 1.1.1**
			Integrovaná doprava - MHD, SAD, zastávka ul. Levočská	1 500 000,00 €	Mesto Prešov	**P1, SC - 1.1, ŠC - 1.1.1**
2.8.2	Podpora cyklodopravy	2 349 858,73	Cyklistická infraštruktúra	2 000 000,00 €	Mesto Prešov	**P1, SC - 1.1, ŠC - 1.1.1**
			Cyklocesta ul. Jesenná - Delňa - IPZ Záborské - 1,5 km		Mesto Prešov	**P1, SC - 1.1, ŠC - 1.1.1**
			Cyklochodník ul. Štúrova - Radlinského - 0,8 km		Mesto Prešov	**P1, SC - 1.1, ŠC - 1.1.1**
			Cyklotrasa Haniska - PP Haniska	1 230 000,00 €	Obec Haniska	**P1, SC - 1.1, ŠC - 1.1.1**
			2. etapa cyklochodníka popri MK2 - Ľubotice	500 000,00 €	Obec Ľubotice	**P1, SC - 1.1, ŠC - 1.1.1**
			Cyklocesta IPZ/Záborské, CYKLOCESTA IPZ – I. etapa	497 000,00 €	Obec Záborské	**P1, SC - 1.1, ŠC - 1.1.1**
3.2.4	Miestne komunikácie	1 078 777,22	Modernizácia miestnych komunikácií	666 804,91 €	Mesto Prešov	**P1, SC - 1.1, ŠC - 1.1.1**
			Rekonštrukcia a modernizácia miest. komunikácií	637 898,88 €	Obec Ľubotice	**P1, SC - 1.1, ŠC - 1.1.1**
RSO4.2	Zlepšenia rovného prístupu k inkluzívnym a kvalitným službám v oblasti vzdelávania, odbornej prípravy a celoživotného vzdelávania rozvíjaním dostupnej infraštruktúry vrátane posilňovania odolnosti pre dištančné a online vzdelávanie a odbornú prípravu	861 614,87	ZŠ Šmeralova - v spojení s prírodou	153 367,29 €	Mesto Prešov	**P2, SC - 2.1, ŠC - 2.1.1**
			ZŠ s MŠ, Nám. Kráľ. pokoja 4, Prešov - v spojení s prírodou	305 476,78 €	Mesto Prešov	**P2, SC - 2.1, ŠC - 2.1.1**
			ZŠ Sibírska - v spojení s prírodou	232 401,37 €	Mesto Prešov	**P2, SC - 2.1, ŠC - 2.1.1**
			ZŠ Šrobárova - v spojení s prírodou	233 590,28 €	Mesto Prešov	**P2, SC - 2.1, ŠC - 2.1.1**
			ZŠ Mirka Nešpora - v spojení s prírodou	316 758,03 €	Mesto Prešov	**P2, SC - 2.1, ŠC - 2.1.1**
			Dostupnosť - Inklúzia - Kvalita ZŠ v Ľuboticiach	500 000,00 €	Obec Ľubotice	**P2, SC - 2.1, ŠC - 2.1.1**

PROGRAM SLOVENSKO		zdroj EFRR	PROJEKTY UMR Prešov			
Kód opatrenia	Názov opatrenia		Názov projektu	Finančná náročnosť	Nositeľ projektu	Väzba na spoločný PHRSR UMR Prešov
RSO4.3	Podpora sociálno-ekonomického začlenenia marginalizovaných komunít, domácností s nízkym príjmom a znevýhodnených skupín vrátane osôb s osobitnými potrebami prostredníctvom integrovaných akcií vrátane bývania a sociálnych služieb	1 276 783,99				**P2, SC - 2.1, ŠC - 2.1.1**
RSO4.5	Zabezpečenia rovného prístupu k zdravotnej starostlivosti a zvýšením odolnosti systémov zdravotnej starostlivosti vrátane primárnej starostlivosti, a podpory prechodu z inštitucionálnej starostlivosti na rodinnú a komunitnú starostlivosť (MPSVR SR)	215 403,72	Bližšie ku komunite	254 900,00 €	Mesto Prešov	**P2, SC - 2.1, ŠC - 2.1.1**
5.1.1	Investície do rozvoja administratívnych a analyticko-strategických kapacít miestnych a regionálnych samospráv a mimovládnych neziskových organizácií pôsobiacich v komunite alebo partnerov pôsobiacich v komunite	313 314,50	KAPA - kapacity pre partnerstvá a participáciu	252 000,00 €	Mesto Prešov ÚSV ROS	**P3, SC - 3.1, ŠC - 3.1.1**
5.1.2	Investície zvyšujúce kvalitu verejných politík a odolnosť demokracie prostredníctvom projektov spolupráce v komunite občianskej spoločnosti a komunity partnerov a samosprávy, prípadne intervenčné projekty v komunite občianskej spoločnosti a komunity partnerov a samosprávy na zvýšenie kvality verejných politík a odolnosť demokracie	117 492,94	Met.-analyt. jednotka 5.1.1		Mesto Prešov	**P3, SC - 3.1, ŠC - 3.1.1**
5.1.3	Investície do bezpečného fyzického prostredia obcí, miest a regiónov	117 492,94	Obnova, modernizácia a rozvoj Mestského kamer. systému	150 000,00 €	Mesto Prešov	**P2, SC - 2.2, ŠC - 2.2.3**
5.1.4	Investície do regionálnej a miestnej infraštruktúry pre pohybové aktivity, cykloturistiku	1 393 325,23	Pohybom k spájaniu komunít - multišportová zóna Prešov	534 250,86 €	Mesto Prešov	**P2, SC - 2.2, ŠC - 2.2.2**
			Zelený okruh - realizácia		Mesto Prešov	**P2, SC - 2.2, ŠC - 2.2.2**
			Delňa		Mesto Prešov	**P2, SC - 2.2, ŠC - 2.2.2**
			Rekonštrukcia športového areálu ZŠ Ľubotice	913 000,00 €	Obec Ľubotice	**P2, SC - 2.2, ŠC - 2.2.2**
			Zázemie športoviska	500 000,00 €	Obec Haniska	**P2, SC - 2.2, ŠC - 2.2.2**
PROGRAM SLOVENSKO		zdroj EFRR	PROJEKTY UMR Prešov			

Kód opatrenia	Názov opatrenia		Názov projektu	Finančná náročnosť	Nositeľ projektu	Väzba na spoločný PHRSR UMR Prešov
5.1.5A	Investície do kultúrneho a prírodného dedičstva, miestnej a regionálnej kultúry, manažmentu, služieb a infraštruktúry podporujúcich komunitný rozvoj a udržateľný cestovný ruch – Infraštruktúra cestovného ruchu – mestské oblasti	4 308 074,33	Mestské opevnenie hradobný múr - 1. etapa	342 254,46 €	Mesto Prešov	**P3, SC - 3.2, ŠC - 3.2.3**
			Kino Scala - interiér, galerijná činnosť	1 500 000,00 €	Mesto Prešov	**P3, SC - 3.2, ŠC - 3.2.2**
			Príťažlivejšia Haniska	300 000,00 €	Obec Haniska	**P1, SC - 1.2, ŠC - 1.2.1**
5.1.5B	Investície do kultúrneho a prírodného dedičstva, miestnej a regionálnej kultúry, manažmentu, služieb a infraštruktúry podporujúcich komunitný rozvoj a udržateľný cestovný ruch – Podpora ostatnej infraštruktúry spojenej s kultúrnymi a prírodnými aktívami regiónov	795 103,03	Kultúrny pavilón	600 000,00 €	Mesto Prešov	**P3, SC - 3.2, ŠC - 3.2.3**
			Rekonštrukcia nádvoria Čierneho orla	500 000,00 €	Mesto Prešov	**P3, SC - 3.2, ŠC - 3.2.2**
ALOKÁCIA Program Slovensko - SPOLU		**47 830 289,27**		**68 936 420,26 €**		

ZOZNAM OBRÁZKOV, TABULIEK A GRAFOV

OBRÁZKY

Obrázok 1 Ciele agendy 2030 5
Obrázok 2 Vybrané úlohy PREŠOV 2030 6
Obrázok 3 Časová os procesu tvorby PHRSR 13
Obrázok 4 Územie UMR Prešov s vyznačením jadrového územia mesta Prešov 15
Obrázok 5 Okruhy problémov UMR Prešov 17
Obrázok 6 Prioritné oblasti rozvoja a stanovené ciele 26
Obrázok 7 *Hierarchická štruktúra priorít a cieľov stratégie PREŠOV 2030* 27

TABUĽKY

Tabuľka 1 Riadiaci tím 11
Tabuľka 2 Výstupy zo SWOT analýzy 22
Tabuľka 3 Súlad priorít stratégie PREŠOV 2030 s prioritami Programu Slovensko 28
Tabuľka 4 PRIORITA 1 UDRŽATEĽNÉ A ODOLNÉ PROSTREDIE 30
Tabuľka 5 PRIORITA 2 SLUŽBY PRE DÔSTOJNÝ ŽIVOT 35
Tabuľka 6 PRIORITA 3 STRATEGICKÝ ROZVOJ A DOBRÉ SPRAVOVANIE 40
Tabuľka 7 Počet intervencií UMR Prešov podľa priorít a tematických oblastí 46
Tabuľka 8 Plán monitorovania, hodnotenia a aktualizácie stratégie PREŠOV 2030 48
Tabuľka 9 Indikatívny finančný plán stratégie PREŠOV 2030 51
Tabuľka 10 Plán riadenia rizík PHRSR UMR Prešov 53
Tabuľka 11 Vyhodnotenie PHSR obce Haniska 2015 - 2022 55
Tabuľka 12 Sumárne vyhodnotenie PHSR obce Ľubotice na obdobie 2015 - 2023 56
Tabuľka 13 Hodnotenie plnenia prioritných oblastí obec Ľubotice 57
Tabuľka 14 Vyhodnotenie PRM mesta Prešov 2015 - 2020 s výhľadom do roku 2025 58
Tabuľka 15 Vyhodnotenie Programu PHSR obce Záborské na roky 2015 - 2025 60
Tabuľka 16 Zoznam intervencií (aktivít a projektov) na naplnenie cieľov a vízie stratégie PREŠOV 2030 s využitím zdrojov v rámci Programu Slovensko 63
Tabuľka 17 Zoznam použitých skratiek 68

GRAFY

Graf 1 Vyhodnotenie plnenia PHRSR obce Ľubotice podľa prioritných oblastí 56
Graf 2 Vyhodnotenie plnenia aktivít/projektov PRM Prešov podľa prioritných oblastí 59
Graf 3 Vyhodnotenie plnenia aktivít/projektov PRM podľa stavu naplnenia 59
Graf 4 Vyhodnotenie plnenia PHRSR obce Záborské podľa prioritných oblastí 60
Graf 5 Trvalo udržateľný ekonomický rozvoja obce 61
Graf 6 Investície do občianskej infraštruktúry obce 61
Graf 7 Investície do dopravnej a technickej infraštruktúry obce 61
Graf 8 Rozvoj bývania a rast počtu obyv. obce 62
Graf 9 Ochrana životného prostredia 62

ZOZNAM POUŽITÝCH SKRATIEK

Tabuľka 17 Zoznam použitých skratiek

Zoznam použitých skratiek	Význam skratky
AK UMR	Administratívne kapacity udržateľného mestského rozvoja
CDS	Cestná dopravná signalizácia
CO_2	Oxid uhličitý
CR	Cestovný ruch
ČOV	Čistiareň odpadových vôd
DHZ	Dobrovoľný hasičský zbor
DPMP, a.s.	Dopravný podnik mesta Prešov, akciová spoločnosť
EFRR	Európsky fond regionálneho rozvoja
EHMK	Európske hlavné mesto kultúry
EIA	Proces posudzovania vplyvov na životné prostredie
EO	Ekvivalentní obyvatelia
ESF+	Európsky sociálny fond +
EŠIF	Európske štrukturálne a investičné fondy
EÚ	Európska únia
FVT, TUKE	Fakulta výrobných technológií, Technická univerzita v Košiciach
GIS	Geografický informačný systém
HZ	Hasičská zbrojnica
IDS	Integrovaný dopravný systém
IKT	Informačné a komunikačné technológie
IoT	Internet vecí (Internet of things)
IPZ	Industriálny park Záborské
ITMS	IT MONITOROVACÍ SYSTÉM
IÚI	Integrovaná územná investícia
IÚS	Integrovaná územná stratégia
k.ú.	Katastrálne územie
KAPA	Kapacity pre partnerstvá a participáciu
KKP	Kultúrny kreatívny priemysel
KR UMR	Kooperačná rada územia udržateľného mestského rozvoja
KURS	Koncepcia územného rozvoja Slovenska
MAS	Miestna akčná skupina
MH SR	Ministerstvo hospodárstva Slovenskej republiky
MHD	Mestská hromadná doprava
MIP	Miestne inovačné partnerstvo
MIRRI SR	Ministerstvo investícií regionálneho rozvoja a informatizácie Slovenskej republiky
MIS	Mestská inovačná stratégia
MK	Miestna komunikácia
MPSVaR SR	Ministerstvo práce sociálnych vecí a rodiny Slovenskej republiky
MSP	Malé stredné podniky
MsP	Mestská polícia
MsÚ	Mestský úrad

Zoznam použitých skratiek	Význam skratky
MsZ	Mestské zastupiteľstvo
MŠ	Materská škola
MVO	Mimovládna organizácia
MŽP SR	Ministerstvo životného prostredia Slovenskej republiky
n.o.	Nezisková organizácia
NDS	Národná diaľničná spoločnosť
NPRVV	Národný program rozvoja výchovy a vzdelávania
NR SR	Národná Rada Slovenskej republiky
NSRR	Národná stratégia regionálneho rozvoja
OcÚ	Obecný úrad
OcZ	Obecné zastupiteľstvo
OOCR	Oblastná organizácia cestovného ruchu
OZE	Obnoviteľné zdroje energie
P	Priorita
P_SK	Program Slovensko
PD	Projektová dokumentácia
PHRSR	Program hospodárskeho rozvoja a sociálneho rozvoja
PHSR	Program hospodárskeho a sociálneho rozvoja
PP	Priemyselný park
PRM	Program rozvoja mesta
PSK	Prešovský samosprávny kraj
Q	Kvartál
R4	Rýchlostná cesta R4
RIA, n.o.	Rozvojová implementačná agentúra, nezisková organizácia
SAD	Slovenská autobusová doprava
SC	Strategický cieľ
SK	Slovensko
SK RIS 3+	Stratégia výskumu a inovácií pre inteligentnú špecializáciu SR 2021 - 2027
SOPK	Slovenská obchodná a priemyselná komora
SPR	Strategicko plánovací región
SR	Slovenská republika
SSC	Slovenská správa ciest
SÚC PSK	Správa a údržba ciest Prešovského samosprávneho kraja
SWOT analýza	S – silné stránky (strengths) W – slabé stránky (weaknesses) O – príležitosti (opportunities) T – hrozby (threats)
ŠC	Špecifický cieľ
TEN-T	Transeurópska dopravná sieť
TSmP, a.s.	Technické služby mesta Prešov, akciová spoločnosť
UMR	Udržateľný mestský rozvoj
ÚPN	Územný plán
ÚPVII SR	Úrad podpredsedu vlády SR pre investície a informatizáciu
ÚSES	Územný systém ekologickej stability

Zoznam použitých skratiek	Význam skratky
ÚSV ROS	Úrad splnomocnenca vlády pre rozvoj občianskej spoločnosti
ÚV SR	Úrad vlády Slovenskej republiky
VO	Verejné osvetlenie
VOD	Verejná osobná doprava
VÚC	Vyšší územný celok
Z.z.	Zbierka zákonov
ZpS	Zariadenie pre seniorov
ZS	Zdravotná starostlivosť
ZŠ	Základná škola
ZUŠ	Základná umelecká škola
ŽP	Životné prostredie